ශ්‍රී ලංකා ප්‍රජාතාන්ත්‍රික සමාජවාදී ජනරජයේ ගැසට් පත්‍රය

இலங்கைச் சனநாயக சோசலிசக் குடியரசு வர்த்தமானப் பத்திரிகை

අති විශෙෂ அதி விசேஷமானது

අංක 2420/15 - 2025 ජනවාරි මස 21 වැනි අඟහරුවාදා - 2025.01.21

2420/15 ஆம் இலக்கம் - 2025 ஆம் ஆண்டு சனவரி மாதம் 21 ஆந் திகதி செவ்வாய்க்கிழமை

(அரசாங்கத்தின் அதிகாரத்துடன் பிரசுரிக்கப்பட்டது)

பகுதி IV (ஆ): உள்ளூராட்சி

உள்ளூராட்சி அறிவித்தல்கள்

ரம்புக்கனை பிரதேச சபை

1987 ஆம் ஆண்டின் 15 ஆம் இலக்க பிரதேச சபைகள் சட்டத்தின் 24 ஆம் பிரிவுடன் வாசிக்கவேண்டிய, சப்பிரகமுவ மாகாண கௌரவ ஆளுநர் அவர்களினால் 2316/20 ஆம் இலக்க மற்றும் 2023, சனவரி மாதம் 24 ஆம் திகதிய, அதி விஷேட வர்த்தமானிப் பத்திரத்தில் பிரகடனப் படுத்தப்பட்டுள்ள சப்பிரகமுவ மாகாணத்தின் பிரதேச சபைகளினால் பராமரிக்கப்படுகின்ற வீதிகள் மற்றும் குறுகிய ஒழுங்கைகளின் திட்ட வரைபடங்களை தயாரித்தல் மற்றும் பெயர்ப் பட்டியல்களை அட்டவணைப்படுத்தி அறிவித்தல்களை வெளியிடுதல் தொடர்பான கட்டளைகள் தொடரின் மூலம் சப்பிரகமுவ மாகாண பிரதேச சபைகளுக்கு கையளிக்கப்பட்டுள்ள பணிகளுக்கு ஏற்ப, இங்கு கீழே அட்டவணையில் உள்ளடக்கப்பட்டுள்ள வீதிகள் மற்றும் குறுகிய ஒழுங்கைகள் ரம்புக்கனை பிரதேச சபைக்கு உரித்தாகியுள்ள வீதிகள் மற்றும் குறுகிய ஒழுங்கைகளாக பிரகடனப்படுத்தப்படுதல் வேண்டுமென 2024.12.30 ஆம் திகதிய 2024/12/30/63 ஆம் இலக்க செயலாளர் தீர்மானத்தின் கீழ் தீர்மானிக்கப்பட்டுள்ளதாக பொதுமக்கள் அறிந்துகொள்வதற்காக இத்தால் பிரசித்தப்படுகின்றது.

குறித்த அட்டவணையில் உள்ளடக்கப்பட்டுள்ள ஏதேனுமொரு வீதியொன்று அல்லது குறுகிய ஒழுங்கையொன்று ஏதேனுமொரு காணியொன்றினூடாக அல்லது ஏதேனுமொரு காணியொன்றின் ஒரு பகுதிக்கு உட்படுவதாக, குறித்த காணிக்கு உரித்துக் கூறுகின்ற தரப்பினரின் கருத்தாக இருப்பின், குறித்த காணிக்கு தமக்கு உள்ள உரித்தினை உறுதிப்படுத்துவதற்காக இவ் அறிவித்தல் வெளியிடப்பட்ட திகதி தொடக்கம் மூன்று மாத கால எல்லை முடிவடைவதற்கு முன் உரிய நீதி மன்றமொன்றில் வழக்கொன்றை தாக்கல் செய்வதற்கு நடவடிக்கைகளை மேற்கொள்ளுதல் வேண்டுமெனவும் இத்தால் அறிவித்தல்

செய்யப்படுகின்றது மேலும் அவ்வாறே, குறித்த மூன்று மாத காலம் முடிவுறுவதற்கு முன் அவ்வாறான வழக்கொன்று தாக்கல் செய்யப்படாத குறித்த அட்டவனணயில் உட்படுத்தப்பட்டுள்ள அனைத்து வீதிகளும் மற்றும் குறுகிய ஒழுங்கைகளும் ரம்புக்கனை பிரதேச சபைக்கு உரித்தாக்கப்பட்ட வீதியொன்றாக அல்லது குறுகிய ஒழுங்கை ஒன்றாக கருதப்படுமெனவும் மேலும் இத்தால் அறிவித்தல் செய்யப்படுகின்றது.

ஆர். ஜீ. எஸ். நிரோஷன்,
செயலாளர் மற்றும் தத்துவங்கள்,
பணிகளை செயற்படுத்தும் அலுவலர்.
ரம்புக்கனை பிரதேச சபை.

பிரதேச சபை அலுவலகம்,
ரம்புக்கனை,
2024, திசெம்பர் 31.

மூன்றாம் அட்டவணை

8 ஆம் பிரிவு

தொ. இல.	வீதியின் குறியீடு	வீதியின் பெயர்	ஆரம்ப அமைவிடப் புள்ளி (கந்தவல ஸ்ரீலங்கா) இடது	ஆரம்ப அமைவிடப் புள்ளி (கந்தவல ஸ்ரீலங்கா) வலது	இறுதி அமைவிடப் புள்ளி (கந்தவல ஸ்ரீலங்கா) இடது	இறுதி அமைவிடப் புள்ளி (கந்தவல ஸ்ரீலங்கா) வலது	வீதியின் நீளம் (மீற்றர்)	வீதியின் அகலம் (மீற்றர்)	அபிவிருத்தி செய்யப் பட்ட அகலம் (மீற்றர்)
1	SG/RPS/A001/1	வலகடயாவயிலிருந்து அத்தனகொட வரையிலான வீதி	227271.682, 160766.238	227271.891, 160763.447	227221.641, 160192.680	227222.755, 160190.221	798.3	2.7	2.5
2	SG/RPS/A001/1/1	சுரஸ உயன வீதி	227336.275, 160607.785	227334.280, 160610.164	227440.526, 160519.606	227442.148, 160522.129	481.08	3	2.5
3	SG/RPS/A001/1/2	சுரஸ உயன முதலாம் ஒழுங்கை	227390.688, 160601.224	227393.923, 160600.410	227374.726, 160526.931	227377.724, 160527.038	88.39	3	2.7
4	SG/RPS/A001/1/2	கஸ்தூரி உயன வீதி	227246.957, 160200.416	227252.102, 160203.509	227433.739, 160166.499	227433.184, 160171.468	201.43	5	2.5
5	SG/RPS/A001/02	ரம்புக்பொதவத்த வீதி	228085.869, 160373.931	228083.941, 160378.005	228357.019, 160342.264	228361.569, 160343.463	392.62	4.5	3.1
6	SG/RPS/A001/2/1	கம்பிஹேன வீதி	228099.220, 160426.517	228097.640, 160427.864	228108.431, 160593.732	228107.344, 160592.053	220.57	2	2
7	SG/RPS/A001/2/1/1	கம்பிஹேன துணை வீதி 2	227838.024, 160644.394	227835.449, 160646.987	227860.420, 160738.513	227856.953, 160737.546	104.32	3.6	3.6

தொ. இல.	வீதியின் குறியீடு	வீதியின் பெயர்	ஆரம்ப அமைவிடப் புள்ளி (கந்தவல ஸ்ரீலங்கா) இடது	ஆரம்ப அமைவிடப் புள்ளி (கந்தவல ஸ்ரீலங்கா) வலது	இறுதி அமைவிடப் புள்ளி (கந்தவல ஸ்ரீலங்கா) இடது	இறுதி அமைவிடப் புள்ளி (கந்தவல ஸ்ரீலங்கா) வலது	வீதியின் நீளம் (மீற்றர்)	வீதியின் அகலம் (மீற்றர்)	அபிவிருத்தி செய்யப் பட்ட அகலம் (மீற்றர்)
8	SG/RPS/A001/2/1/2	கம்பிஹேன 1 ஆம் ஒழுங்கை	228097.640, 160427.864	228096.571, 160424.986	227808.236, 160731.255	227806.750, 160733.862	564.19	3	3
9	SG/RPS/A001/2/2	ரம்புக்பொதவத்த 3 ஆம் ஒழுங்கை 1 ஆம் பகுதி	228166.073, 160388.158	228163.070, 160391.755	228202.267, 160438.713	228200.777, 160442.209	121.9	3.8	3.8
10	SG/RPS/A001/2/2/1	ரம்புக்பொதவத்த 3 ஆம் ஒழுங்கை 2 ஆம் பகுதி	228217.915, 160394.068	228218.777, 160396.522	228429.568, 160418.228	228427.155, 160419.196	225.86	2.6	2.6
11	SG/RPS/A001/2/3	ரம்புக்பொதவத்த 2 ஆம் ஒழுங்கை	228250.507, 160343.851	228249.667, 160339.500	228235.837, 160392.306	228231.424, 160392.180	62.37	4.4	4.4
12	SG/RPS/A001/2/4	ரம்புக்பொதவத்த 1 ஆம் ஒழுங்கை	228279.941, 160355.609	228285.338, 160356.687	228478.498, 160332.259	228480.788, 160337.259	225.12	5.5	5.5
13	SG/RPS/A001/3	மயான பூமி வீதி	228069.075, 160380.745	228070.592, 160377.948	227992.737, 160392.440	227992.739, 160389.440	92.51	3	2.4
14	SG/RPS/A001/4	உடதெனிய வத்த வீதி	228094.527, 160297.463	228095.740, 160292.810	227564.086, 160340.281	227568.872, 160339.916	685.88	4.8	3
15	SG/RPS/A001/5	தலரம்பே கம மெத வீதி	228126.110, 160119.845	228127.253, 160115.198	227757.719, 160175.514	227754.230, 160172.364	455.43	4.7	2.5

தொ. இல.	வீதியின் குறியீடு	வீதியின் பெயர்	ஆரம்ப அமைவிடப் புள்ளி (கந்தவல ஸ்ரீலங்கா) இடது	ஆரம்ப அமைவிடப் புள்ளி (கந்தவல ஸ்ரீலங்கா) வலது	இறுதி அமைவிடப் புள்ளி (கந்தவல ஸ்ரீலங்கா) இடது	இறுதி அமைவிடப் புள்ளி (கந்தவல ஸ்ரீலங்கா) வலது	வீதியின் நீளம் (மீற்றர்)	வீதியின் அகலம் (மீற்றர்)	அபிவிருத்தி செய்யப் பட்ட அகலம் (மீற்றர்)
16	SG/RPS/A001/6	ஹுணுகலே வத்த வீதி	228183.476, 159972.351	228182.249, 159975.635	228468.998, 160022.380	228470.701, 160025.438	323.09	3.5	3.5
17	SG/RPS/A001/7	ஏகம்முல்ல வீதி	228189.592, 159882.953	228189.890, 159878.925	227734.288, 160017.029	227737.763, 160016.610	624.11	3.5	3.5
18	SG/RPS/A001/8	ஏகம்முல்ல வீதி	228208.849, 159821.029	228208.514, 159824.815	228527.288, 159846.407	228524.444, 159848.927	347.18	3.8	2.8
19	SG/RPS/A001/8/1	ஹுணுகலே உனகஹவத்த வீதி 2	228430.290, 159822.982	228426.920, 159821.632	228654.128, 160203.473	228652.508, 160199.816	733.8	4	2.9
20	SG/RPS/A001/9	குருதியவல வீதி	228201.029, 159756.101	228201.297, 159753.716	228052.047, 159666.549	228051.249, 159664.285	249.09	2.4	2.4
21	SG/RPS/A001/10	பன்சல் வத்த வீதி மங்கலகம	228258.321, 159593.969	228258.979, 159591.933	228022.398, 159634.755	228020.887, 159633.155	291.4	2.2	2
22	SG/RPS/A001/10/1	பன்சல் வத்த மங்கலகம 1 ஆம் ஒழுங்கை	228150.801, 159594.301	228148.827, 159595.306	228158.510, 159643.577	228157.400, 159641.795	68.08	2.1	2.1
23	SG/RPS/A001/11	மங்கலகம மஹகொட வீதி	228284.007, 159543.123	228282.997, 159547.104	229568.159, 159133.380	229571.642, 159135.346	1676.43	4	2.5

தொ. இல.	வீதியின் குறியீடு	வீதியின் பெயர்	ஆரம்ப அமைவிடப் புள்ளி (கந்தவல ஸ்ரீலங்கா) இடது	ஆரம்ப அமைவிடப் புள்ளி (கந்தவல ஸ்ரீலங்கா) வலது	இறுதி அமைவிடப் புள்ளி (கந்தவல ஸ்ரீலங்கா) இடது	இறுதி அமைவிடப் புள்ளி (கந்தவல ஸ்ரீலங்கா) வலது	வீதியின் நீளம் (மீற்றர்)	வீதியின் அகலம் (மீற்றர்)	அபிவிருத்தி செய்யப் பட்ட அகலம் (மீற்றர்)
24	SG/RPS/A001/11/1	கல்லென வத்த வீதி	228330.111, 159560.030	228326.894, 159559.431	228509.812, 159740.573	228507.183, 159739.127	346.29	3	2.5
25	SG/RPS/A001/11/2	வேகன்தலே வீதி	228780.335, 159481.469	228777.355, 159480.849	229297.116, 160193.292	229295.715, 160195.945	1020.31	3	2.5
26	SG/RPS/A001/12	இஹல வராகொட அத்தனகொட வீதி	228282.817, 159501.651	228283.635, 159498.764	227190.499, 159587.867	227189.707, 159584.974	1287.67	3	2.4
27	SG/RPS/A001/12/1	வராகொட அம்புழுகல வீதி	227896.940, 159467.549	227899.638, 159467.218	227983.450, 158947.953	227985.552, 158949.705	621.04	2.7	2.4
28	SG/RPS/A001/12/1/1	வராகொட கம மெத வீதி	227919.541, 159121.134	227921.125, 159118.559	227377.033, 159269.769	227375.927, 159266.660	681.8	3.3	2.9
29	SG/RPS/A001/12/1/1/1	பத்தலஹேன வீதி	227767.712, 159173.580	227766.764, 159172.544	227712.471, 159238.460	227711.539, 159237.415	96.07	1.4	1.4
30	SG/RPS/A001/13	ஹெரமிட்டிபான வீதி	228307.621, 159366.186	228308.210, 159363.178	228203.686, 159326.749	228203.570, 159323.751	125.76	3	2.4
31	SG/RPS/A001/14	ஹெரமிட்டிபான வராகொட வீதி	228314.788, 159320.867	228315.355, 159317.612	227972.258, 159458.508	227969.448, 159456.761	510.78	3.3	2.5

தொ. இல.	வீதியின் குறியீடு	வீதியின் பெயர்	ஆரம்ப அமைவிடப் புள்ளி (கந்தவல ஸ்ரீலங்கா) இடது	ஆரம்ப அமைவிடப் புள்ளி (கந்தவல ஸ்ரீலங்கா) வலது	இறுதி அமைவிடப் புள்ளி (கந்தவல ஸ்ரீலங்கா) இடது	இறுதி அமைவிடப் புள்ளி (கந்தவல ஸ்ரீலங்கா) வலது	வீதியின் நீளம் (மீற்றர்)	வீதியின் அகலம் (மீற்றர்)	அபிவிருத்தி செய்யப் பட்ட அகலம் (மீற்றர்)
32	SG/RPS/A001/15	தெமட்டபிட்டிய வீதி	228330.894, 158985.909	228331.279, 158988.885	229317.383, 159191.803	229314.336, 159192.450	1161.11	3	2.5
33	SG/RPS/A001/16	பொக்குணுகல பன்சல வீதி	228317.063, 158971.479	228316.544, 158968.385	227461.612, 158549.002	227462.534, 158546.148	1444.52	3	2.4
34	SG/RPS/A001/16/1	வராகொட வெரழுகொல்ல வீதி	227897.460, 158900.421	227899.954, 158898.444	227920.534, 158526.352	227920.803, 158529.340	485.79	3	3
35	SG/RPS/A001/16/1/1	பரண அக்கரவத்த வீதி	227723.708, 159002.921	227724.166, 159005.721	227875.959, 158775.311	227874.666, 158780.790	553.04	2.7	2.7
36	SG/RPS/A001/16/2	வராகொட பொகுணுகல வீதி 1 ஆம் ஒழுங்கை	227721.779, 159008.186	227721.040, 159005.748	227338.786, 158765.631	227341.010, 158764.728	553.08	2.4	2.4
37	SG/RPS/A001/17	நாகஹமுல வீதி	228267.695, 158742.644	228267.161, 158739.793	228013.858, 158732.291	228015.564, 158730.198	321.77	2.7	2.4
38	SG/RPS/A001/18	கும்பல்திவெல வீதி	228305.207, 158631.947	228303.727, 158636.165	228746.852, 158607.579	228750.690, 158609.454	552.96	4.2	2.8
39	SG/RPS/A001/18/3	பொரழுவ வீதி 2 ஆம் ஒழுங்கை	228954.351, 158696.734	228950.526, 158697.248	229297.986, 158640.653	229300.884, 158641.430	475.87	3	3

தொ. இல.	வீதியின் குறியீடு	வீதியின் பெயர்	ஆரம்ப அமைவிடப் புள்ளி (கந்தவல ஸ்ரீலங்கா) இடது	ஆரம்ப அமைவிடப் புள்ளி (கந்தவல ஸ்ரீலங்கா) வலது	இறுதி அமைவிடப் புள்ளி (கந்தவல ஸ்ரீலங்கா) இடது	இறுதி அமைவிடப் புள்ளி (கந்தவல ஸ்ரீலங்கா) வலது	வீதியின் நீளம் (மீற்றர்)	வீதியின் அகலம் (மீற்றர்)	அபிவிருத்தி செய்யப் பட்ட அகலம் (மீற்றர்)
40	SG/RPS/A001/18/1	கும்பல்திவெல 2 ஆம் ஒழுங்கை	228746.852, 158607.579	228750.690, 158609.454	228798.899, 158612.441	228799.189, 158614.924	101.43	2.5	2.5
41	SG/RPS/A001/18/2	கும்பல்திவெல 1 ஆம் ஒழுங்கை	228741.100, 158633.698	228738.645, 158635.421	228977.475, 158691.394	228977.175, 158694.278	270.21	2.9	2.8
42	SG/RPS/A001/19	வைலப்பிட்டிய வீதி	228323.539, 158237.338	228324.070, 158239.861	228389.295, 158201.367	228390.875, 158203.304	106.25	2.5	2.5
43	SG/RPS/A001/20	கும்பல்திவெல பிரிவென வீதி	228288.525, 158097.372	228289.179, 158099.906	228549.727, 158314.393	228547.273, 158315.252	448.69	2.6	2.6
44	SG/RPS/A001/20/1	கும்பல்திவெல பிரிவென வீதி 1 ஆம் ஒழுங்கை	228557.932, 158135.099	228560.791, 158134.546	228460.264, 158078.724	228458.085, 158076.890	126.47	2.6	2.6
45	SG/RPS/A001/20/1/1	கல்கானே விகாரை அருகில் வீதி	228498.705, 158100.517	228501.765, 158102.971	228573.122, 158067.805	228574.215, 158070.599	116.63	3	3
46	SG/RPS/A001/20/2	கும்பல்திவெல பிரிவென கிட்டிய வீதி	228500.926, 158184.484	228502.579, 158186.879	228628.986, 158108.386	228628.275, 158111.506	160.92	3.2	3.2
47	SG/RPS/A001/21	அரம்பவத்த வீதி	228272.567, 158084.675	228271.691, 158081.804	228200.631, 158090.511	228199.233, 158087.857	85.95	3	2.5

தொ. இல.	வீதியின் குறியீடு	வீதியின் பெயர்	ஆரம்ப அமைவிடப் புள்ளி (கந்தவல ஸ்ரீலங்கா) இடது	ஆரம்ப அமைவிடப் புள்ளி (கந்தவல ஸ்ரீலங்கா) வலது	இறுதி அமைவிடப் புள்ளி (கந்தவல ஸ்ரீலங்கா) இடது	இறுதி அமைவிடப் புள்ளி (கந்தவல ஸ்ரீலங்கா) வலது	வீதியின் நீளம் (மீற்றர்)	வீதியின் அகலம் (மீற்றர்)	அபிவிருத்தி செய்யப் பட்ட அகலம் (மீற்றர்)
48	SG/RPS/A001/22	வத்தேகம கம மெத வீதி	228247.143, 158006.469	228246.283, 158003.584	227790.261, 158091.236	227789.188, 158088.435	555.72	3	2.4
49	SG/RPS/A001/22/1	வத்தேகம கம மெத வீதி 1 ஆம் ஒழுங்கை	228162.190, 157981.928	228163.881, 157984.415	228228.507, 157958.485	228229.617, 157961.367	107.25	3	2.7
50	SG/RPS/A001/23	கவுடாவுல்ல வீதி	228253.331, 157988.595	228255.269, 157993.385	228400.459, 157885.110	228403.624, 157889.109	846.59	5.1	4.2
51	SG/RPS/A001/23/1	கவுடாவுல்ல வீதி 1 ஆம் ஒழுங்கை	228318.408, 157962.157	228320.218, 157959.742	228272.780, 157834.601	228275.012, 157836.605	190.37	3	2
52	SG/RPS/A001/24	புதுமவத்த வீதி	228158.624, 157792.538	228158.514, 157789.537	228054.798, 157799.274	228055.310, 157796.315	115.94	3	2.4
53	SG/RPS/A001/25	புதுமவத்த வீதி	228164.057, 157680.764	228164.211, 157677.768	228136.304, 157678.145	228139.454, 157678.376	734.92	3	2.7
54	SG/RPS/A001/25/1	புதுமவத்த கிணற்றுக்குச் செல்லும் வீதி	228064.981, 157683.251	228067.629, 157682.724	228036.933, 157621.350	228038.431, 157619.103	73.4	2.7	2.7
55	SG/RPS/A001/25/1/1	புதுமவத்த 1 ஆம் ஒழுங்கை 1 ஆம் துணை வீதி	228054.514, 157653.474	228053.506, 157651.551	228014.934, 157670.347	228013.490, 157668.964	43.61	2	2

தொ. இல.	வீதியின் குறியீடு	வீதியின் பெயர்	ஆரம்ப அமைவிடப் புள்ளி (கந்தவல ஸ்ரீலங்கா) இடது	ஆரம்ப அமைவிடப் புள்ளி (கந்தவல ஸ்ரீலங்கா) வலது	இறுதி அமைவிடப் புள்ளி (கந்தவல ஸ்ரீலங்கா) இடது	இறுதி அமைவிடப் புள்ளி (கந்தவல ஸ்ரீலங்கா) வலது	வீதியின் நீளம் (மீற்றர்)	வீதியின் அகலம் (மீற்றர்)	அபிவிருத்தி செய்யப் பட்ட அகலம் (மீற்றர்)
56	SG/RPS/A001/25/2	புதுமவத்த 2 ஆம் ஒழுங்கை	228060.017, 157718.744	228060.580, 157715.710	228001.199, 157720.108	228002.090, 157717.244	61.01	3	3
57	SG/RPS/A001/25/3	புதுமவத்த 3 ஆம் ஒழுங்கை	228055.605, 157766.623	228055.799, 157763.574	228017.490, 157764.026	228017.493, 157761.026	39.59	3	3
58	SG/RPS/A001/26	வேகொலதெனிய வீதி	228135.518, 157547.162	228134.546, 157544.317	227017.162, 158202.770	227016.998, 158199.774	1689.66	3	2.4
59	SG/RPS/A001/26/1	வேகொலதெனிய 2 ஆம் ஒழுங்கை	227932.600, 157553.098	227936.207, 157552.791	227846.677, 157373.140	227848.114, 157370.506	250.37	3	2.4
60	SG/RPS/A001/26/2	வேகொலதெனிய 1 ஆம் ஒழுங்கை	227752.994, 157729.826	227754.507, 157727.168	227680.333, 157648.217	227682.985, 157646.814	112.34	3	3
61	SG/RPS/A001/26/2/1	வேகொலதெனிய போதிய வீதி	227713.288, 157687.566	227715.407, 157689.711	227737.001, 157614.157	227739.971, 157613.735	90.4	3	3
62	SG/RPS/A001/26/3	மொலகொட வேகொலதெனிய வத்த வீதி	227451.653, 158165.528	227449.687, 158167.570	227349.938, 158340.053	227348.370, 158337.496	216.45	3	2.4
63	SG/RPS/A001/27	பொரஸ்ட்ஹில் வீதி	228065.389, 157168.131	228064.836, 157164.077	227076.736, 157427.034	227080.132, 157428.739	1790.7	3.8	2.7
64	SG/RPS/A001/27/1	பொரஸ்ட்ஹில் 1 ஆம் ஒழுங்கை	227501.436, 157640.362	227502.826, 157637.964	227398.696, 157497.136	227398.044, 157494.516	359.8	2.7	2.4

SG-RPS-A001-1-1 -SURASA UYANA ROAD

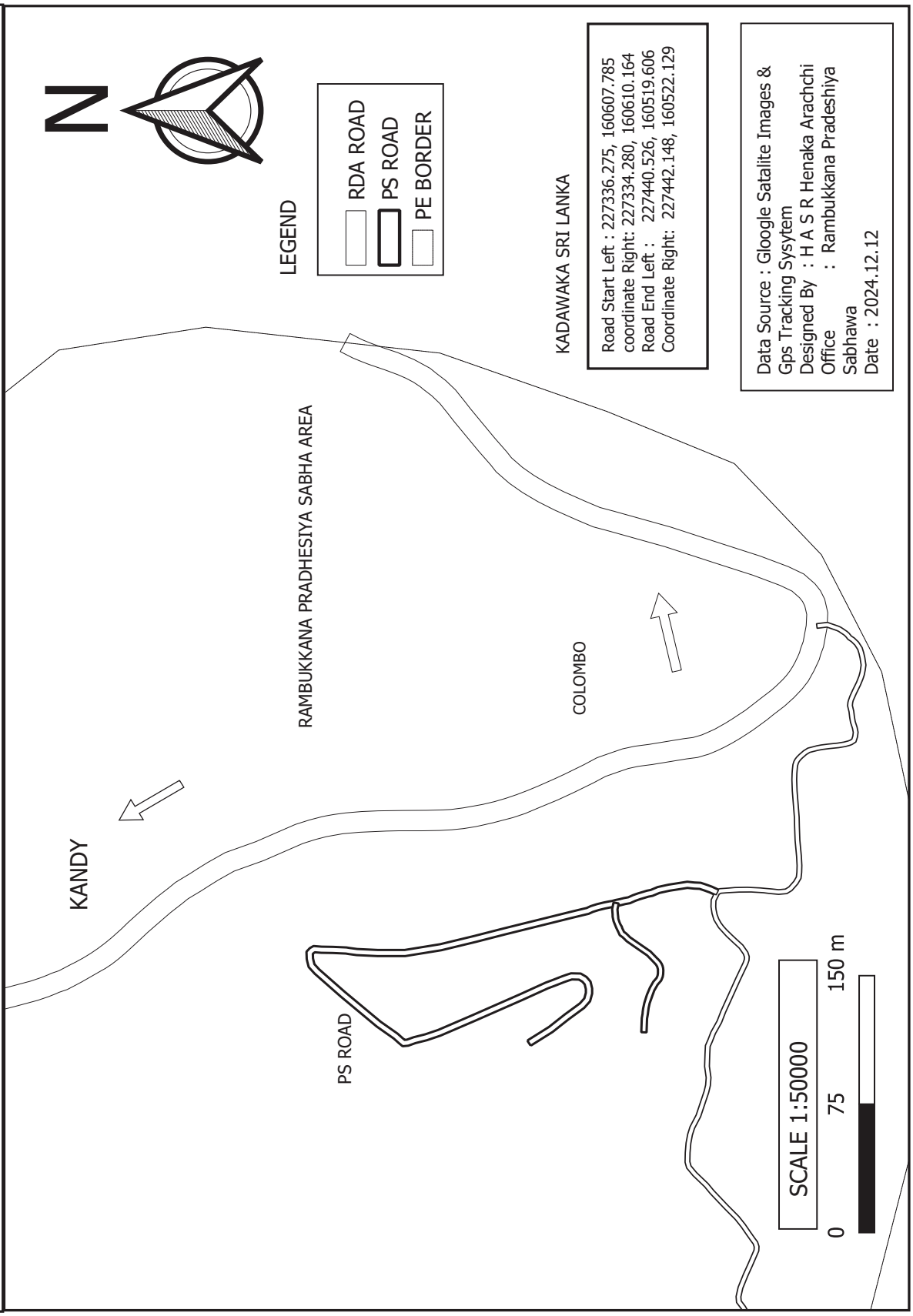

SG/RPS/A001/1/1/1-SURASA UYANA PALAMU PATUMAGA

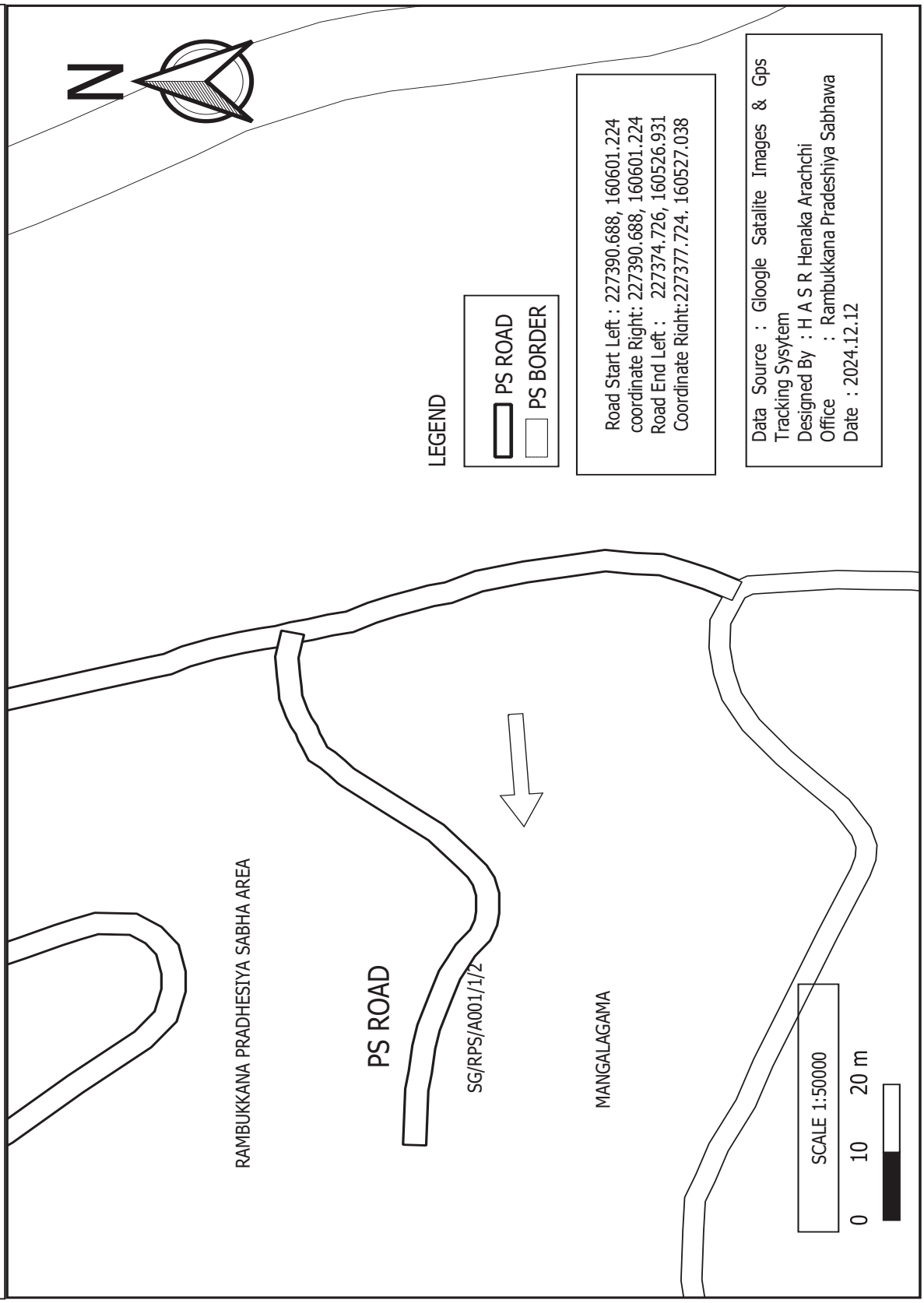

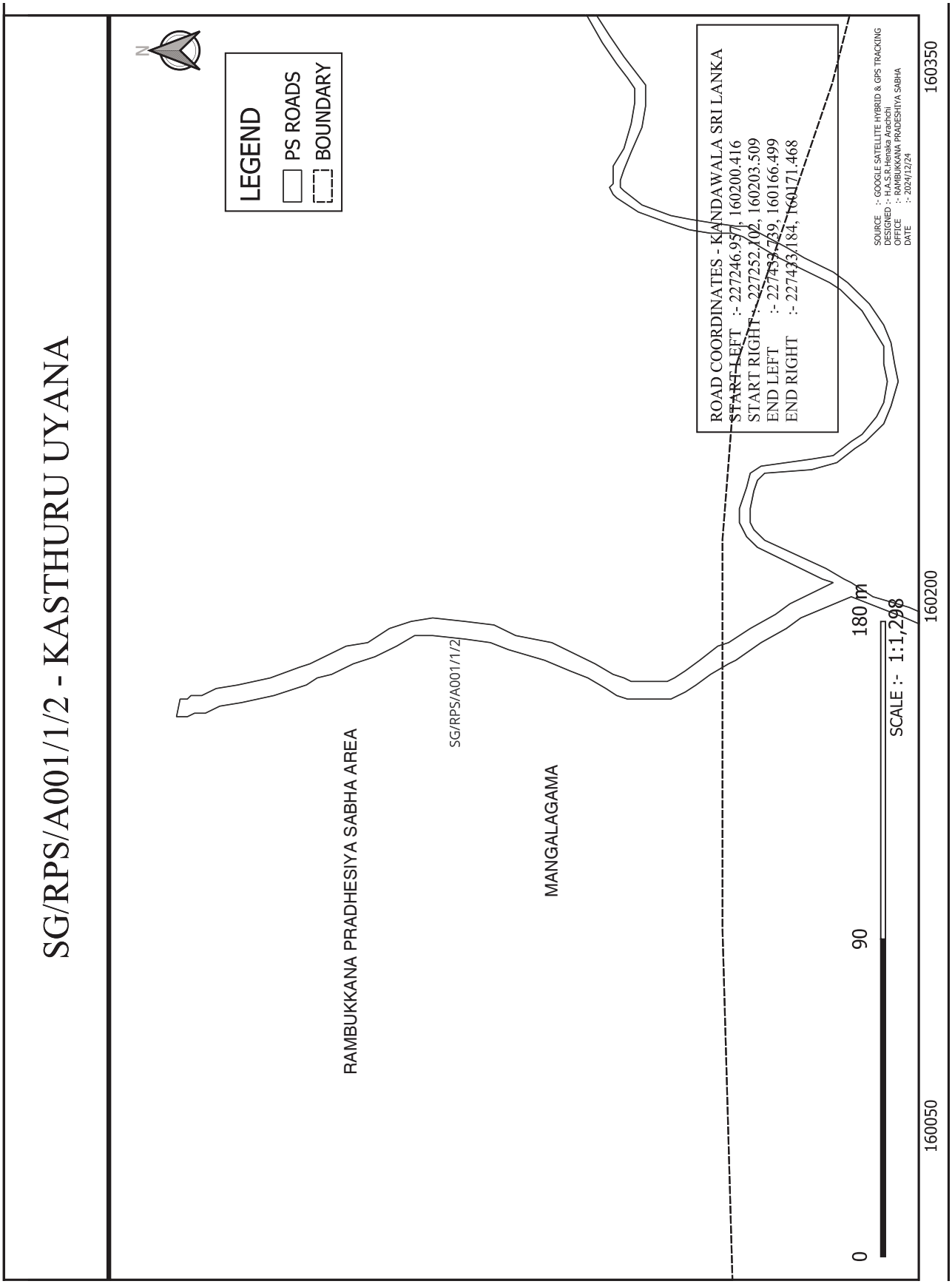
SG/RPS/A001/1/2 - KASTHURU UYANA
LEGEND
PS ROADS
BOUNDARY
ROAD COORDINATES - KANDAWALA SRI LANKA
START LEFT :- 227246.957, 160200.416
START RIGHT :- 227252.702, 160203.509
END LEFT :- 227433.739, 160166.499
END RIGHT :- 227433.184, 160171.468
SOURCE :- GOOGLE SATELLITE HYBRID & GPS TRACKING
DESIGNED :- H.A.S.R.Henaka Arachchi
OFFICE :- RAMBUKKANA PRADESHIYA SABHA
DATE :- 2024/12/24
SCALE :- 1:1,298
0
90
180 m
160050
160200
160350
SG/RPS/A001/1/2
RAMBUKKANA PRADHESIYA SABHA AREA
MANGALAGAMA

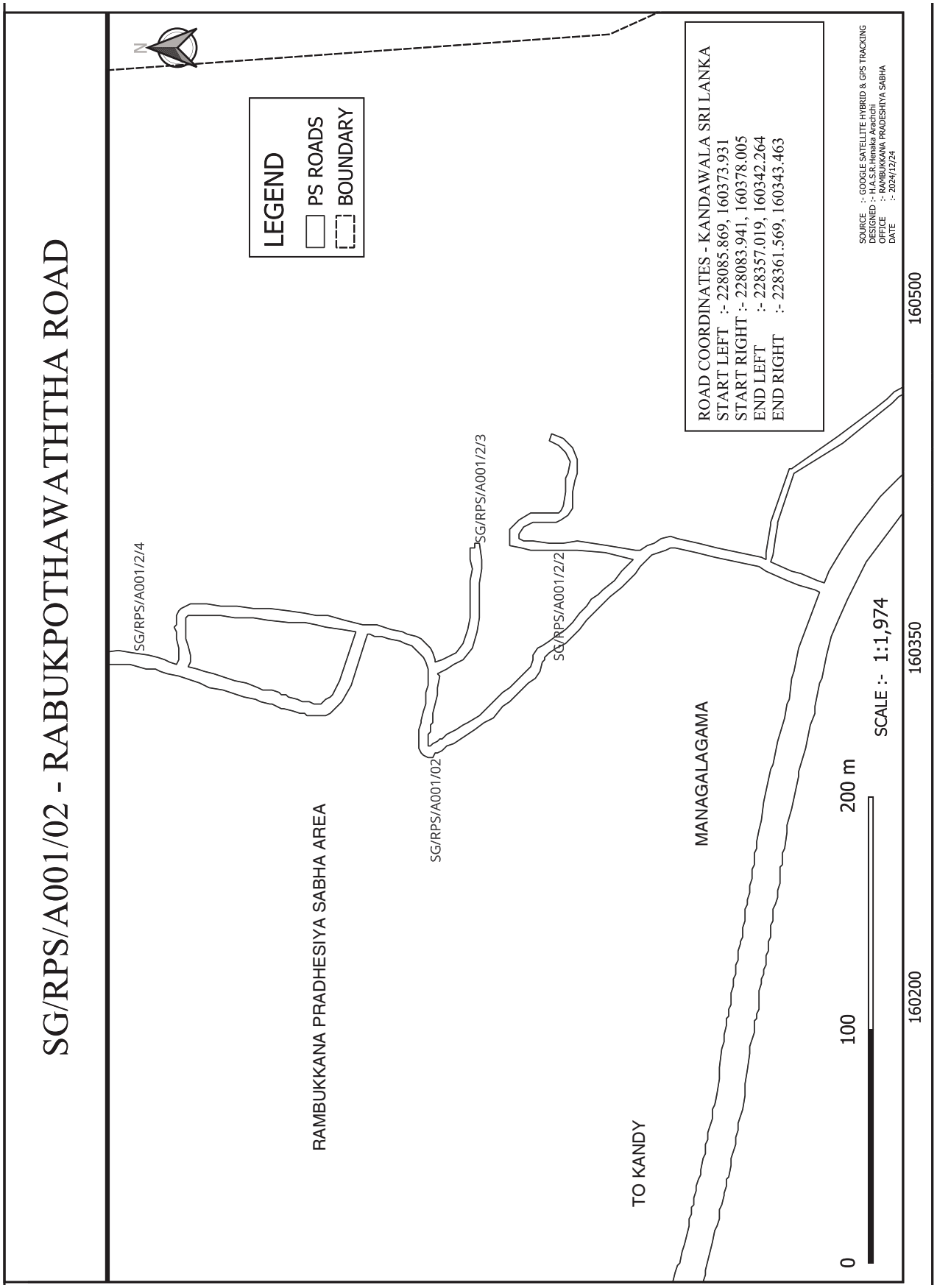
SG/RPS/A001/02 - RABUKPOTHAWATHTHA ROAD
N
LEGEND
PS ROADS
BOUNDARY
ROAD COORDINATES - KANDAWALA SRI LANKA
START LEFT :- 228085.869, 160373.931
START RIGHT :- 228083.941, 160378.005
END LEFT :- 228357.019, 160342.264
END RIGHT :- 228361.569, 160343.463
SOURCE :- GOOGLE SATELLITE HYBRID & GPS TRACKING
DESIGNED :- H.A.S.R.Henaka Arachchi
OFFICE :- RAMBUKKANA PRADESHIYA SABHA
DATE :- 2024/12/24
SG/RPS/A001/2/4
SG/RPS/A001/2/3
SG/RPS/A001/2/2
SG/RPS/A001/02
RAMBUKKANA PRADHESIYA SABHA AREA
MANAGALAGAMA
TO KANDY
SCALE :- 1:1,974
0
100
200 m
160200
160350
160500

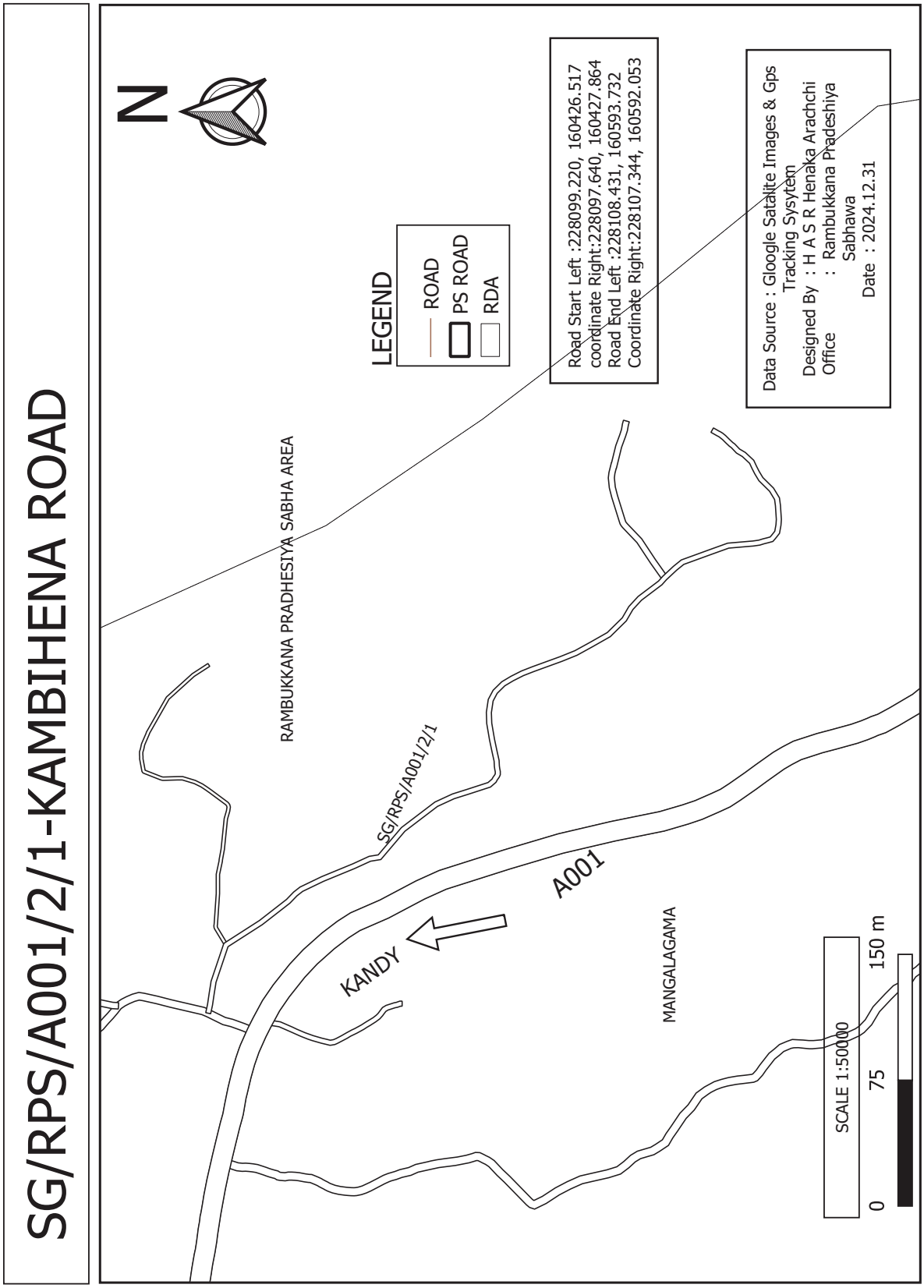
SG/RPS/A001/2/1-KAMBIHENA ROAD
N
LEGEND
ROAD
PS ROAD
RDA
Road Start Left :228099.220, 160426.517
coordinate Right:228097.640, 160427.864
Road End Left :228108.431, 160593.732
Coordinate Right:228107.344, 160592.053
Data Source : Gloogle Satalite Images & Gps Tracking Sysytem
Designed By : H A S R Henaka Arachchi
Office : Rambukkana Pradeshiya Sabhawa
Date : 2024.12.31
RAMBUKKANA PRADHESIYA SABHA AREA
SG/RPS/A001/2/1
A001
KANDY
MANGALAGAMA
SCALE 1:50000
0
75
150 m

SG/RPS/A001/2/1/1-KAMBIHENA ATHURU MARGAYA 1

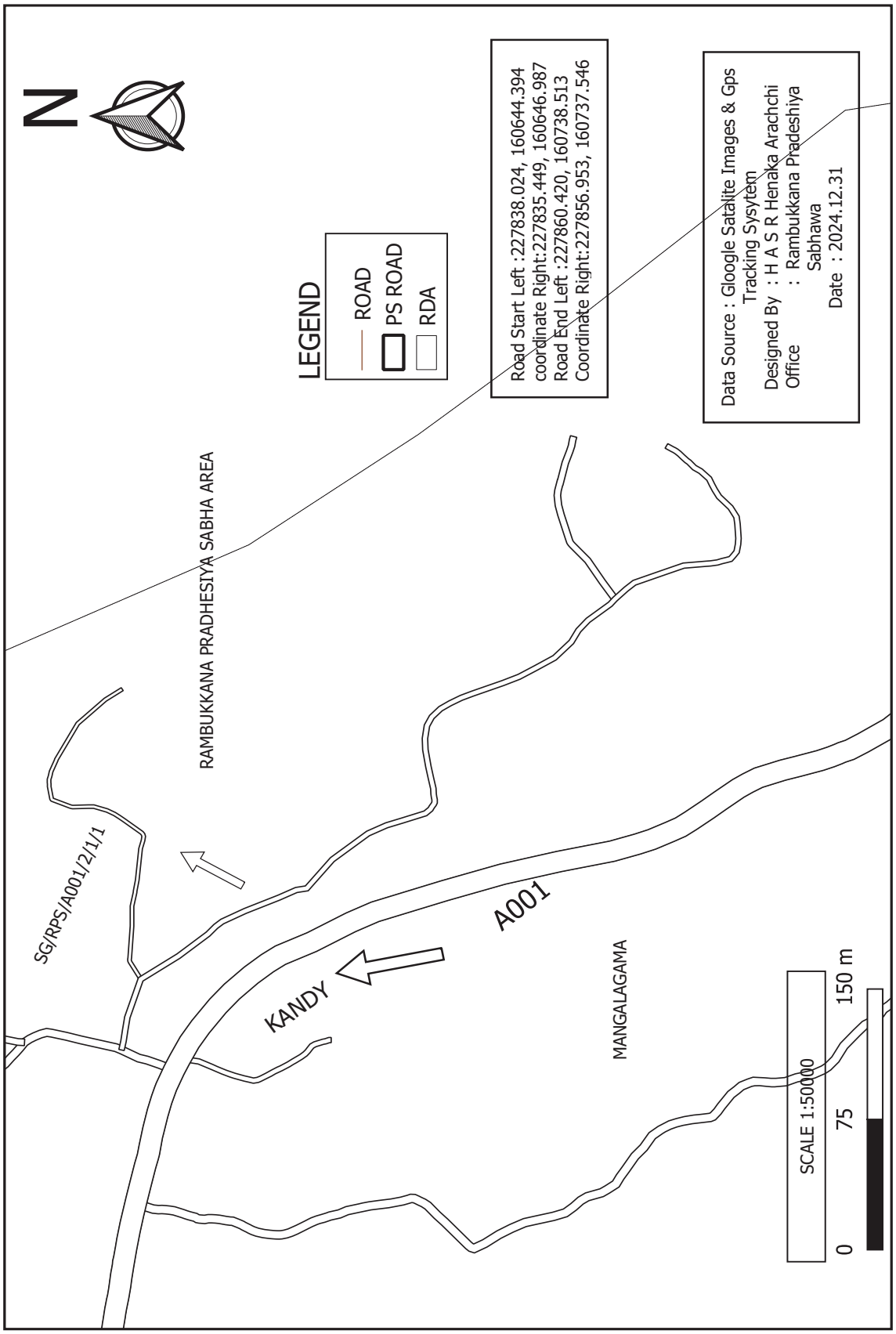

SG/RPS/A001/2/1/2-KAMBIHENA ATHURU MARGAYA 2

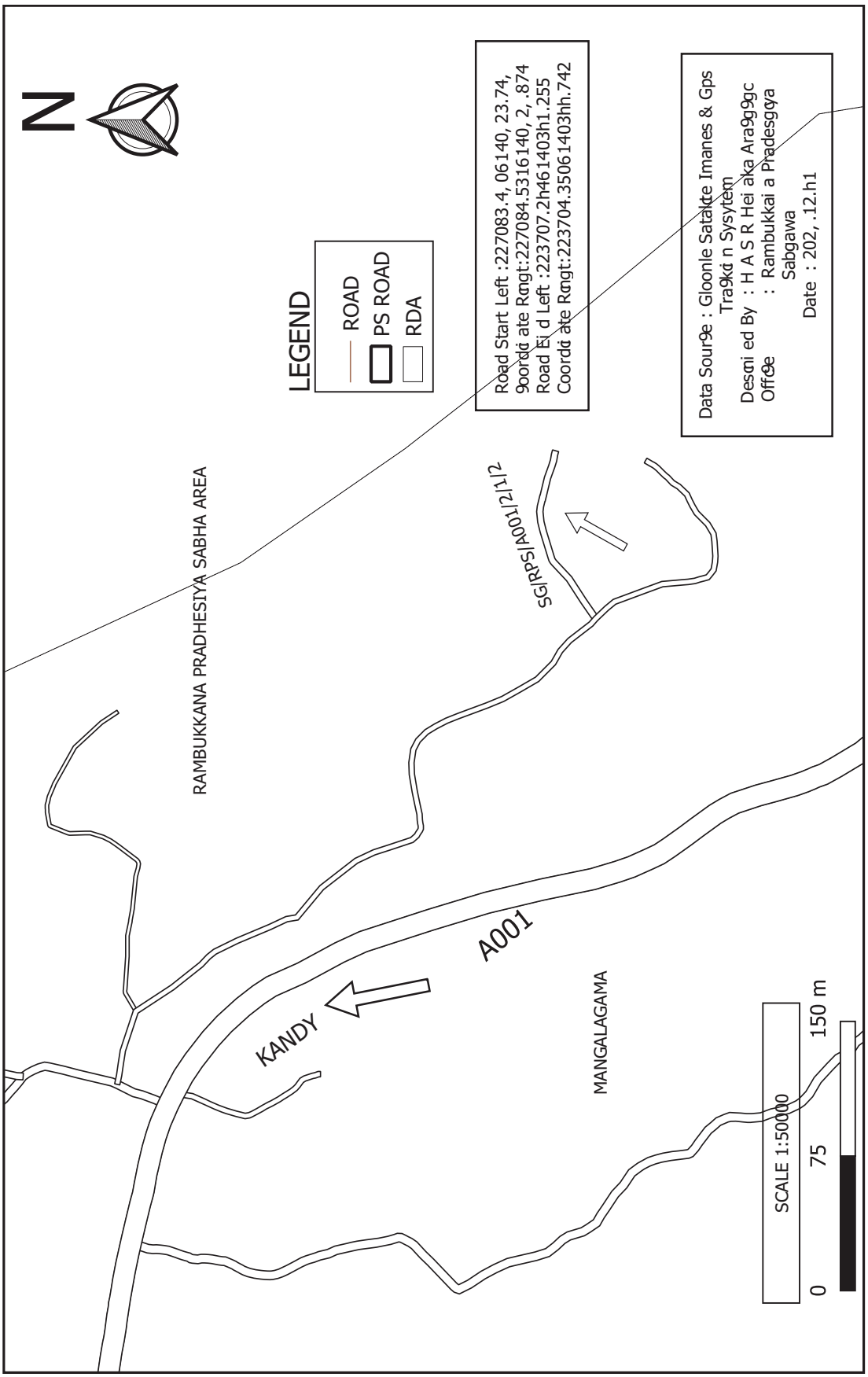

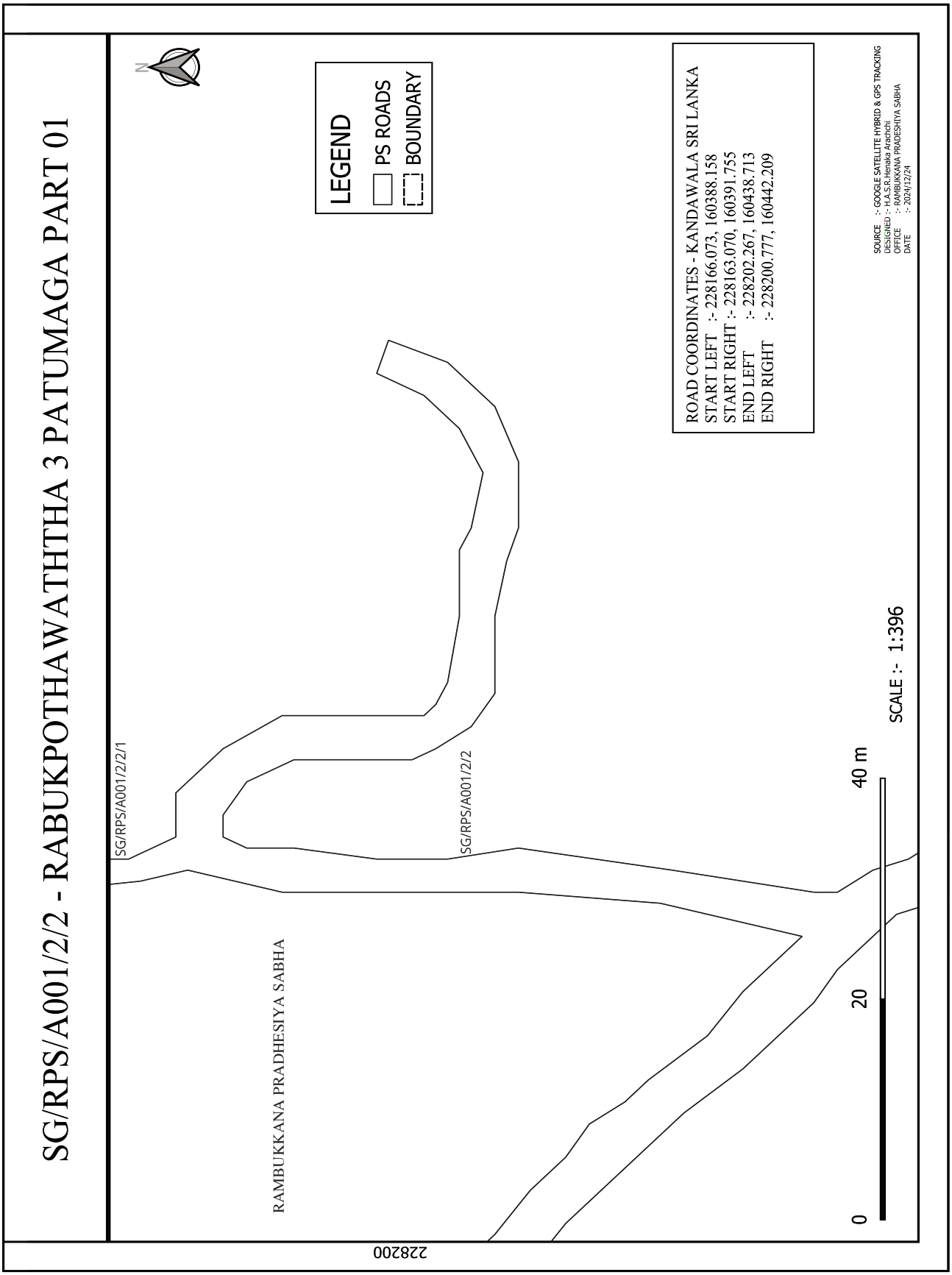
SG/RPS/A001/2/2 - RABUKPOTHAWATHTHA 3 PATUMAGA PART 01
N
LEGEND
PS ROADS
BOUNDARY
ROAD COORDINATES - KANDAWALA SRI LANKA
START LEFT :- 228166.073, 160388.158
START RIGHT :- 228163.070, 160391.755
END LEFT :- 228202.267, 160438.713
END RIGHT :- 228200.777, 160442.209
SOURCE :- GOOGLE SATELLITE HYBRID & GPS TRACKING
DESIGNED :- H.A.S.R.Hemaka Arachchi
OFFICE :- RAMBUKKANA PRADESHIYA SABHA
DATE :- 2024/12/24
SCALE :- 1:396
0
20
40 m
SG/RPS/A001/2/2/1
SG/RPS/A001/2/2
RAMBUKKANA PRADHESIYA SABHA
228200

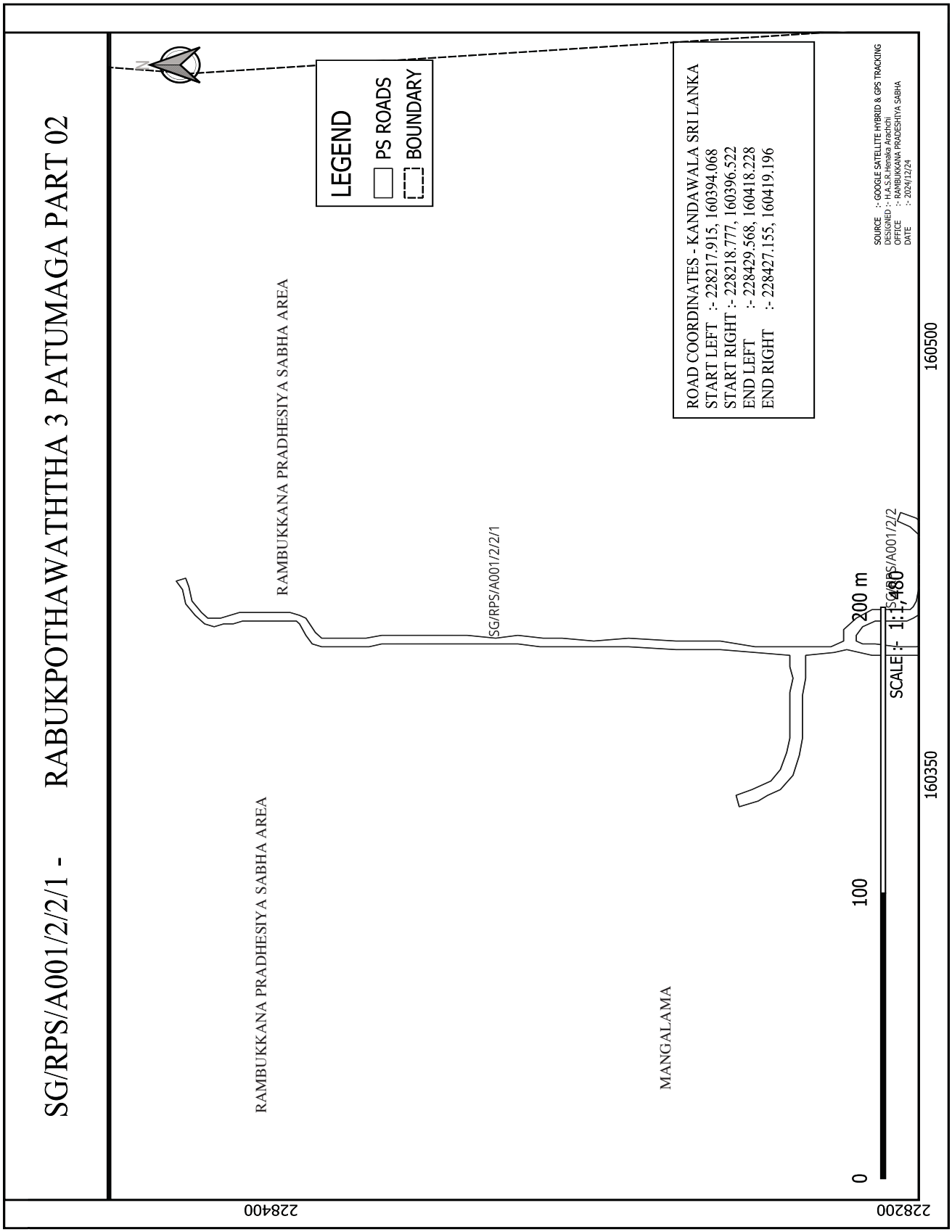
SG/RPS/A001/2/2/1 - RABUKPOTHAWATHTHA 3 PATUMAGA PART 02
LEGEND
PS ROADS
BOUNDARY
ROAD COORDINATES - KANDAWALA SRI LANKA
START LEFT :- 228217.915, 160394.068
START RIGHT :- 228218.777, 160396.522
END LEFT :- 228429.568, 160418.228
END RIGHT :- 228427.155, 160419.196
SOURCE :- GOOGLE SATELLITE HYBRID & GPS TRACKING
DESIGNED :- H.A.S.R.Hensiga Arachchi
OFFICE :- RAMBUKKANA PRADESHIYA SABHA
DATE :- 2024/12/24
RAMBUKKANA PRADHESIYA SABHA AREA
RAMBUKKANA PRADHESIYA SABHA AREA
MANGALAMA
SG/RPS/A001/2/2/1
SG/RPS/A001/2/2
SCALE :- 1:1,480
0
100
200 m
160350
160500
228200
228400

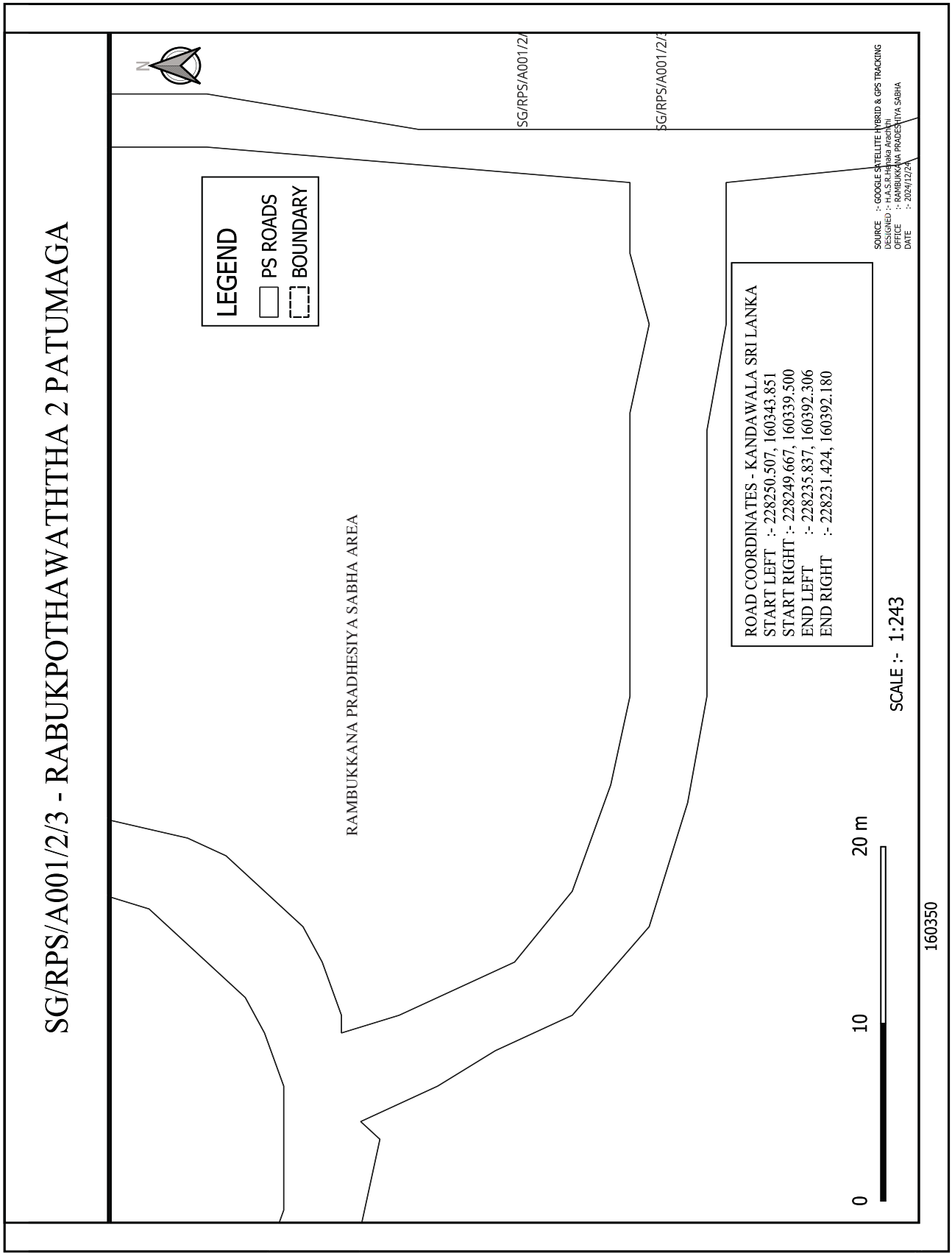
SG/RPS/A001/2/3 - RABUKPOTHAWATHTHA 2 PATUMAGA
N
SG/RPS/A001/2/
SG/RPS/A001/2/3
LEGEND
PS ROADS
BOUNDARY
RAMBUKKANA PRADHESIYA SABHA AREA
ROAD COORDINATES - KANDAWALA SRI LANKA
START LEFT :- 228250.507, 160343.851
START RIGHT :- 228249.667, 160339.500
END LEFT :- 228235.837, 160392.306
END RIGHT :- 228231.424, 160392.180
SCALE :- 1:243
0
10
20 m
160350
SOURCE :- GOOGLE SATELLITE HYBRID & GPS TRACKING
DESIGNED :- H.A.S.R.Hettaka Arachchi
OFFICE :- RAMBUKKANA PRADESHIYA SABHA
DATE :- 2024/12/24

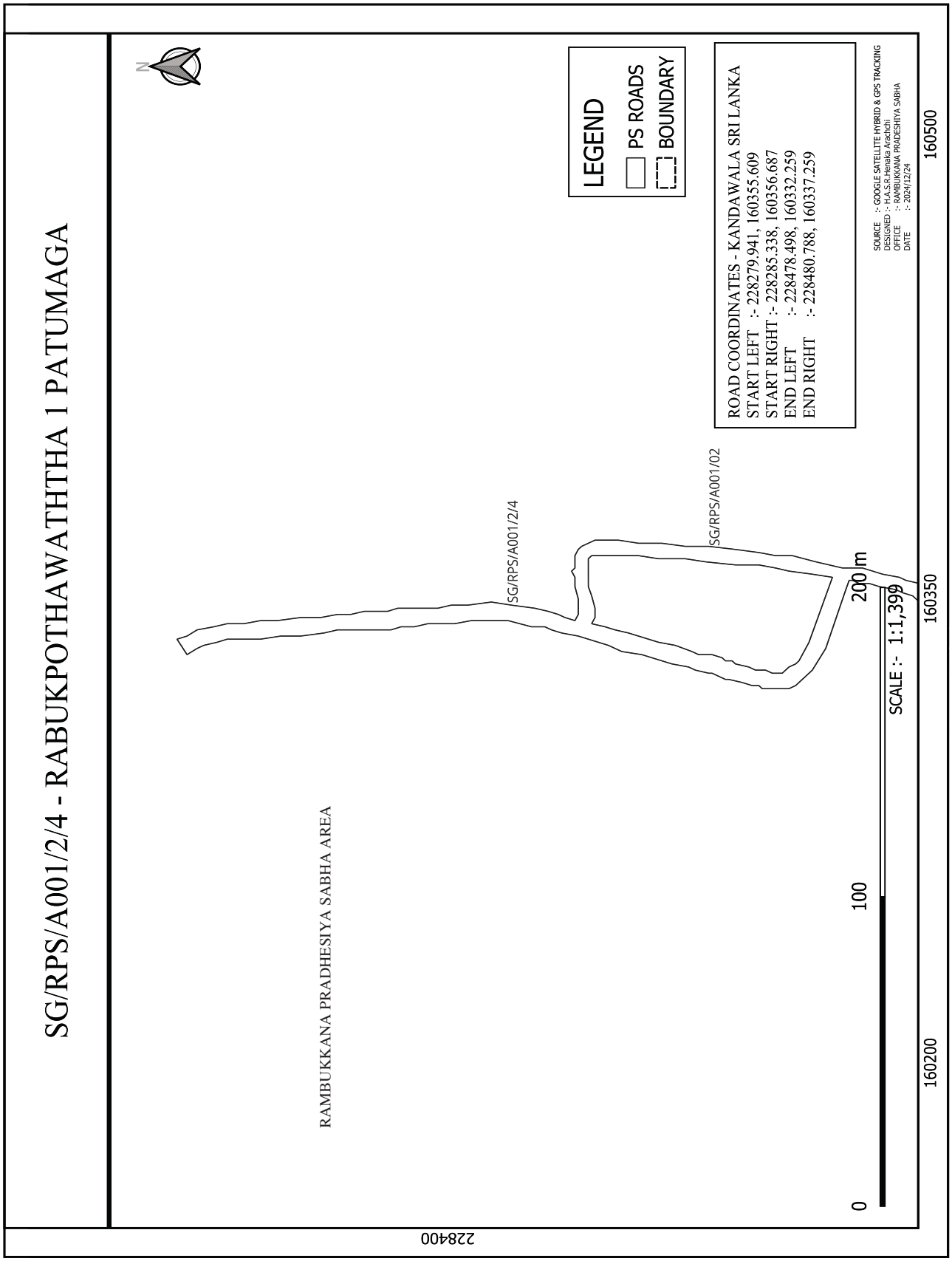
SG/RPS/A001/2/4 - RABUKPOTHAWATHTHA 1 PATUMAGA
N
LEGEND
PS ROADS
BOUNDARY
ROAD COORDINATES - KANDAWALA SRI LANKA
START LEFT :- 228279.941, 160355.609
START RIGHT :- 228285.338, 160356.687
END LEFT :- 228478.498, 160332.259
END RIGHT :- 228480.788, 160337.259
SOURCE :- GOOGLE SATELLITE HYBRID & GPS TRACKING
DESIGNED :- H.A.S.R.Henaka Arachchi
OFFICE :- RAMBUKKANA PRADESHIYA SABHA
DATE :- 2024/12/24
SG/RPS/A001/2/4
SG/RPS/A001/02
RAMBUKKANA PRADHESIYA SABHA AREA
0
100
200 m
SCALE :- 1:1,399
160200
160350
160500
228400

SG/RPS/A001-03/-KANATHTHA ROAD

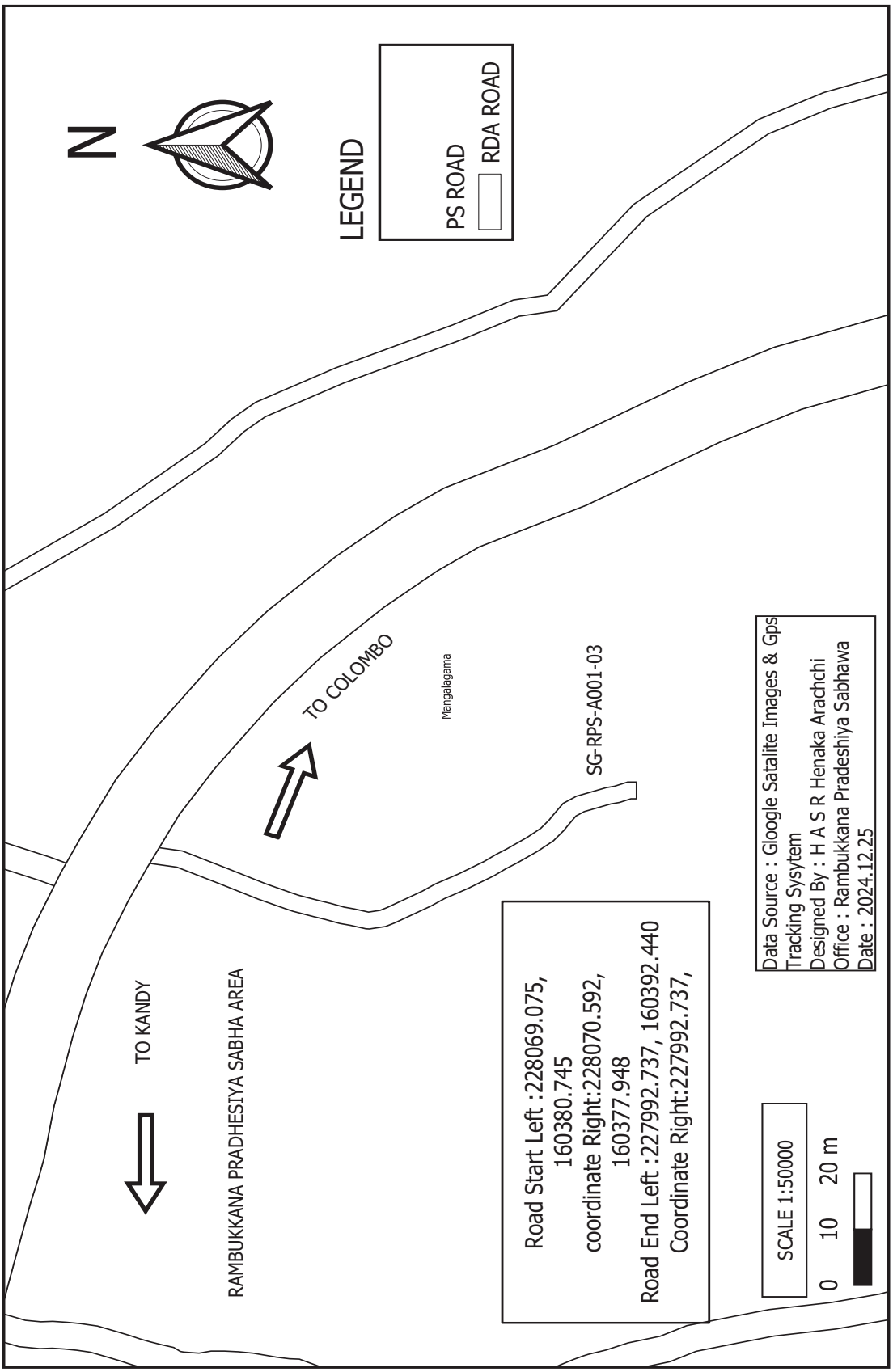

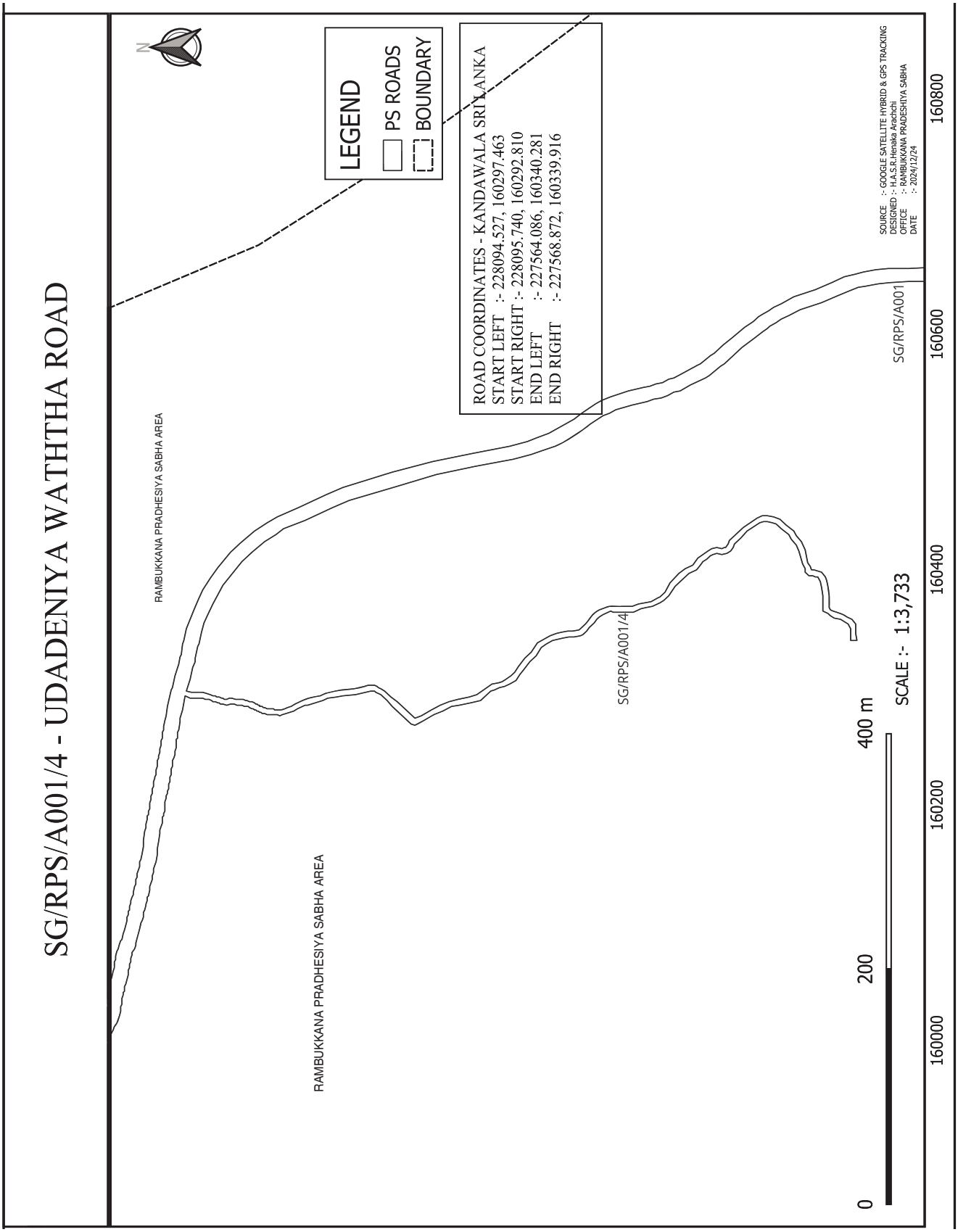
SG/RPS/A001/4 - UDADENIYA WATHTHA ROAD
N
LEGEND
PS ROADS
BOUNDARY
ROAD COORDINATES - KANDAWALA SRI LANKA
START LEFT :- 228094.527, 160297.463
START RIGHT :- 228095.740, 160292.810
END LEFT :- 227564.086, 160340.281
END RIGHT :- 227568.872, 160339.916
SOURCE :- GOOGLE SATELLITE HYBRID & GPS TRACKING
DESIGNED :- H.A.S.R.Henaka Arachchi
OFFICE :- RAMBUKKANA PRADESHIYA SABHA
DATE :- 2024/12/24
RAMBUKKANA PRADHESIYA SABHA AREA
RAMBUKKANA PRADHESIYA SABHA AREA
SG/RPS/A001/4
SG/RPS/A001
0
200
400 m
SCALE :- 1:3,733
160000
160200
160400
160600
160800

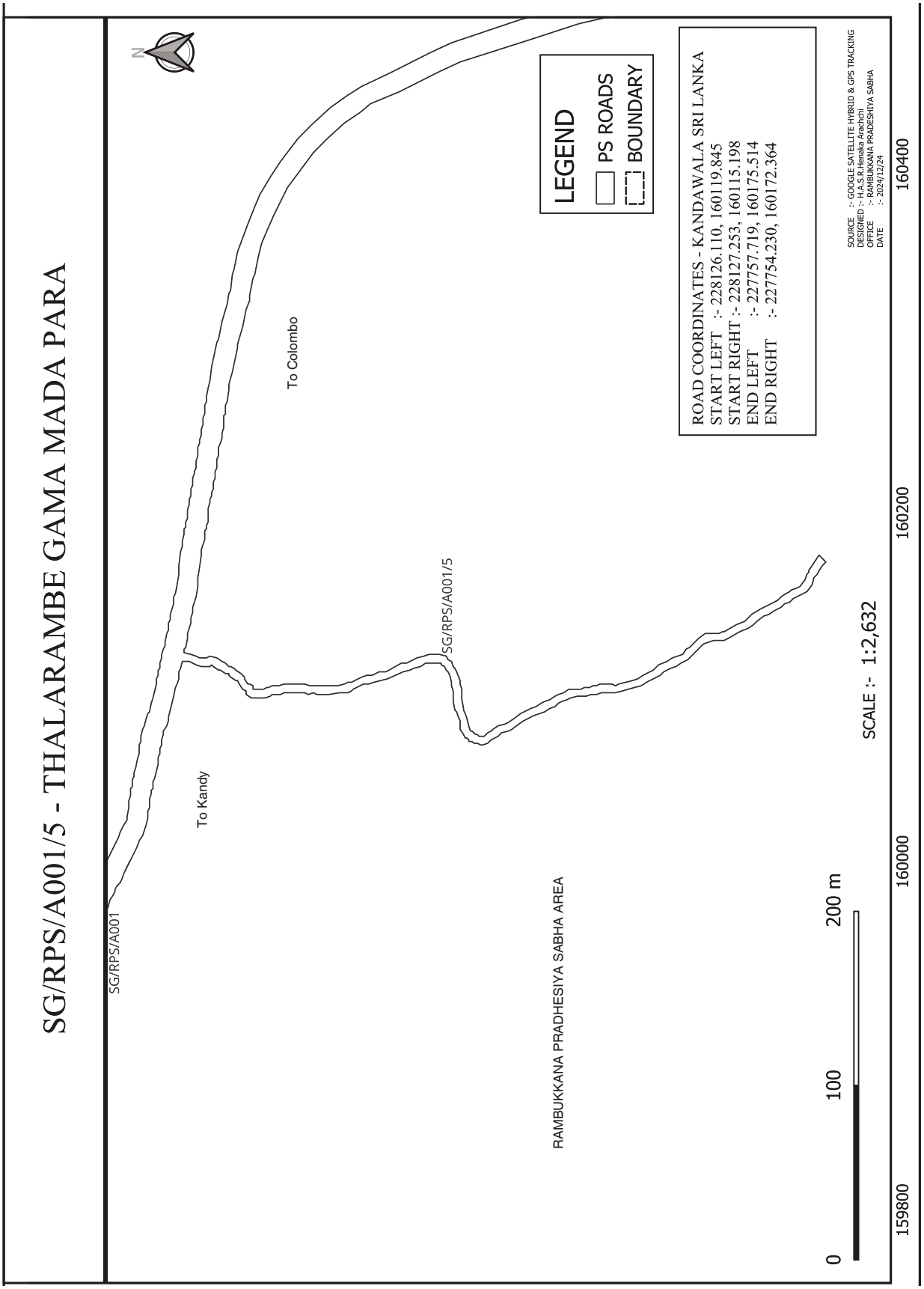
SG/RPS/A001/5 - THALARAMBE GAMA MADA PARA
N
LEGEND
PS ROADS
BOUNDARY
ROAD COORDINATES - KANDAWALA SRI LANKA
START LEFT :- 228126.110, 160119.845
START RIGHT :- 228127.253, 160115.198
END LEFT :- 227757.719, 160175.514
END RIGHT :- 227754.230, 160172.364
SOURCE :- GOOGLE SATELLITE HYBRID & GPS TRACKING
DESIGNED :- H.A.S.R.Herath Arachchi
OFFICE :- RAMBUKKANA PRADESHIYA SABHA
DATE :- 2024/12/24
SCALE :- 1:2,632
0
100
200 m
159800
160000
160200
160400
To Colombo
To Kandy
SG/RPS/A001
SG/RPS/A001/5
RAMBUKKANA PRADHESIYA SABHA AREA

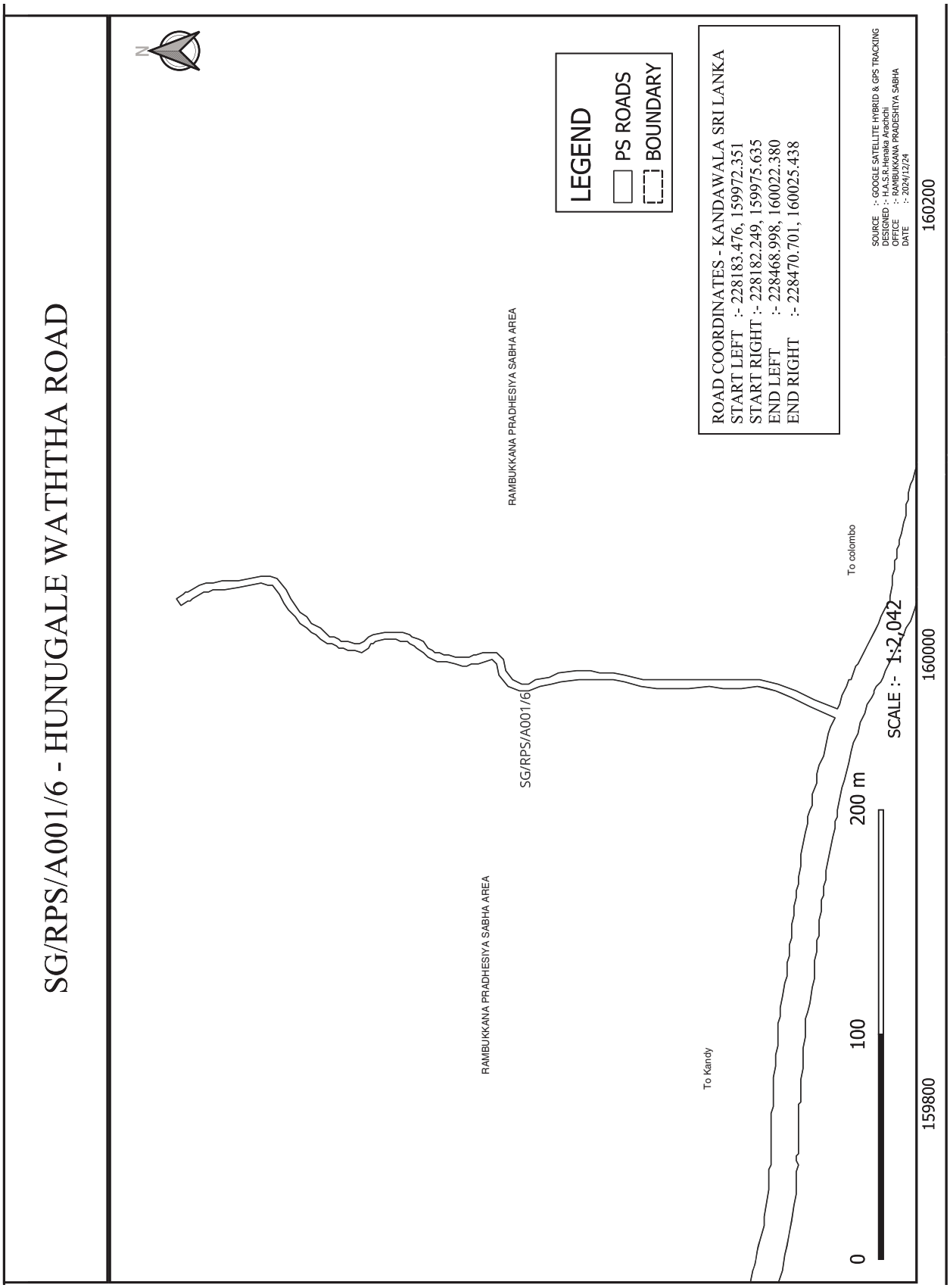
SG/RPS/A001/6 - HUNUGALE WATHTHA ROAD
N
LEGEND
PS ROADS
BOUNDARY
ROAD COORDINATES - KANDAWALA SRI LANKA
START LEFT :- 228183.476, 159972.351
START RIGHT :- 228182.249, 159975.635
END LEFT :- 228468.998, 160022.380
END RIGHT :- 228470.701, 160025.438
SOURCE :- GOOGLE SATELLITE HYBRID & GPS TRACKING
DESIGNED :- H.A.S.R.Henaka Arachchi
OFFICE :- RAMBUKKANA PRADESHIYA SABHA
DATE :- 2024/12/24
RAMBUKKANA PRADHESIYA SABHA AREA
RAMBUKKANA PRADHESIYA SABHA AREA
SG/RPS/A001/6
To Kandy
To colombo
SCALE :- 1:2,042
0
100
200 m
159800
160000
160200

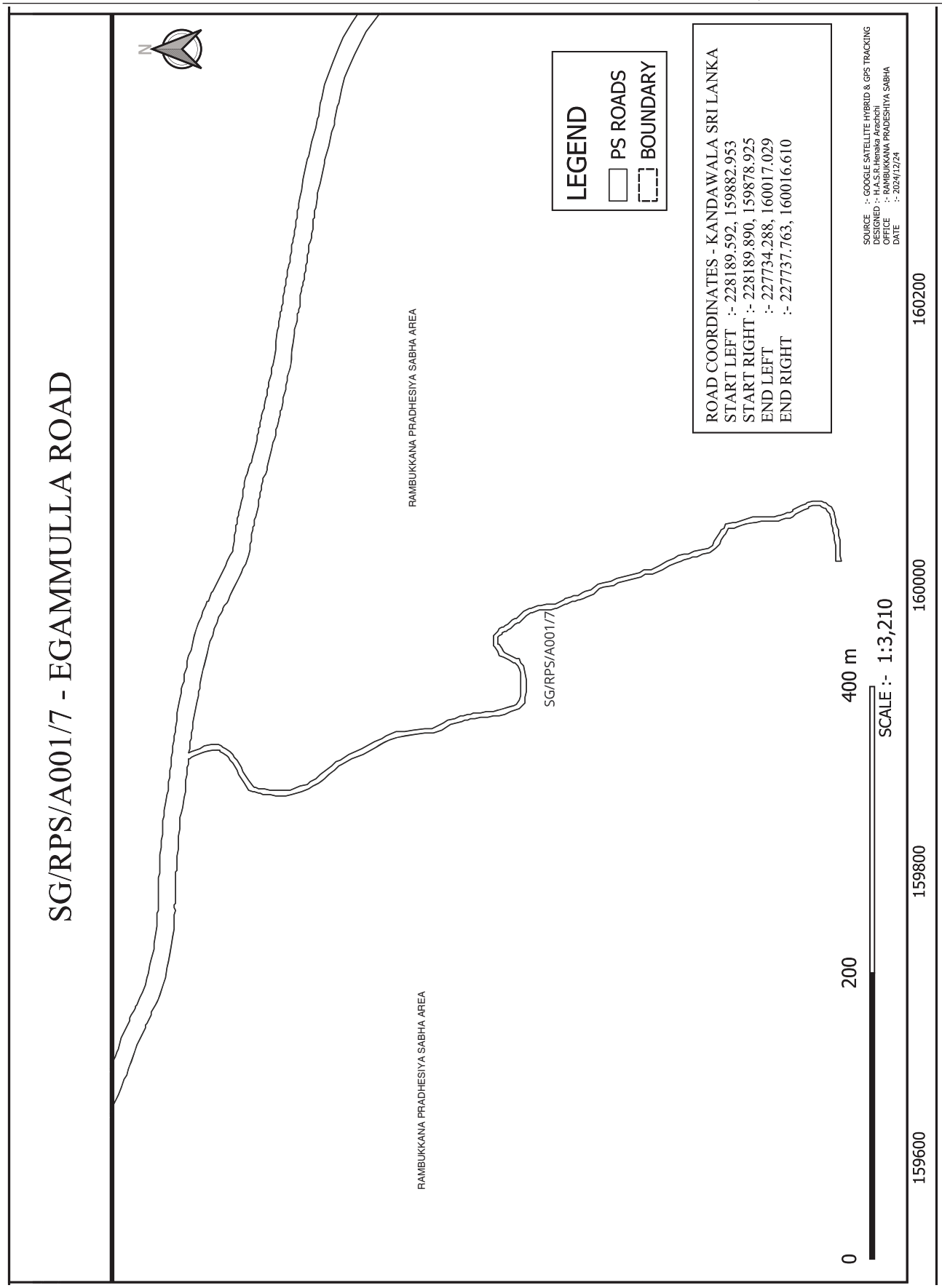
SG/RPS/A001/7 - EGAMMULLA ROAD
N
RAMBUKKANA PRADHESIYA SABHA AREA
RAMBUKKANA PRADHESIYA SABHA AREA
SG/RPS/A001/7
LEGEND
PS ROADS
BOUNDARY
ROAD COORDINATES - KANDAWALA SRI LANKA
START LEFT :- 228189.592, 159882.953
START RIGHT :- 228189.890, 159878.925
END LEFT :- 227734.288, 160017.029
END RIGHT :- 227737.763, 160016.610
SOURCE :- GOOGLE SATELLITE HYBRID & GPS TRACKING
DESIGNED :- H.A.S.R.Henaka Arachchi
OFFICE :- RAMBUKKANA PRADESHIYA SABHA
DATE :- 2024/12/24
0
200
400 m
SCALE :- 1:3,210
159600
159800
160000
160200

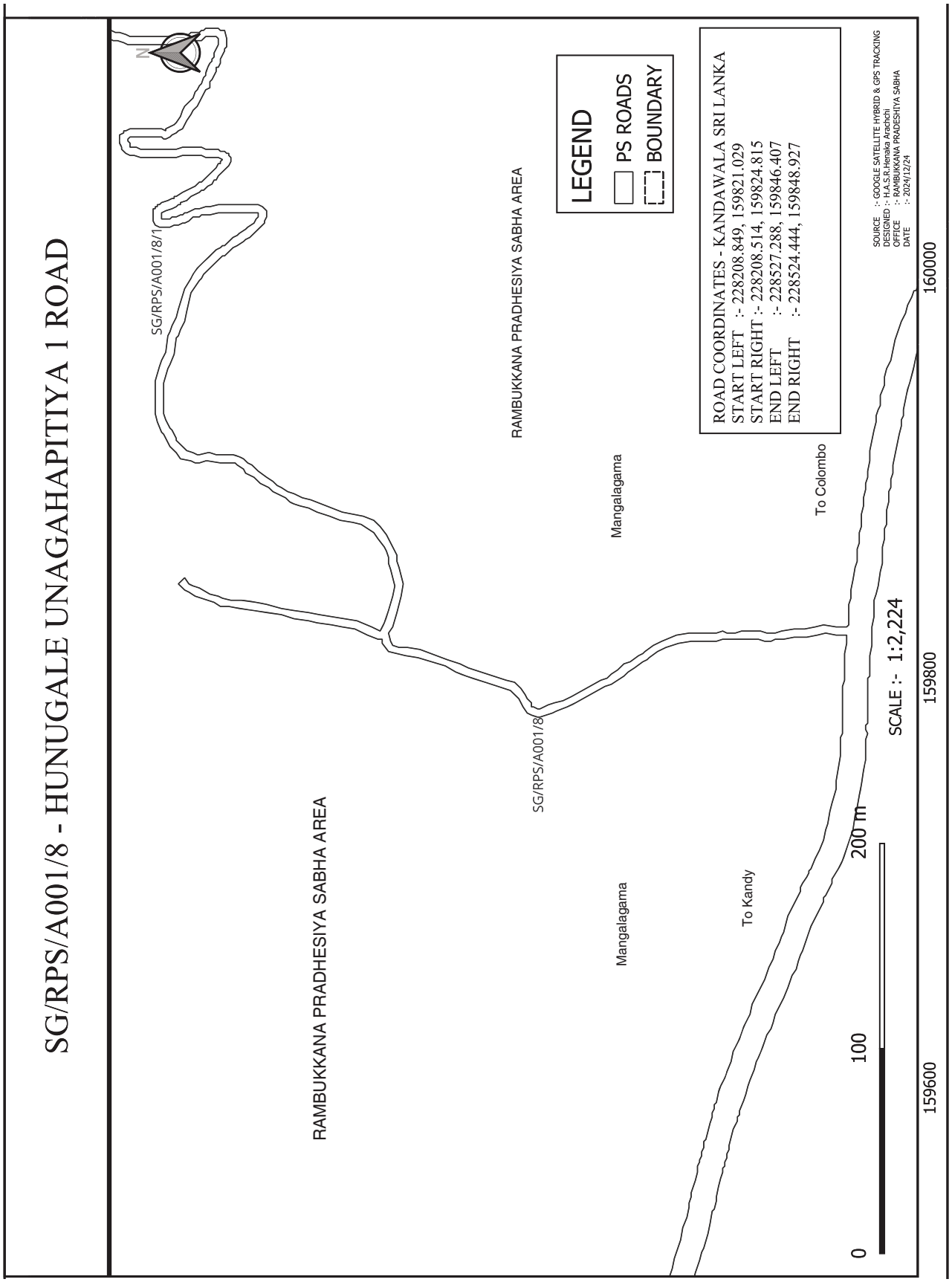
SG/RPS/A001/8 - HUNUGALE UNAGAHAPITIYA 1 ROAD
N
SG/RPS/A001/8/1
RAMBUKKANA PRADHESIYA SABHA AREA
LEGEND
PS ROADS
BOUNDARY
ROAD COORDINATES - KANDAWALA SRI LANKA
START LEFT :- 228208.849, 159821.029
START RIGHT :- 228208.514, 159824.815
END LEFT :- 228527.288, 159846.407
END RIGHT :- 228524.444, 159848.927
SOURCE :- GOOGLE SATELLITE HYBRID & GPS TRACKING
DESIGNED :- H.A.S.R.Henaka Arachchi
OFFICE :- RAMBUKKANA PRADESHIYA SABHA
DATE :- 2024/12/24
Mangalagama
To Colombo
SG/RPS/A001/8
RAMBUKKANA PRADHESIYA SABHA AREA
Mangalagama
To Kandy
SCALE :- 1:2,224
0
100
200 m
159600
159800
160000

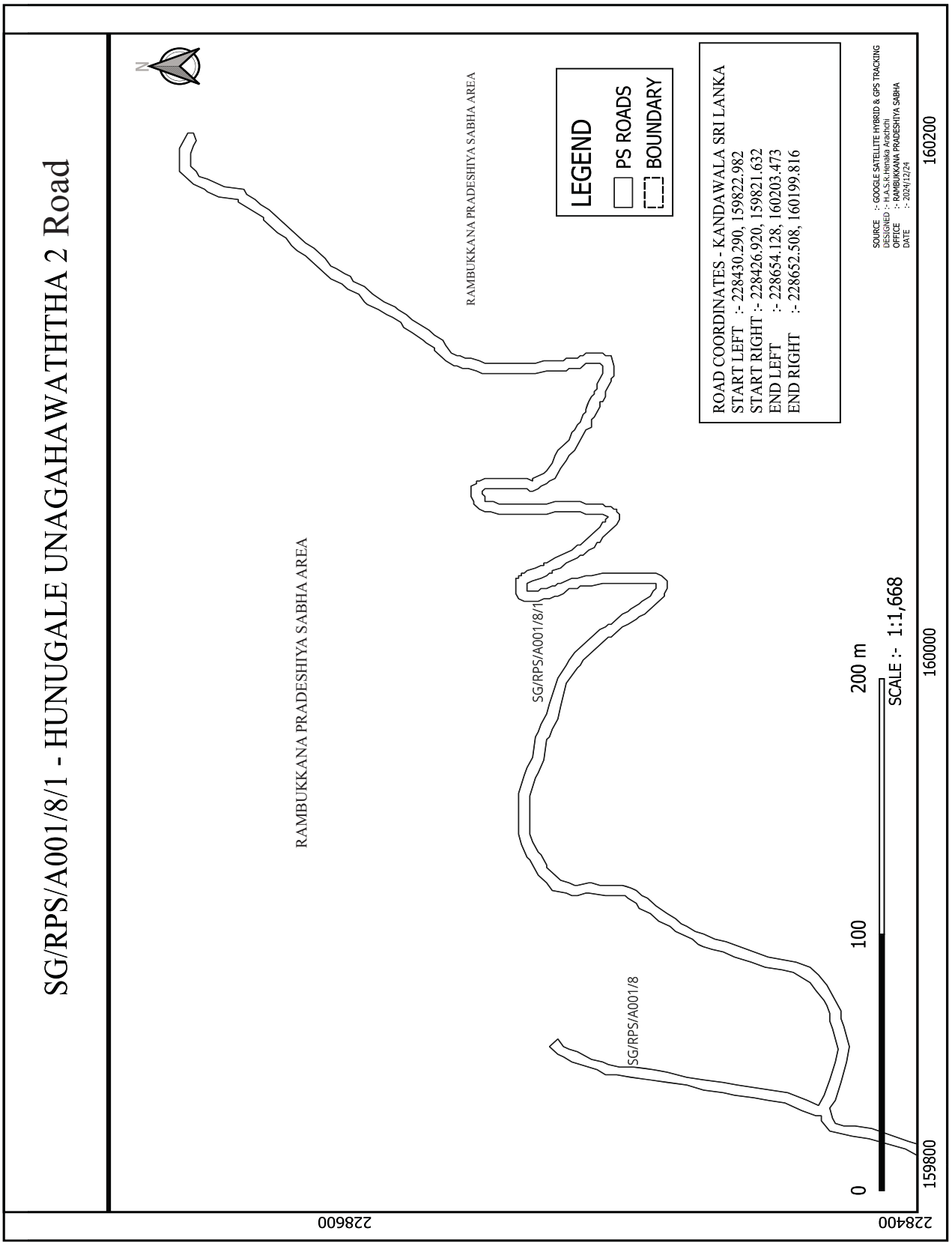
SG/RPS/A001/8/1 - HUNUGALE UNAGAHAWATHTHA 2 Road
N
RAMBUKKANA PRADESHIYA SABHA AREA
RAMBUKKANA PRADESHIYA SABHA AREA
LEGEND
PS ROADS
BOUNDARY
ROAD COORDINATES - KANDAWALA SRI LANKA
START LEFT :- 228430.290, 159822.982
START RIGHT :- 228426.920, 159821.632
END LEFT :- 228654.128, 160203.473
END RIGHT :- 228652.508, 160199.816
SG/RPS/A001/8/1
SG/RPS/A001/8
SOURCE :- GOOGLE SATTELLITE HYBRID & GPS TRACKING
DESIGNED :- H.A.S.K.Herath Arachchi
OFFICE :- RAMBUKKANA PRADESHIYA SABHA
DATE :- 2024/12/24
0
100
200 m
SCALE :- 1:1,668
159800
160000
160200
228400
228600

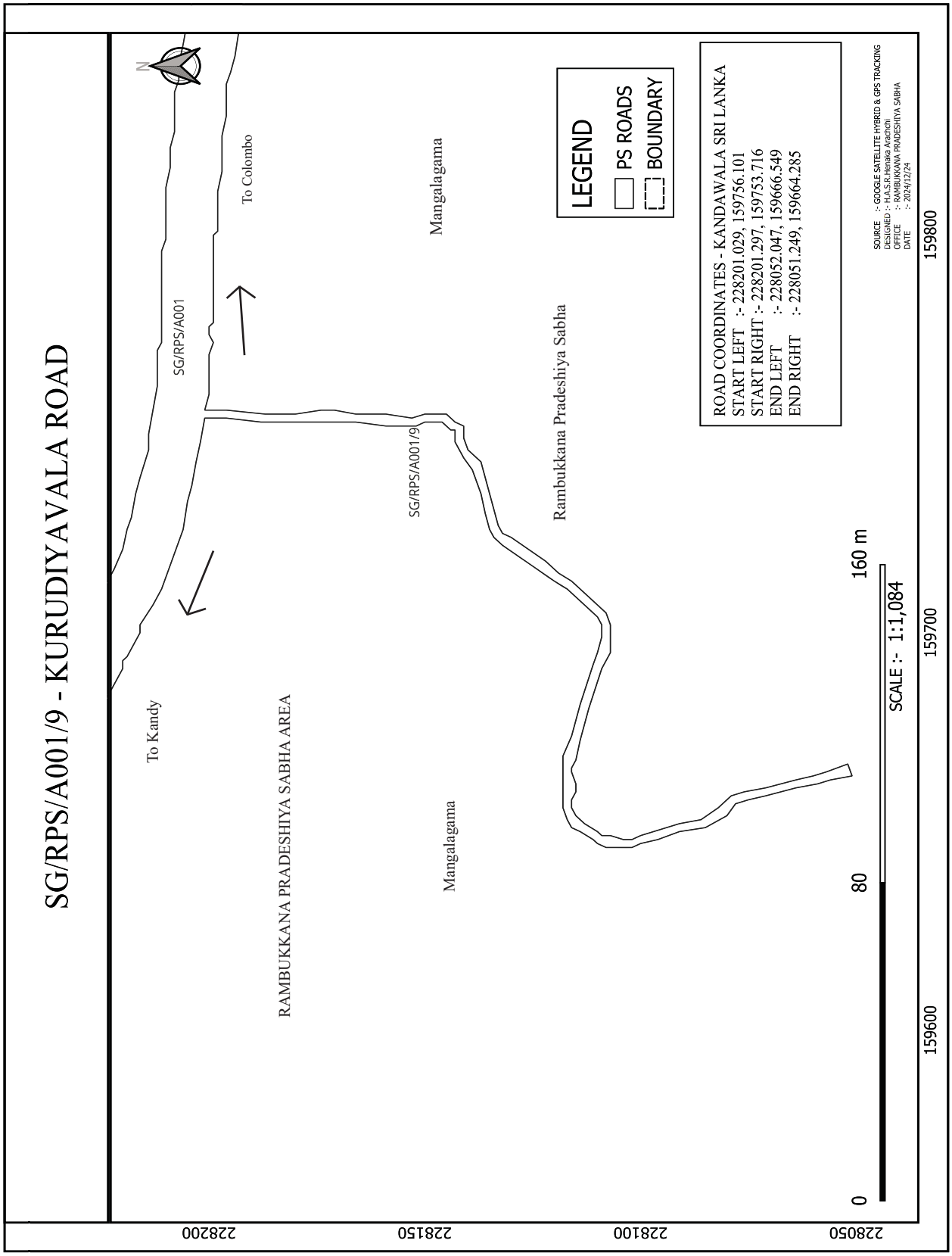
SG/RPS/A001 - KURUDIYAVALA ROAD
N
To Colombo
SG/RPS/A001
Mangalagama
LEGEND
PS ROADS
BOUNDARY
ROAD COORDINATES - KANDAWALA SRI LANKA
START LEFT :- 228201.029, 159756.101
START RIGHT :- 228201.297, 159753.716
END LEFT :- 228052.047, 159666.549
END RIGHT :- 228051.249, 159664.285
SOURCE :- GOOGLE SATELLITE HYBRID & GPS TRACKING
DESIGNED :- H.A.S.R.Henaka Arachchi
OFFICE :- RAMBUKKANA PRADESHIYA SABHA
DATE :- 2024/12/24
SG/RPS/A001/9
Rambukkana Pradeshiya Sabha
To Kandy
RAMBUKKANA PRADESHIYA SABHA AREA
Mangalagama
0
80
160 m
SCALE :- 1:1,084
159600
159700
159800
228050
228100
228150
228200

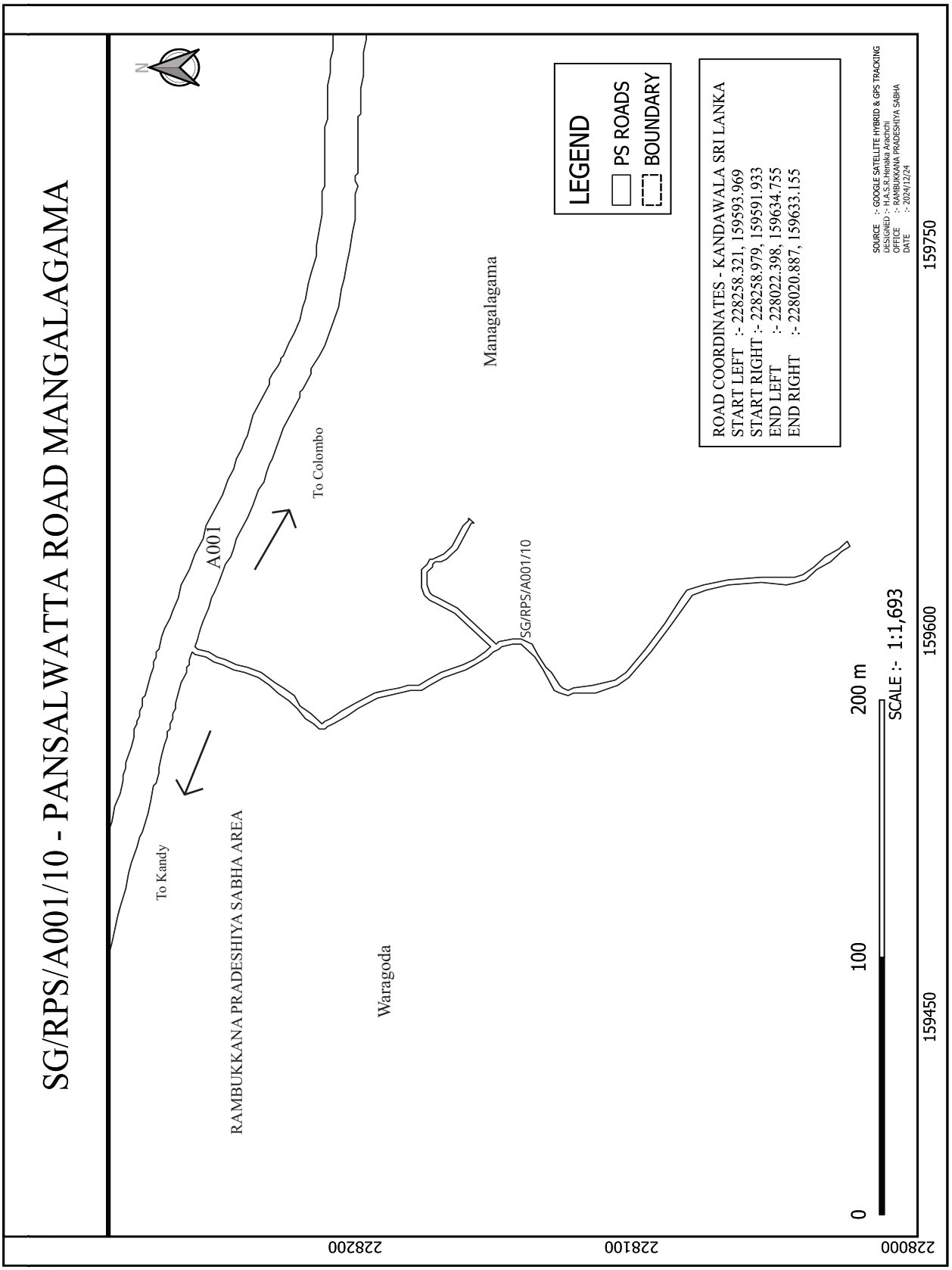
SG/RPS/A001/10 - PANSALWATTA ROAD MANGALAGAMA
N
LEGEND
PS ROADS
BOUNDARY
ROAD COORDINATES - KANDAWALA SRI LANKA
START LEFT :- 228258.321, 159593.969
START RIGHT :- 228258.979, 159591.933
END LEFT :- 228022.398, 159634.755
END RIGHT :- 228020.887, 159633.155
SOURCE :- GOOGLE SATELLITE HYBRID & GPS TRACKING
DESIGNED :- H.A.S.R.Henaka Arachchi
OFFICE :- RAMBUKKANA PRADESHIYA SABHA
DATE :- 2024/12/24
Managalagama
To Colombo
A001
SG/RPS/A001/10
To Kandy
RAMBUKKANA PRADESHIYA SABHA AREA
Waragoda
0
100
200 m
SCALE :- 1:1,693
159450
159600
159750
228000
228100
228200

SG/RPS/A001/10/1 - PANSALWATTHA MANGALAGAMA 1 PATUMAGA

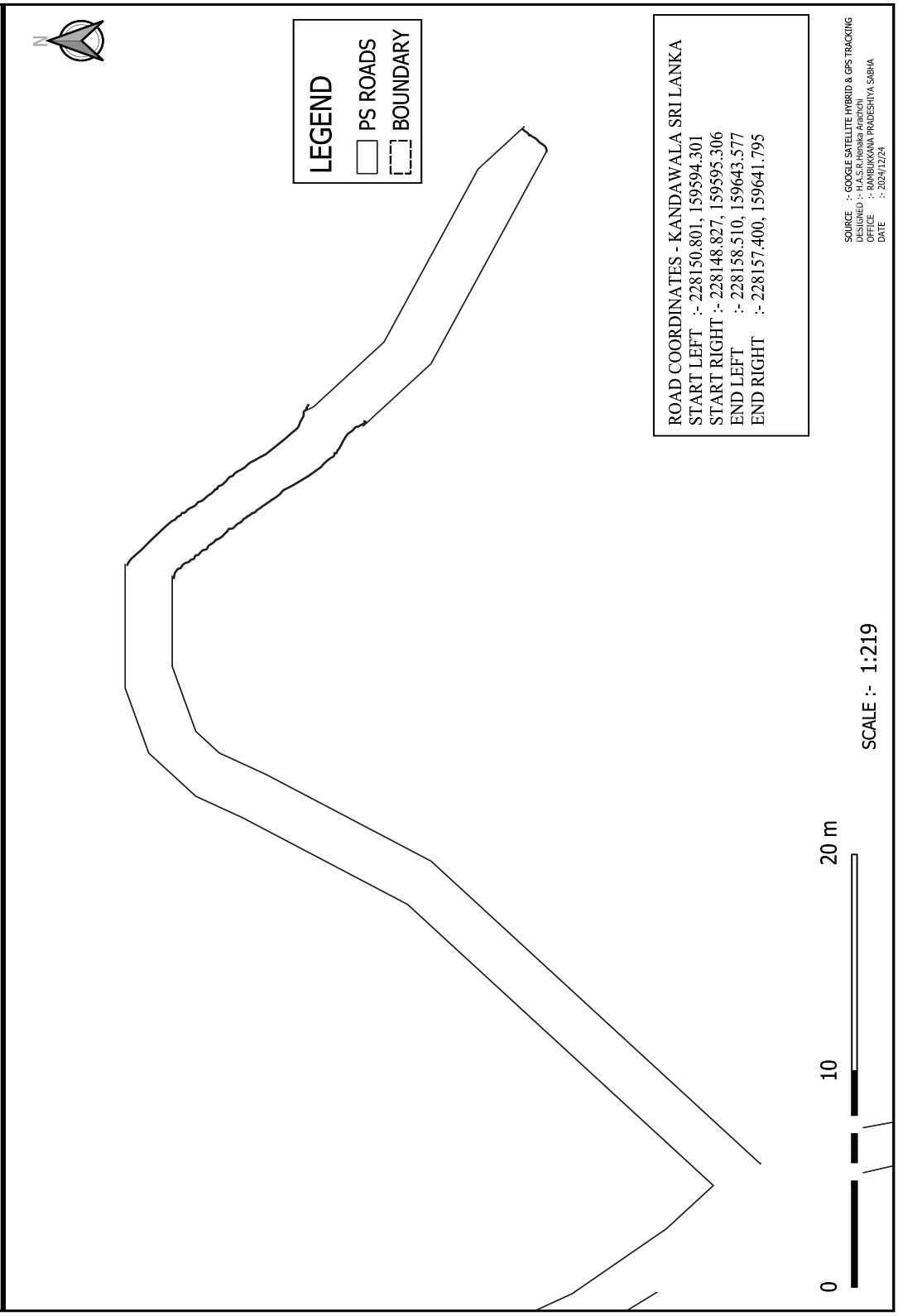

MANGALAGAMA MAHAGODA ROAD

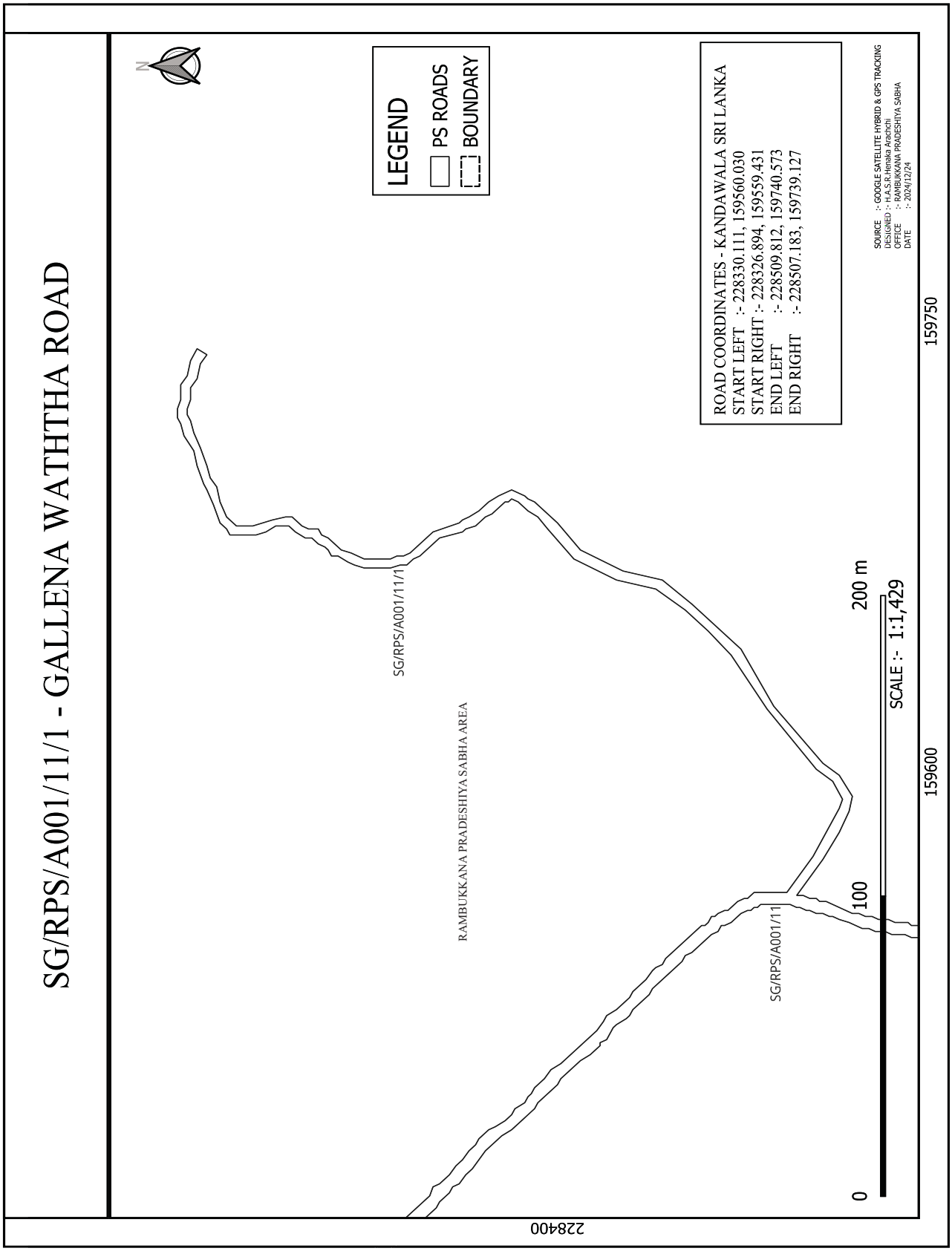
SG/RPS/A001/11/1 - GALLENA WATHTHA ROAD
N
LEGEND
PS ROADS
BOUNDARY
ROAD COORDINATES - KANDAWALA SRI LANKA
START LEFT :- 228330.111, 159560.030
START RIGHT :- 228326.894, 159559.431
END LEFT :- 228509.812, 159740.573
END RIGHT :- 228507.183, 159739.127
SOURCE :- GOOGLE SATELLITE HYBRID & GPS TRACKING
DESIGNED :- H.A.S.R.Hettiarachchi
OFFICE :- RAMBUKKANA PRADESHIYA SABHA
DATE :- 2024/12/24
SG/RPS/A001/11/1
RAMBUKKANA PRADESHIYA SABHA AREA
SG/RPS/A001/11
0
100
200 m
SCALE :- 1:1,429
159600
159750
228400

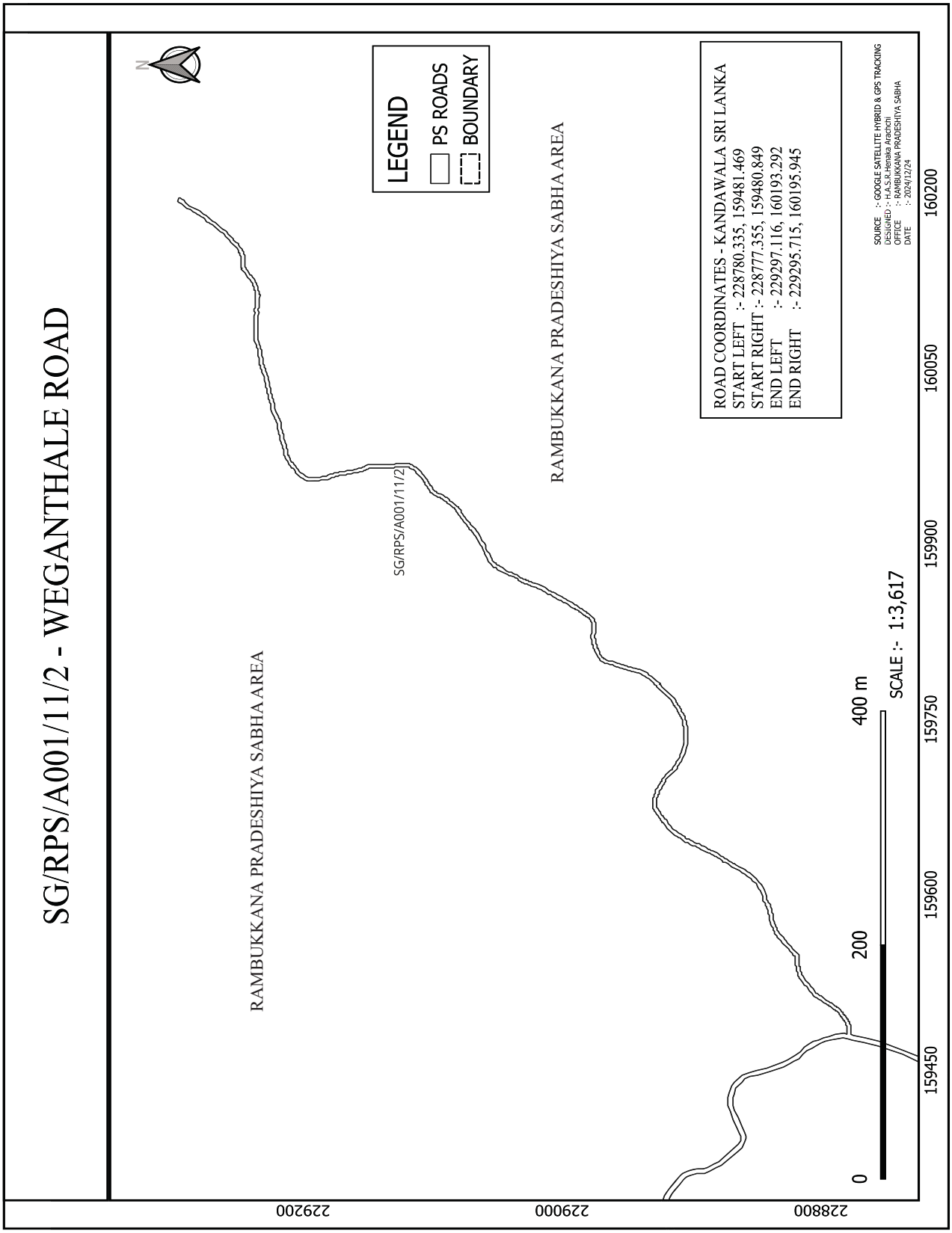
SG/RPS/A001/11/2 - WEGANTHALE ROAD
N
LEGEND
PS ROADS
BOUNDARY
RAMBUKKANA PRADESHIYA SABHA AREA
SG/RPS/A001/11/2
RAMBUKKANA PRADESHIYA SABHA AREA
ROAD COORDINATES - KANDAWALA SRI LANKA
START LEFT :- 228780.335, 159481.469
START RIGHT :- 228777.355, 159480.849
END LEFT :- 229297.116, 160193.292
END RIGHT :- 229295.715, 160195.945
SOURCE :- GOOGLE SATELLITE HYBRID & GPS TRACKING
DESIGNED :- H.A.S.R.Hettaka Arachchi
OFFICE :- RAMBUKKANA PRADESHIYA SABHA
DATE :- 2024/12/24
0
200
400 m
SCALE :- 1:3,617
159450
159600
159750
159900
160050
160200
229200
229000
228800

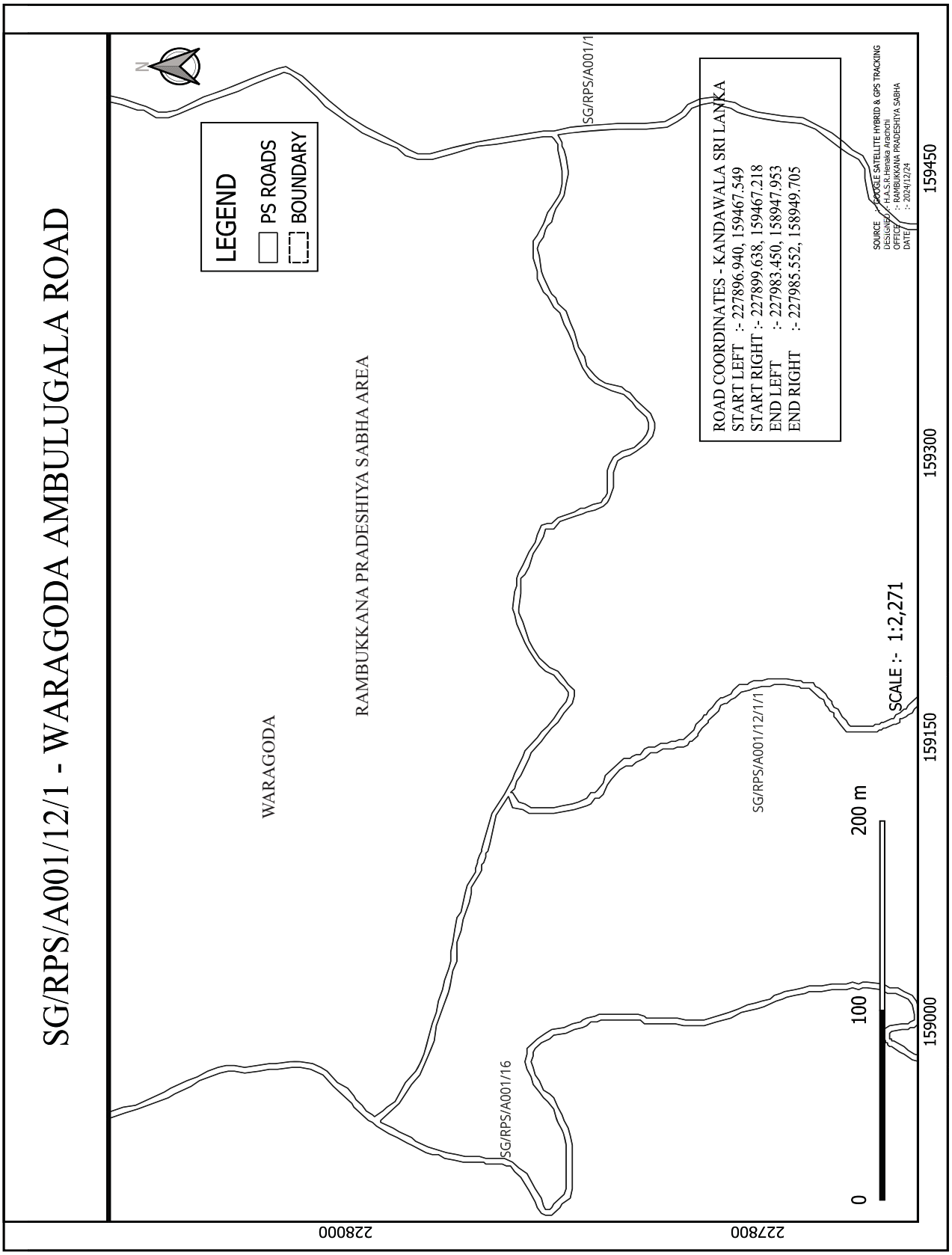
SG/RPS/A001/12/1 - WARAGODA AMBULUGALA ROAD
LEGEND
PS ROADS
BOUNDARY
N
WARAGODA
RAMBUKKANA PRADESHIYA SABHA AREA
SG/RPS/A001/1
SG/RPS/A001/12/1/1
SG/RPS/A001/16
ROAD COORDINATES - KANDAWALA SRI LANKA
START LEFT :- 227896.940, 159467.549
START RIGHT :- 227899.638, 159467.218
END LEFT :- 227983.450, 158947.953
END RIGHT :- 227985.552, 158949.705
SOURCE :- GOOGLE SATELLITE HYBRID & GPS TRACKING
DESIGNED :- H.A.S.R.Henaka Arachchi
OFFICE :- RAMBUKKANA PRADESHIYA SABHA
DATE :- 2024/12/24
SCALE :- 1:2,271
0
100
200 m
159000
159150
159300
159450
227800
228000

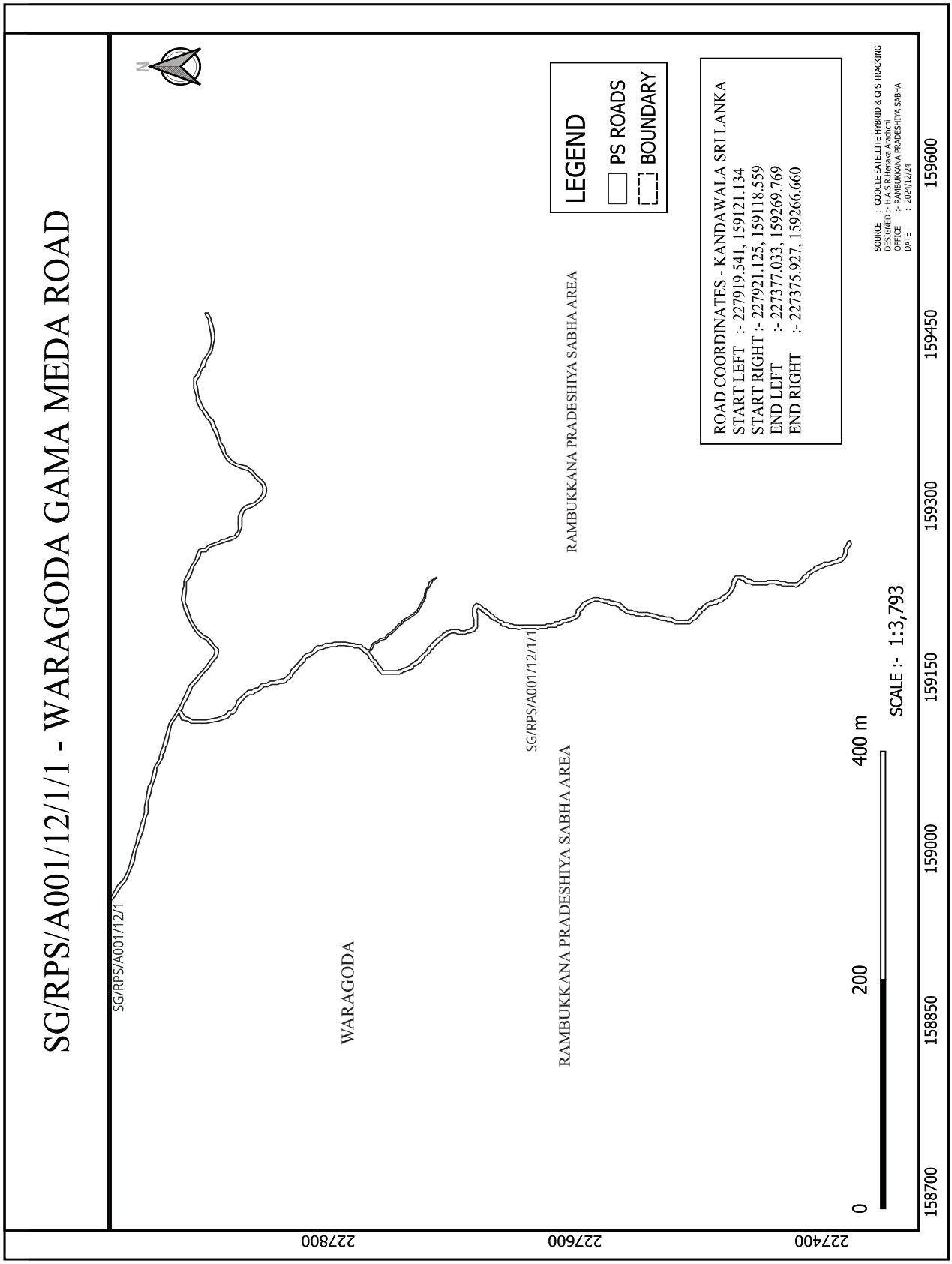
SG/RPS/A001/12/1/1 - WARAGODA GAMA MEDA ROAD
N
LEGEND
PS ROADS
BOUNDARY
ROAD COORDINATES - KANDAWALA SRI LANKA
START LEFT :- 227919.541, 159121.134
START RIGHT :- 227921.125, 159118.559
END LEFT :- 227377.033, 159269.769
END RIGHT :- 227375.927, 159266.660
SOURCE :- GOOGLE SATELLITE HYBRID & GPS TRACKING
DESIGNED :- H.A.S.R.Herath Ex(RDT)
OFFICE :- RAMBUKKANA PRADESHIYA SABHA
DATE :- 2024/12/24
SCALE :- 1:3,793
0
200
400 m
SG/RPS/A001/12/1
WARAGODA
RAMBUKKANA PRADESHIYA SABHA AREA
SG/RPS/A001/12/1/1
RAMBUKKANA PRADESHIYA SABHA AREA
158700
158850
159000
159150
159300
159450
159600
227400
227600
227800

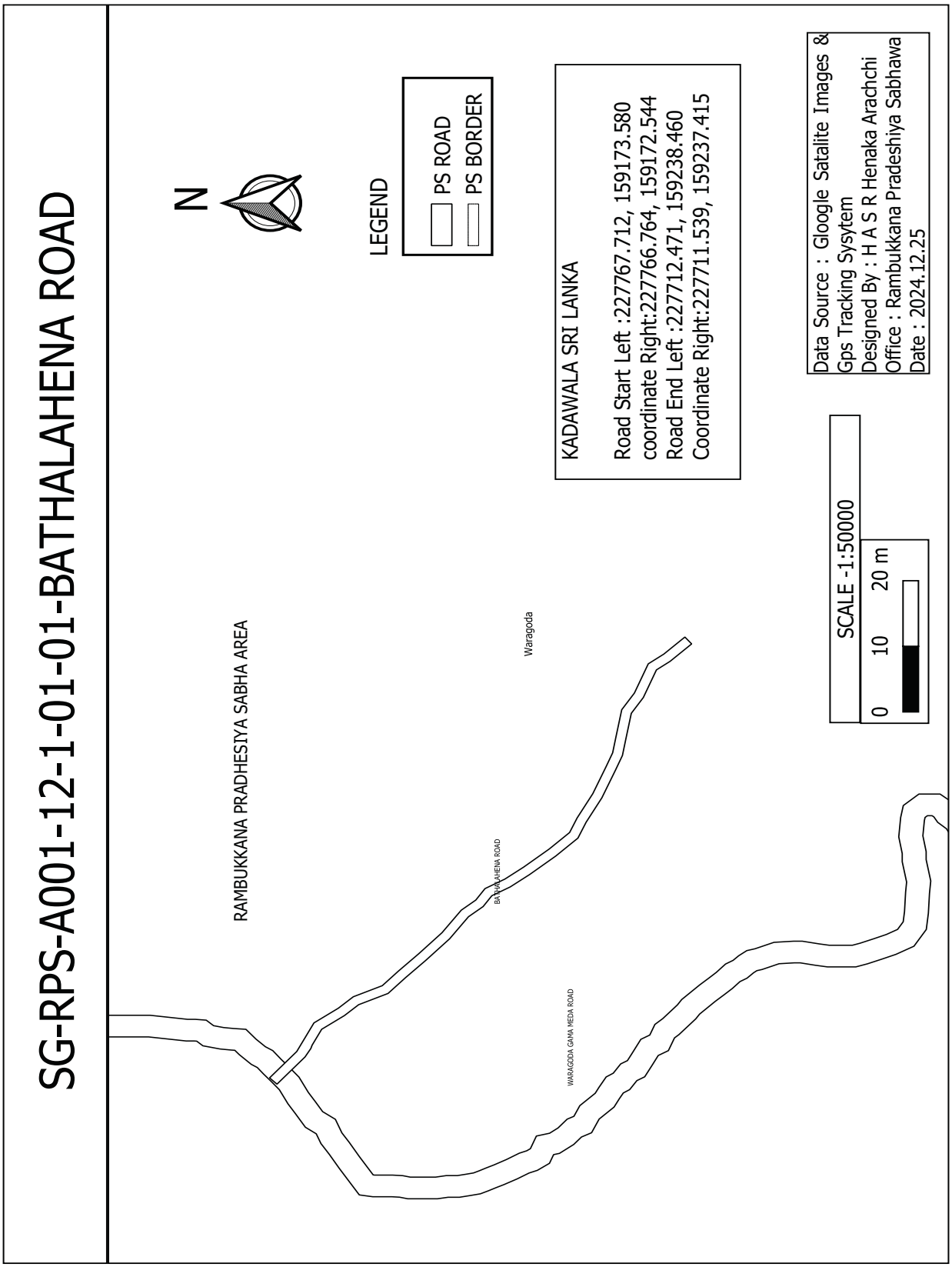
SG-RPS-A001-12-1-01-01-BATHALAHENA ROAD
N
LEGEND
PS ROAD
PS BORDER
KADAWALA SRI LANKA
Road Start Left :227767.712, 159173.580
coordinate Right:227766.764, 159172.544
Road End Left :227712.471, 159238.460
Coordinate Right:227711.539, 159237.415
Data Source : Gloogle Satalite Images &
Gps Tracking Sysytem
Designed By : H A S R Henaka Arachchi
Office : Rambukkana Pradeshiya Sabhawa
Date : 2024.12.25
SCALE -1:50000
0 10 20 m
RAMBUKKANA PRADHESIYA SABHA AREA
Waragoda
BATHALAHENA ROAD
WARAGODA GAMA MEDA ROAD

[redacted]

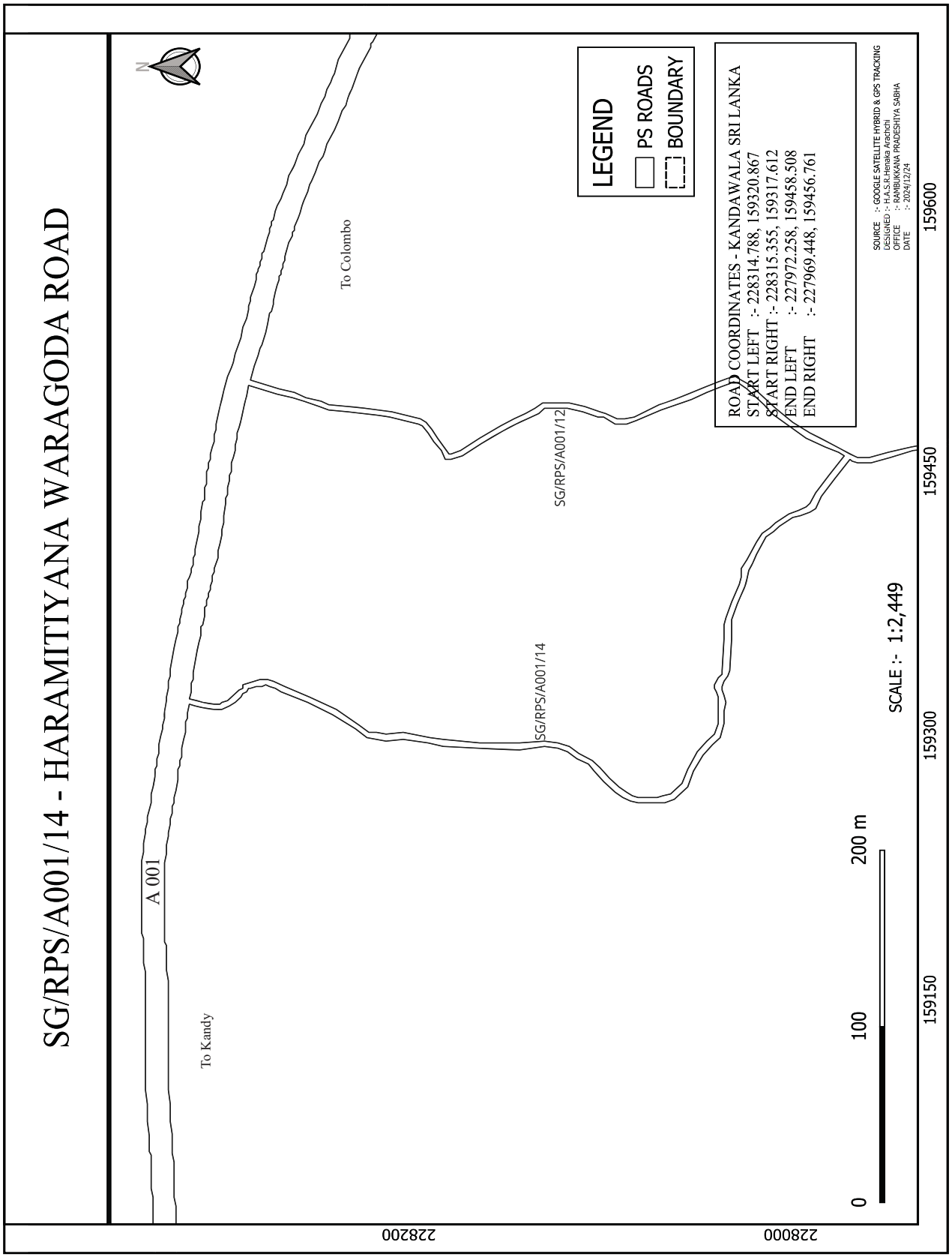
SG/RPS/A001/14 - HARAMITIYANA WARAGODA ROAD
N
To Colombo
To Kandy
A 001
SG/RPS/A001/12
SG/RPS/A001/14
LEGEND
PS ROADS
BOUNDARY
ROAD COORDINATES - KANDAWALA SRI LANKA
START LEFT :- 228314.788, 159320.867
START RIGHT :- 228315.355, 159317.612
END LEFT :- 227972.258, 159458.508
END RIGHT :- 227969.448, 159456.761
SOURCE :- GOOGLE SATELLITE HYBRID & GPS TRACKING
DESIGNED :- H.A.S.R.Henaka Arachchi
OFFICE :- RAMBUKKANA PRADESHIYA SABHA
DATE :- 2024/12/24
SCALE :- 1:2,449
0
100
200 m
159150
159300
159450
159600
228000
228200

[redacted]

[redacted]

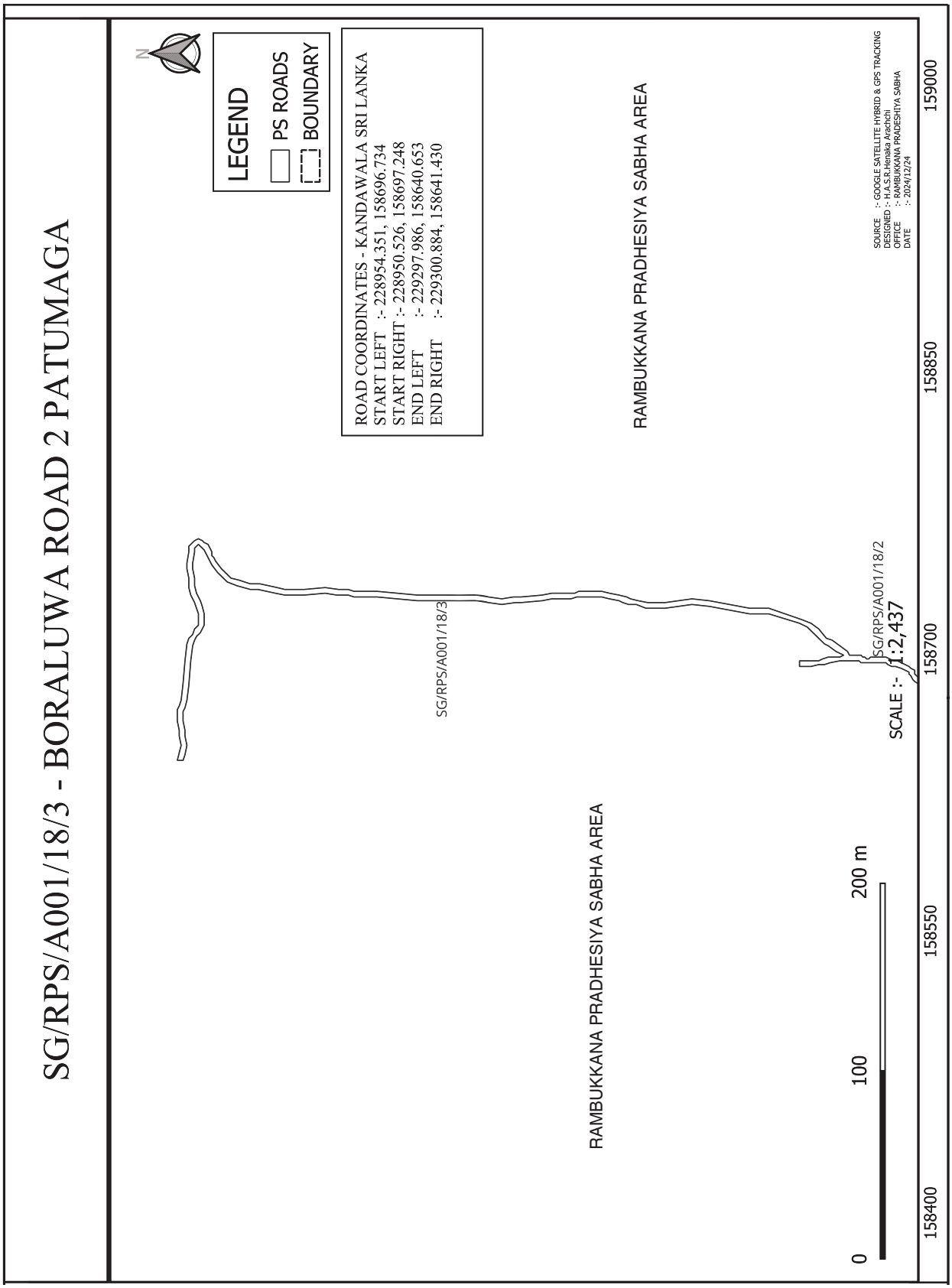
SG/RPS/A001/18/3 - BORALUWA ROAD 2 PATUMAGA
N
LEGEND
PS ROADS
BOUNDARY
ROAD COORDINATES - KANDAWALA SRI LANKA
START LEFT :- 228954.351, 158696.734
START RIGHT :- 228950.526, 158697.248
END LEFT :- 229297.986, 158640.653
END RIGHT :- 229300.884, 158641.430
RAMBUKKANA PRADHESIYA SABHA AREA
SG/RPS/A001/18/3
SG/RPS/A001/18/2
RAMBUKKANA PRADHESIYA SABHA AREA
SCALE :- 1:2,437
0
100
200 m
158400
158550
158700
158850
159000
SOURCE :- GOOGLE SATTELITE HYBRID & GPS TRACKING
DESIGNED :- H.A.S.R.Henaka Arachchi
OFFICE :- RAMBUKKANA PRADESHIYA SABHA
DATE :- 2024/12/24

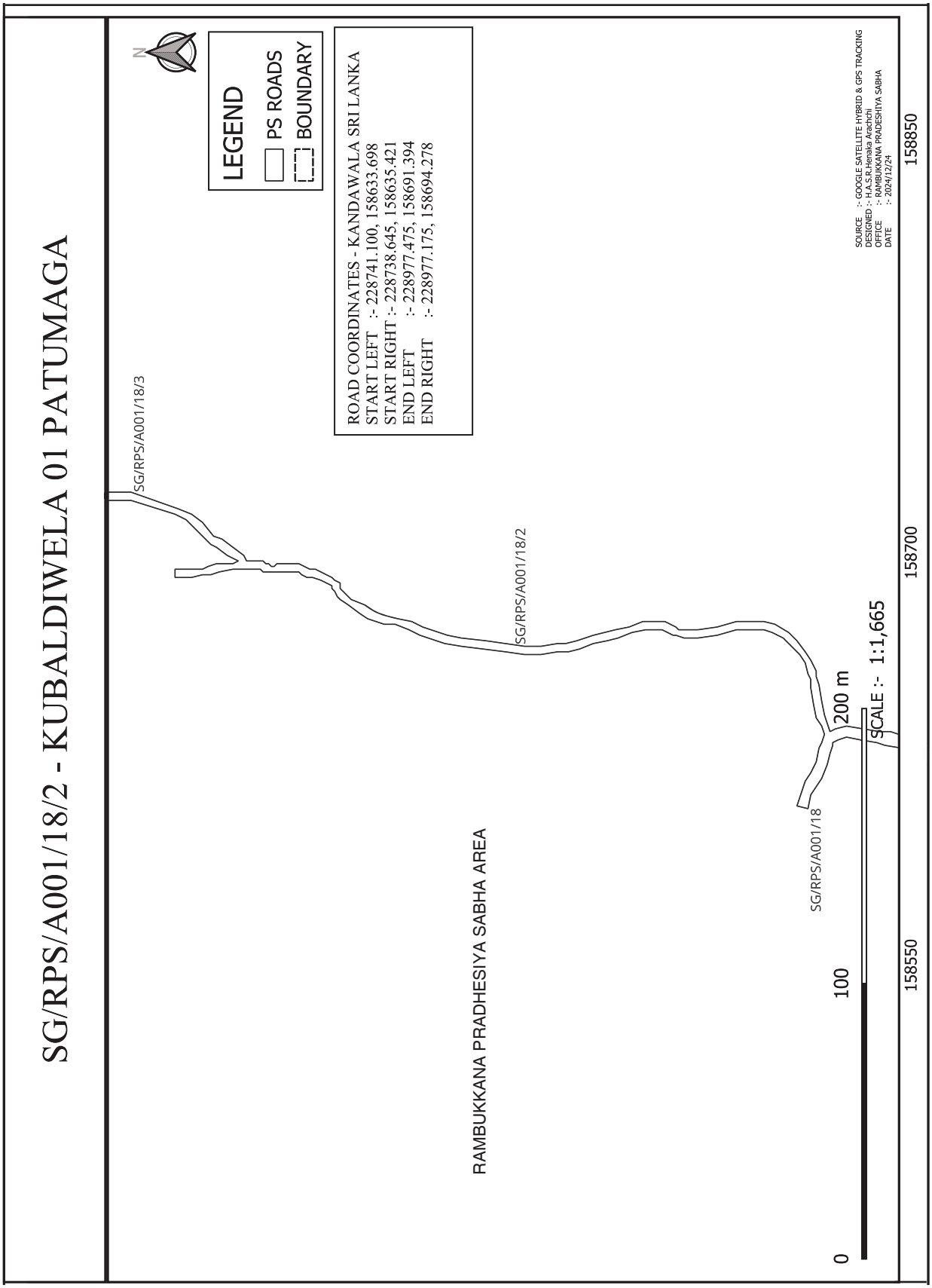
SG/RPS/A001/18/2 - KUBALDIWELA 01 PATUMAGA
N
LEGEND
PS ROADS
BOUNDARY
ROAD COORDINATES - KANDAWALA SRI LANKA
START LEFT :- 228741.100, 158633.698
START RIGHT :- 228738.645, 158635.421
END LEFT :- 228977.475, 158691.394
END RIGHT :- 228977.175, 158694.278
SG/RPS/A001/18/3
SG/RPS/A001/18/2
SG/RPS/A001/18
RAMBUKKANA PRADHESIYA SABHA AREA
0
100
200 m
SCALE :- 1:1,665
158550
158700
158850
SOURCE :- GOOGLE SATELLITE HYBRID & GPS TRACKING
DESIGNED :- H.A.S.R.Henaka Arachchi
OFFICE :- RAMBUKKANA PRADESHIYA SABHA
DATE :- 2024/12/24

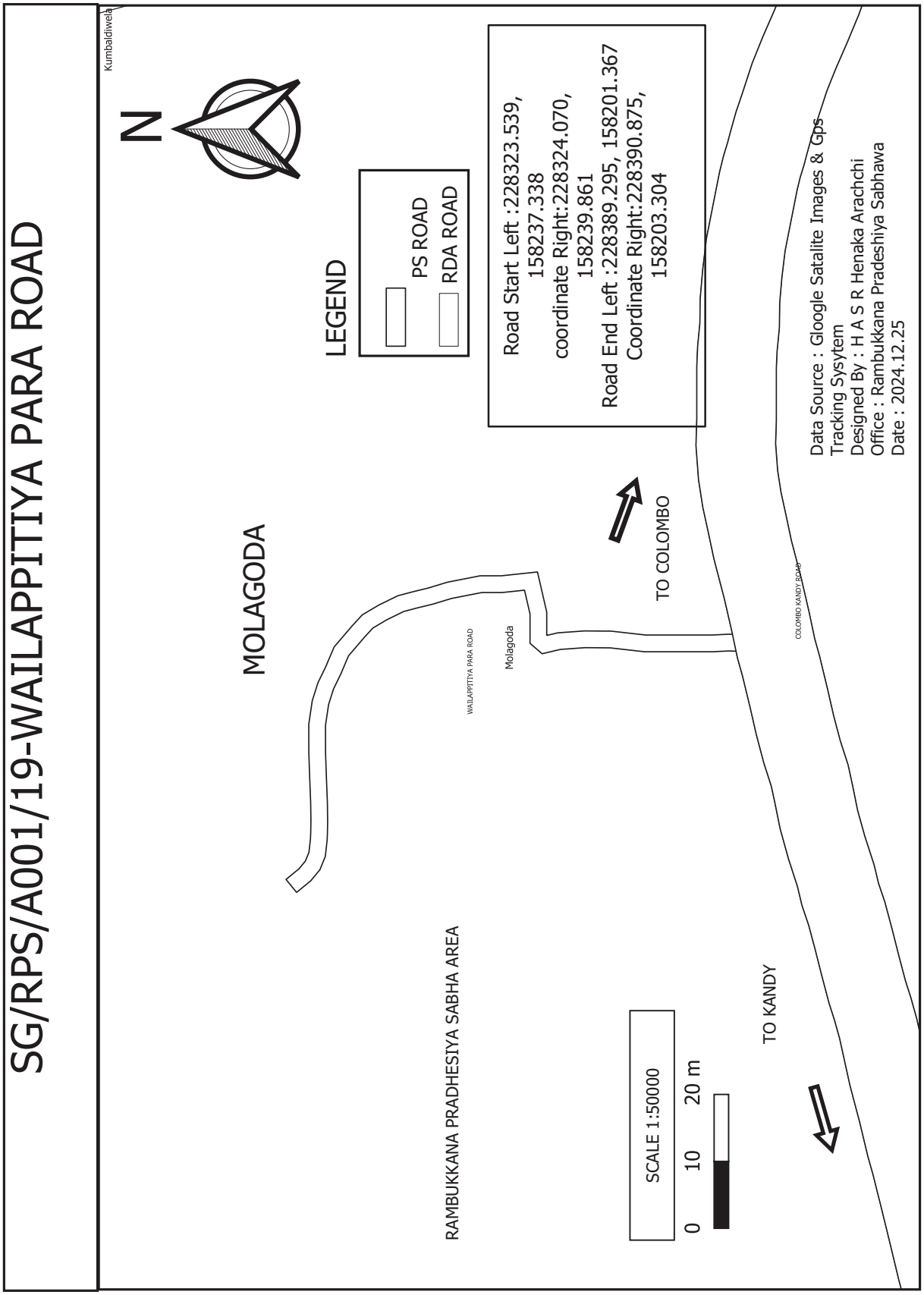
SG/RPS/A001/19-WAILAPPITIYA PARA ROAD
Kumbaldiweli
N
LEGEND
PS ROAD
RDA ROAD
Road Start Left :228323.539, 158237.338
coordinate Right:228324.070, 158239.861
Road End Left :228389.295, 158201.367
Coordinate Right:228390.875, 158203.304
Data Source : Gloogle Satalite Images & Gps Tracking Sysytem
Designed By : H A S R Henaka Arachchi
Office : Rambukkana Pradeshiya Sabhawa
Date : 2024.12.25
MOLAGODA
TO COLOMBO
WAILAPPITIYA PARA ROAD
Molagoda
COLOMBO KANDY ROAD
RAMBUKKANA PRADHESIYA SABHA AREA
TO KANDY
SCALE 1:50000
0 10 20 m

[redacted]

SG/RPS/A001/20/1 - KUBALDIWELA PIRIWENA ROAD 1 PATUMAGA



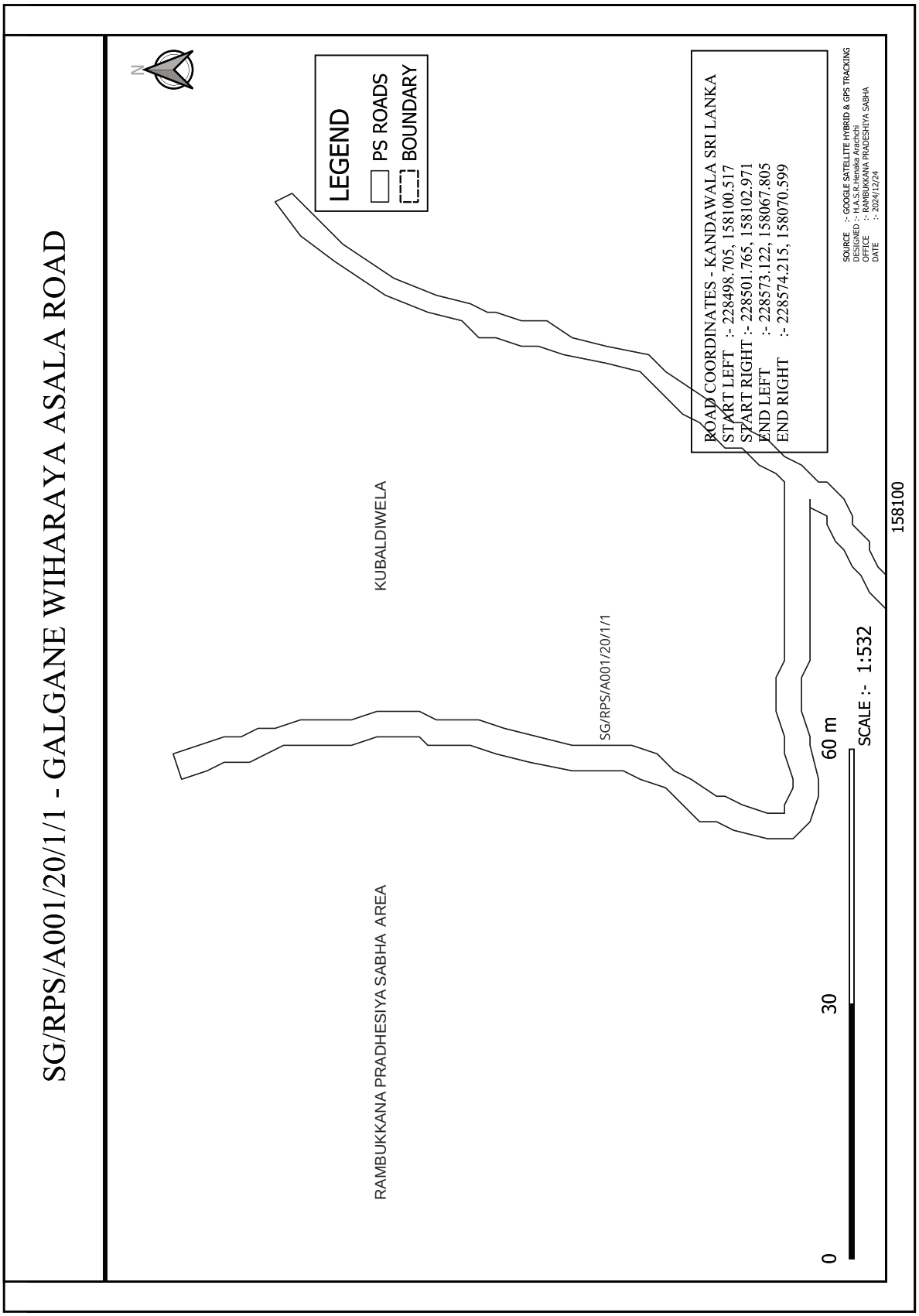
SG/RPS/A001/20/1/1 - GALGANE WIHARAYA ASALA ROAD
N
LEGEND
PS ROADS
BOUNDARY
ROAD COORDINATES - KANDAWALA SRI LANKA
START LEFT :- 228498.705, 158100.517
START RIGHT :- 228501.765, 158102.971
END LEFT :- 228573.122, 158067.805
END RIGHT :- 228574.215, 158070.599
SOURCE :- GOOGLE SATELLITE HYBRID & GPS TRACKING
DESIGNED :- H.A.S.R.Hetaka Arachchi
OFFICE :- RAMBUKKANA PRADESHIYA SABHA
DATE :- 2024/12/24
KUBALDIWELA
SG/RPS/A001/20/1/1
RAMBUKKANA PRADHESIYA SABHA AREA
158100
0
30
60 m
SCALE :- 1:532

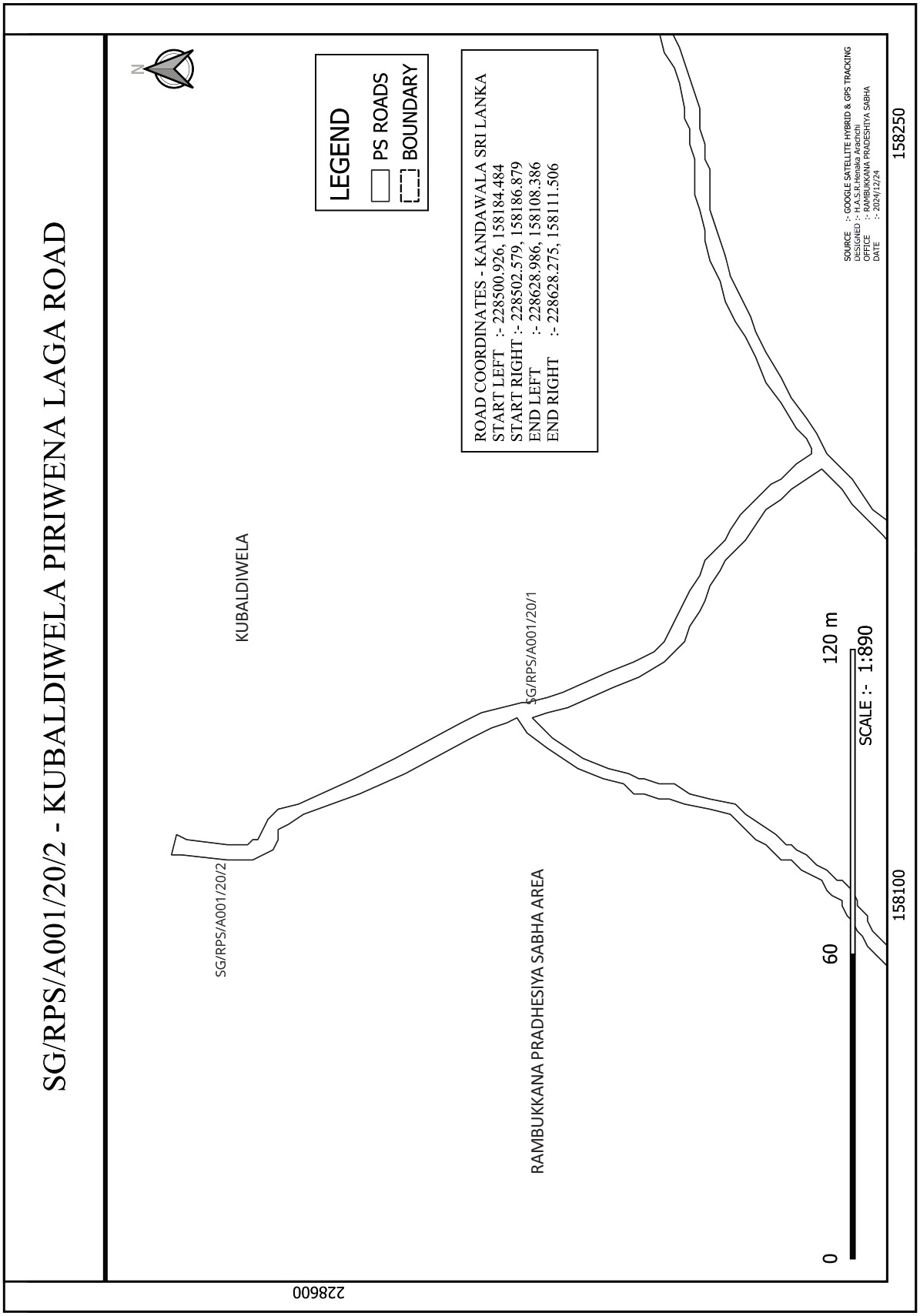
SG/RPS/A001/20/2 - KUBALDIWELA PIRIWENA LAGA ROAD
N
LEGEND
PS ROADS
BOUNDARY
ROAD COORDINATES - KANDAWALA SRI LANKA
START LEFT :- 228500.926, 158184.484
START RIGHT :- 228502.579, 158186.879
END LEFT :- 228628.986, 158108.386
END RIGHT :- 228628.275, 158111.506
KUBALDIWELA
SG/RPS/A001/20/1
SG/RPS/A001/20/2
RAMBUKKANA PRADHESIYA SABHA AREA
0
60
120 m
SCALE :- 1:890
SOURCE :- GOOGLE SATELLITE HYBRID & GPS TRACKING
DESIGNED :- H.A.S.R.Hettiaka Aachchi
OFFICE :- RAMBUKKANA PRADESHIYA SABHA
DATE :- 2024/12/24
158250
158100
228600

[redacted]

RAMBUKKANA PRADHESIYA SABHA AREA


TO KANDY
RAMBUKKANA PRADHESIYA SABHA AREA

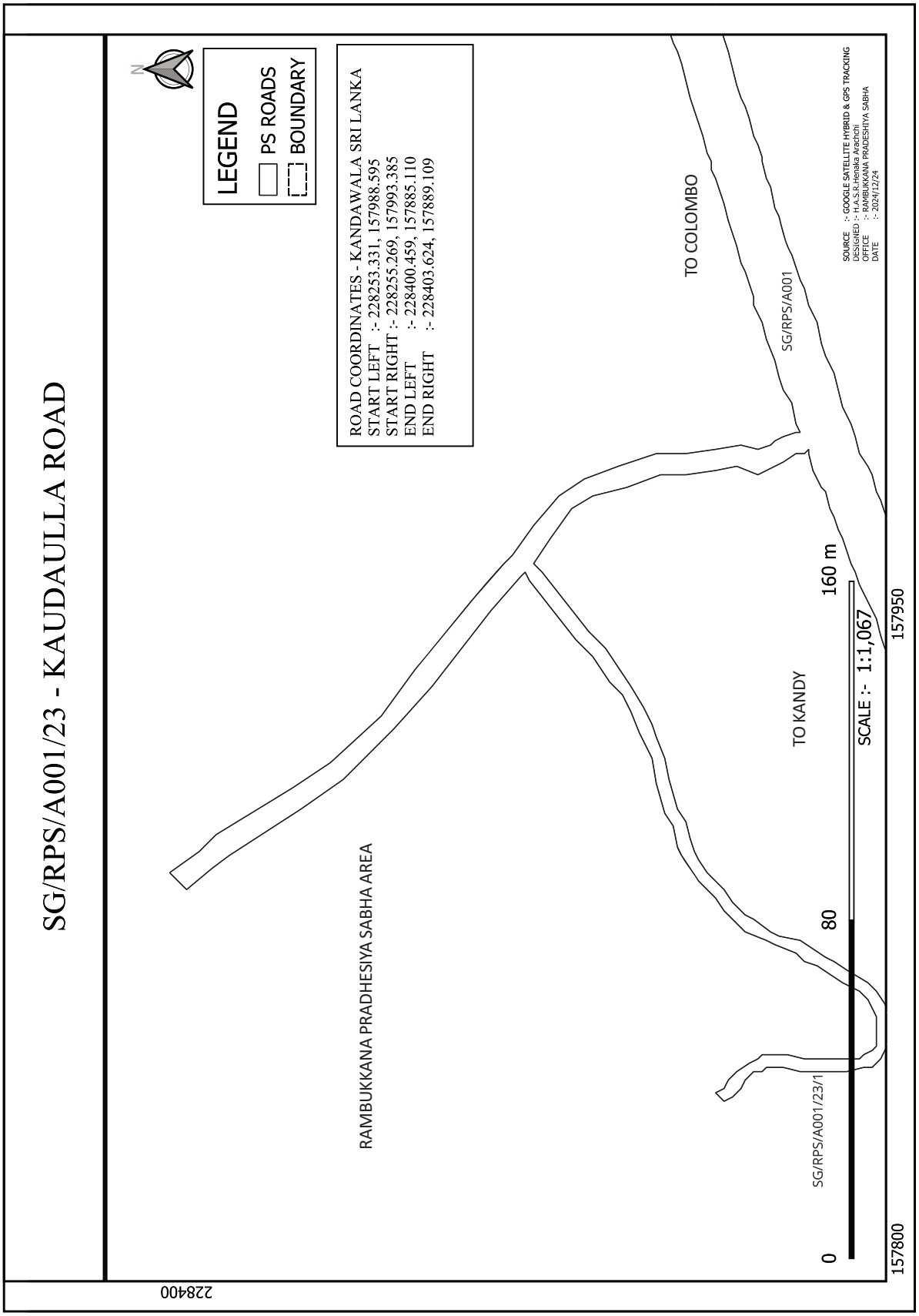
SG/RPS/A001/23 - KAUDAULLA ROAD
LEGEND
PS ROADS
BOUNDARY
ROAD COORDINATES - KANDAWALA SRI LANKA
START LEFT :- 228253.331, 157988.595
START RIGHT :- 228255.269, 157993.385
END LEFT :- 228400.459, 157885.110
END RIGHT :- 228403.624, 157889.109
TO COLOMBO
SG/RPS/A001
SOURCE :- GOOGLE SATELLITE HYBRID & GPS TRACKING
DESIGNED :- H.A.S.R. HEWIRA AREACHCHI
OFFICE :- RAMBUKKANA PRADESHIYA SABHA
DATE :- 2024/12/24
160 m
SCALE :- 1:1,067
TO KANDY
RAMBUKKANA PRADHESIYA SABHA AREA
0
80
SG/RPS/A001/23/1
157800
157950
228400

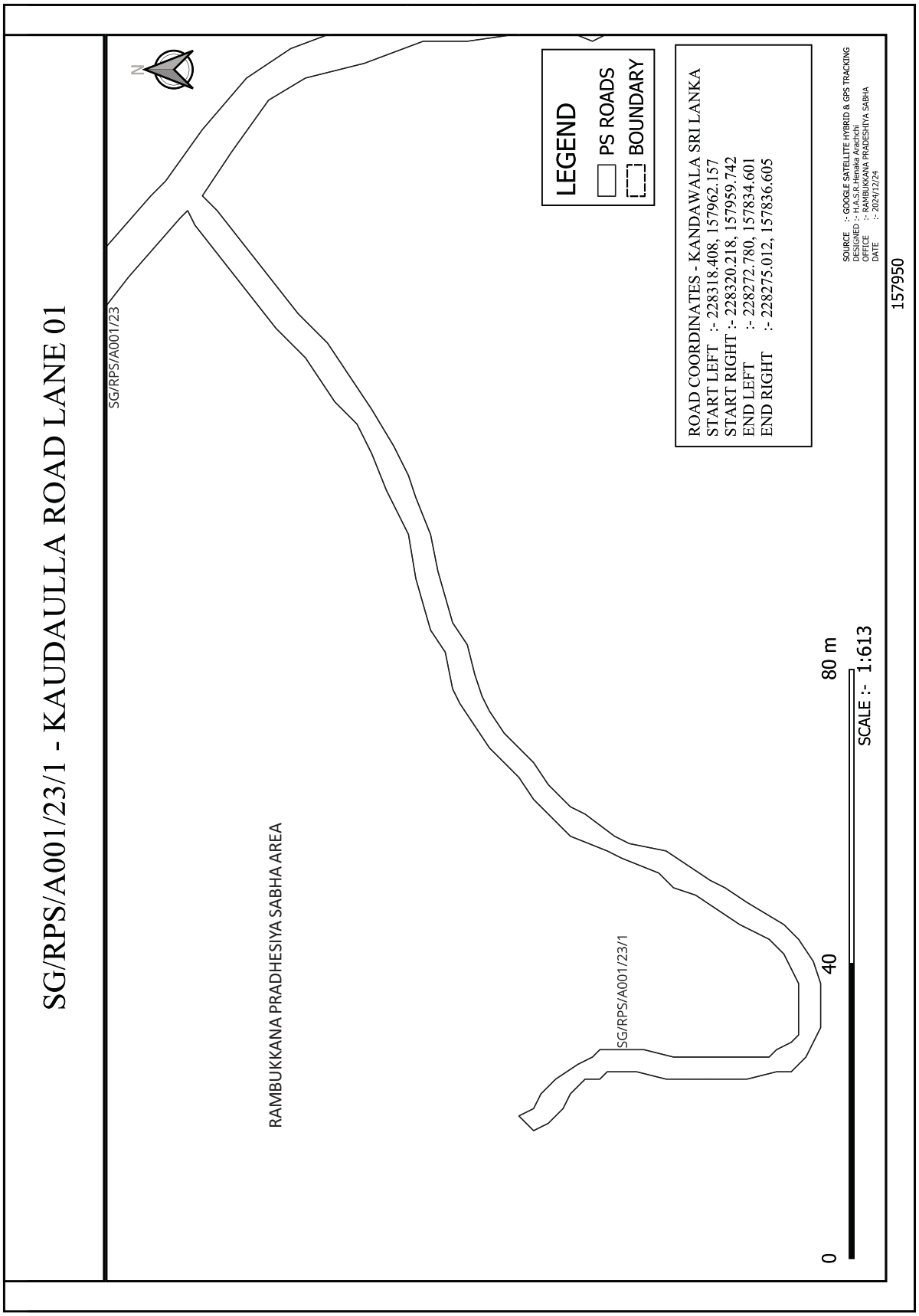
SG/RPS/A001/23/1 - KAUDAULLA ROAD LANE 01
SG/RPS/A001/23
RAMBUKKANA PRADHESIYA SABHA AREA
SG/RPS/A001/23/1
N
LEGEND
PS ROADS
BOUNDARY
ROAD COORDINATES - KANDAWALA SRI LANKA
START LEFT :- 228318.408, 157962.157
START RIGHT :- 228320.218, 157959.742
END LEFT :- 228272.780, 157834.601
END RIGHT :- 228275.012, 157836.605
SOURCE :- GOOGLE SATELLITE HYBRID & GPS TRACKING
DESIGNED :- H.A.S.K.Henaka Arachchi
OFFICE :- RAMBUKKANA PRADESHIYA SABHA
DATE :- 2024/12/24
157950
0
40
80 m
SCALE :- 1:613

RAMBUKKANA PRADHESIYA SABHA AREA

RAMBUKKANA PRADHESIYA SABHA AREA

RAMBUKKANA PRADHESIYA SABHA AREA

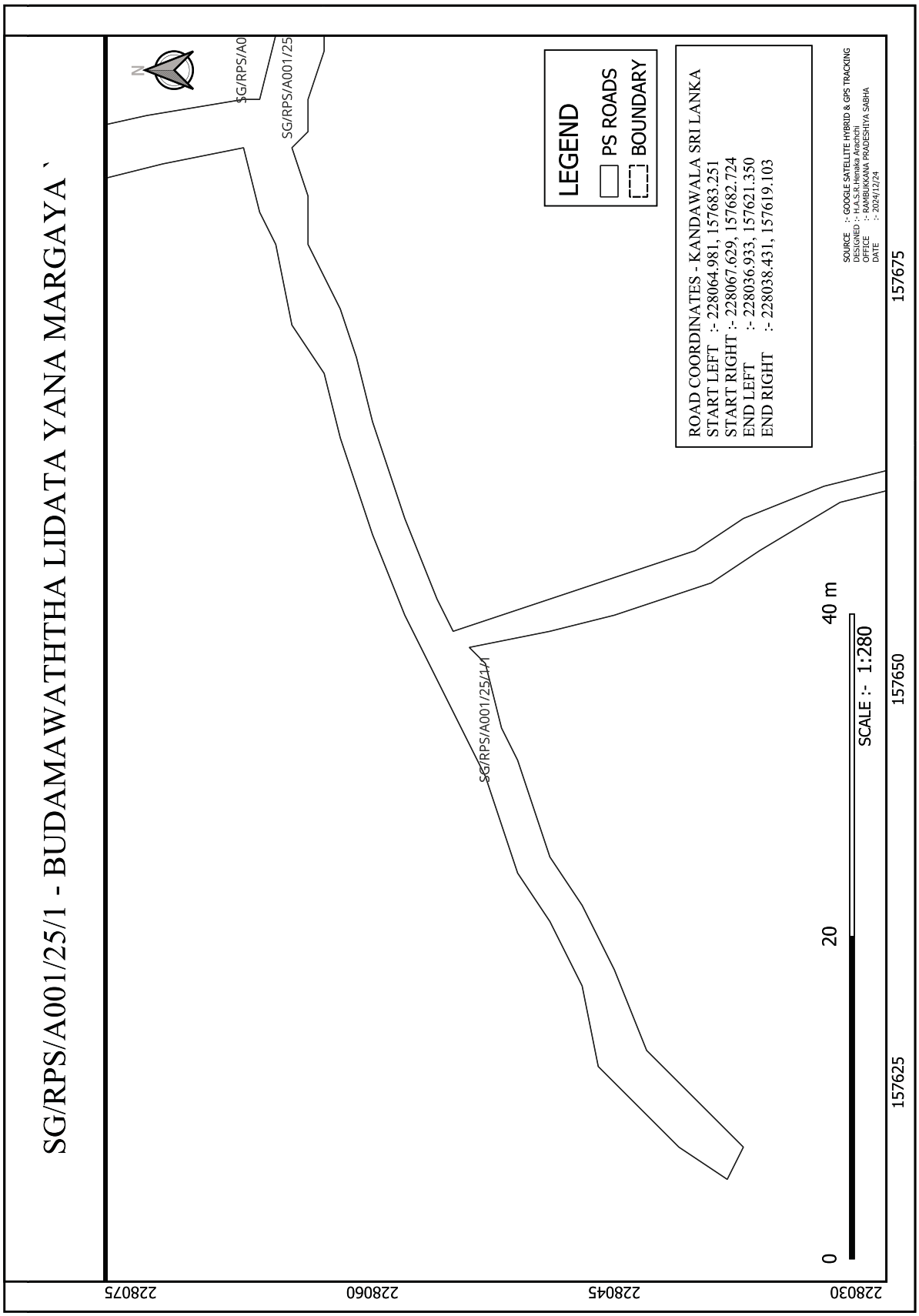
SG/RPS/A001/25/1 - BUDAMAWATHTHA LIDATA YANA MARGAYA `
N
SG/RPS/A0
SG/RPS/A001/25
SG/RPS/A001/25/1/1
LEGEND
PS ROADS
BOUNDARY
ROAD COORDINATES - KANDAWALA SRI LANKA
START LEFT :- 228064.981, 157683.251
START RIGHT :- 228067.629, 157682.724
END LEFT :- 228036.933, 157621.350
END RIGHT :- 228038.431, 157619.103
SOURCE :- GOOGLE SATELLITE HYBRID & GPS TRACKING
DESIGNED :- H.A.S.R.Henaka Arachchi
OFFICE :- RAMBUKKANA PRADESHIYA SABHA
DATE :- 2024/12/24
0
20
40 m
SCALE :- 1:280
157625
157650
157675
228030
228045
228060
228075

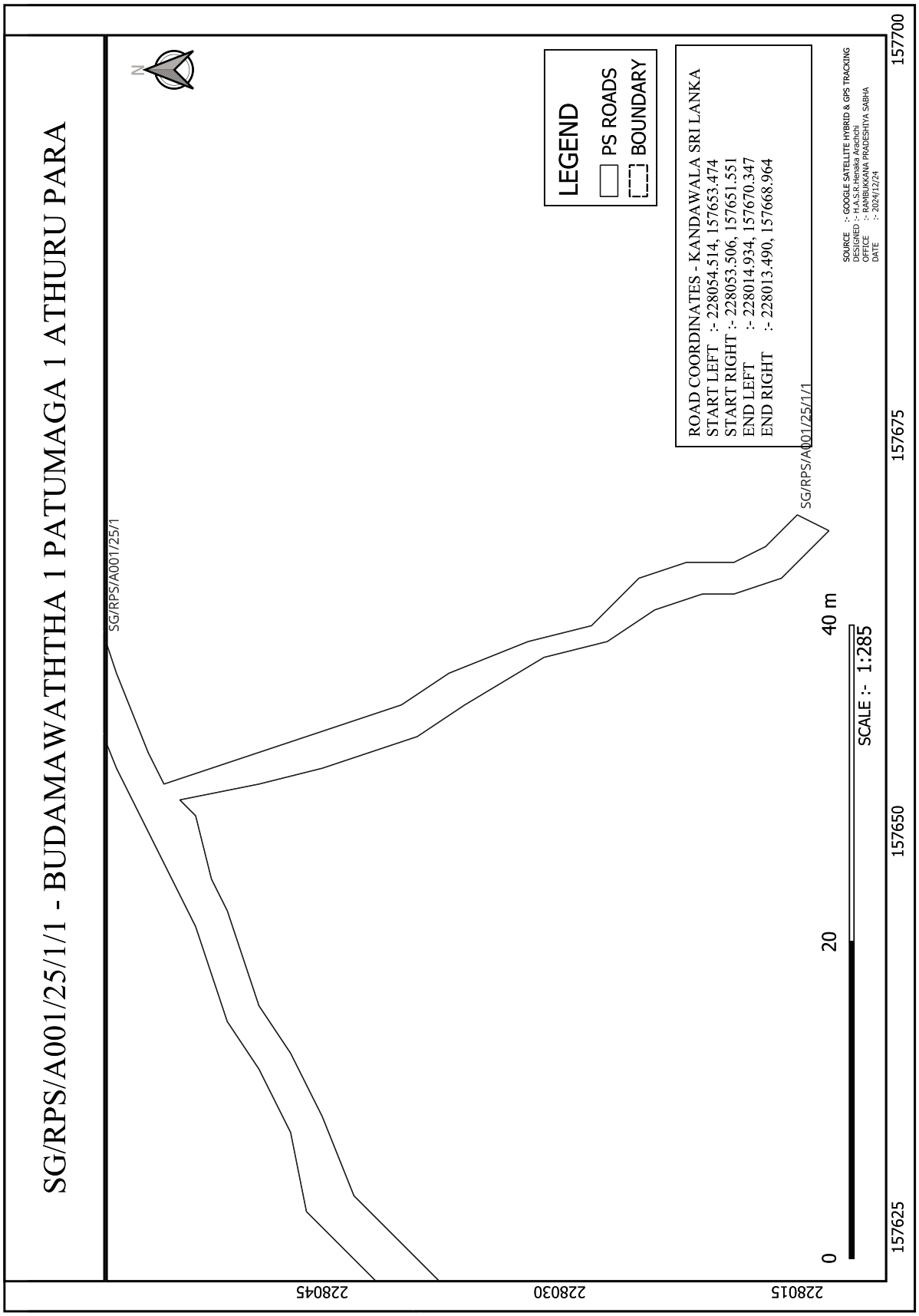
SG/RPS/A001/25/1/1 - BUDAMAWATHTHA 1 PATUMAGA 1 ATHURU PARA
N
LEGEND
PS ROADS
BOUNDARY
ROAD COORDINATES - KANDAWALA SRI LANKA
START LEFT :- 228054.514, 157653.474
START RIGHT :- 228053.506, 157651.551
END LEFT :- 228014.934, 157670.347
END RIGHT :- 228013.490, 157668.964
SG/RPS/A001/25/1/1
SG/RPS/A001/25/1
SOURCE :- GOOGLE SATELLITE HYBRID & GPS TRACKING
DESIGNED :- H.A.S.R.Henaka Arachchi
OFFICE :- RAMBUKKANA PRADESHIYA SABHA
DATE :- 2024/12/24
0
20
40 m
SCALE :- 1:285
157625
157650
157675
157700
228015
228030
228045

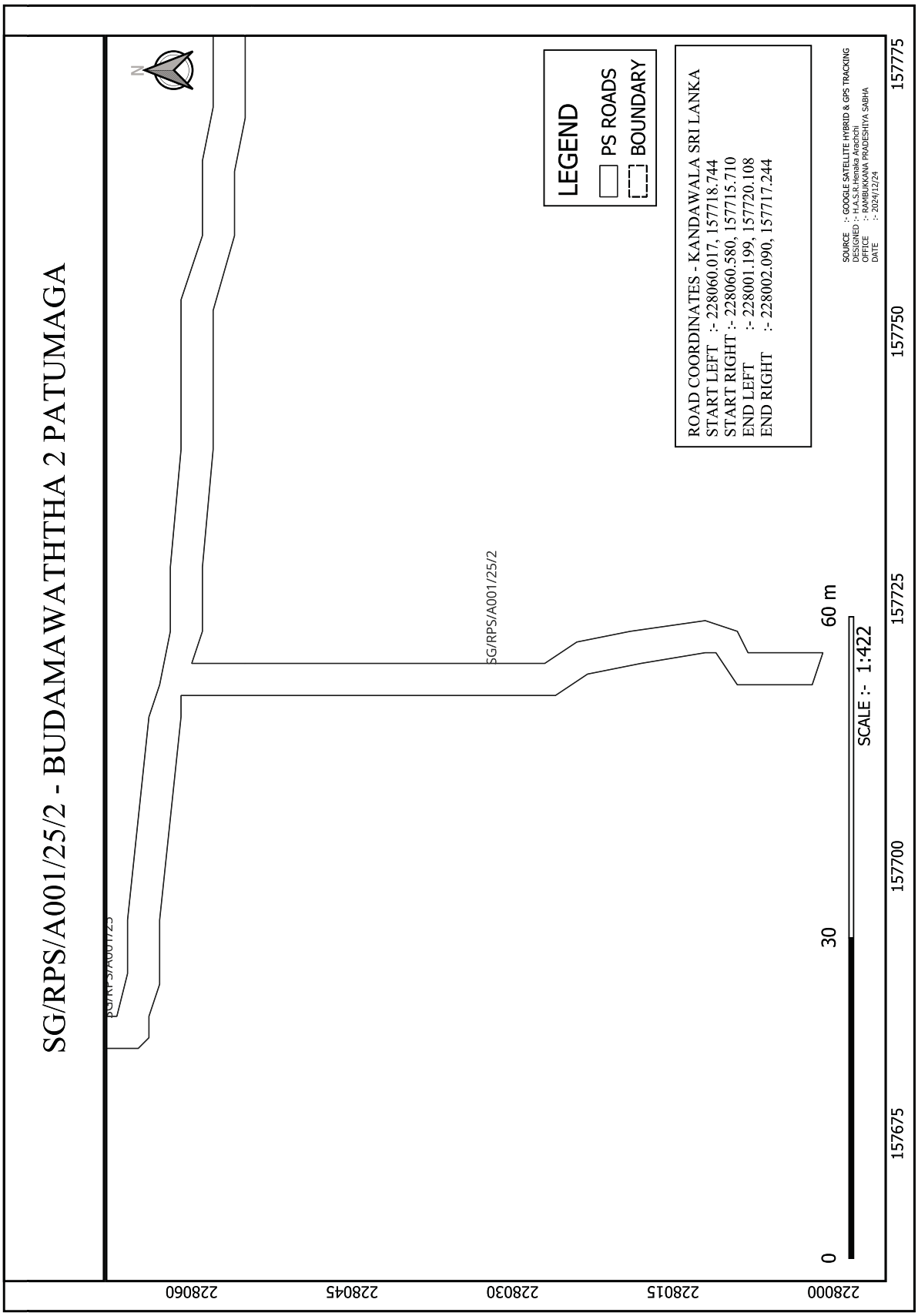
SG/RPS/A001/25/2 - BUDAMAWATHTHA 2 PATUMAGA
N
LEGEND
PS ROADS
BOUNDARY
ROAD COORDINATES - KANDAWALA SRI LANKA
START LEFT :- 228060.017, 157718.744
START RIGHT :- 228060.580, 157715.710
END LEFT :- 228001.199, 157720.108
END RIGHT :- 228002.090, 157717.244
SOURCE :- GOOGLE SATELLITE HYBRID & GPS TRACKING
DESIGNED :- H.A.S.R.Henaka Arachchi
OFFICE :- RAMBUKKANA PRADESHIYA SABHA
DATE :- 2024/12/24
SG/RPS/A001/25/2
SG/RPS/A001/25
0
30
60 m
SCALE :- 1:422
157675
157700
157725
157750
157775
228000
228015
228030
228045
228060

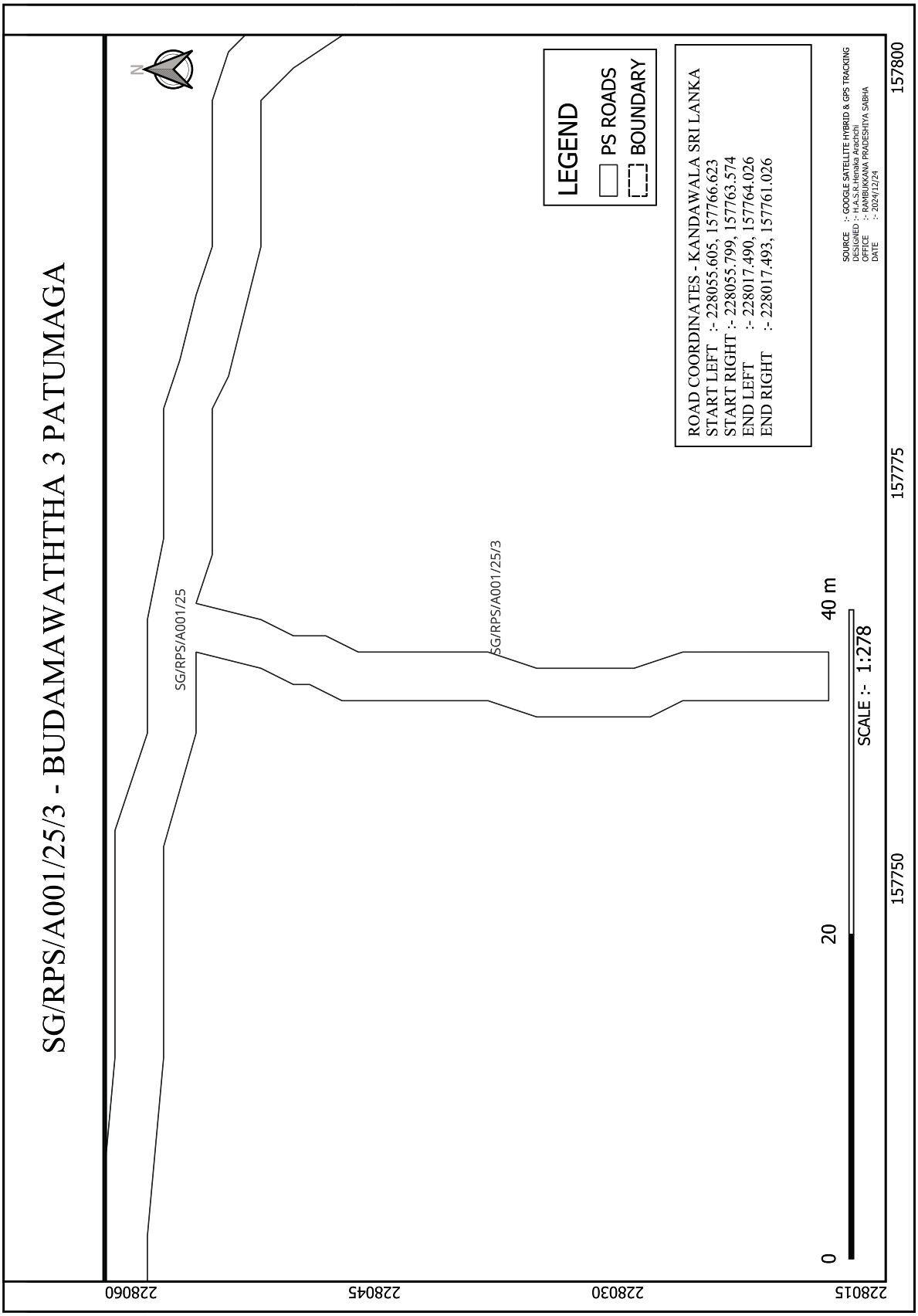
SG/RPS/A001/25/3 - BUDAMAWATHTHA 3 PATUMAGA
N
LEGEND
PS ROADS
BOUNDARY
ROAD COORDINATES - KANDAWALA SRI LANKA
START LEFT :- 228055.605, 157766.623
START RIGHT :- 228055.799, 157763.574
END LEFT :- 228017.490, 157764.026
END RIGHT :- 228017.493, 157761.026
SOURCE :- GOOGLE SATELLITE HYBRID & GPS TRACKING
DESIGNED :- H.A.S.R.Hemika Arachchi
OFFICE :- RAMBUKKANA PRADESHIYA SABHA
DATE :- 2024/12/24
SG/RPS/A001/25
SG/RPS/A001/25/3
0
20
40 m
SCALE :- 1:278
157750
157775
157800
228060
228045
228030
228015

[redacted]

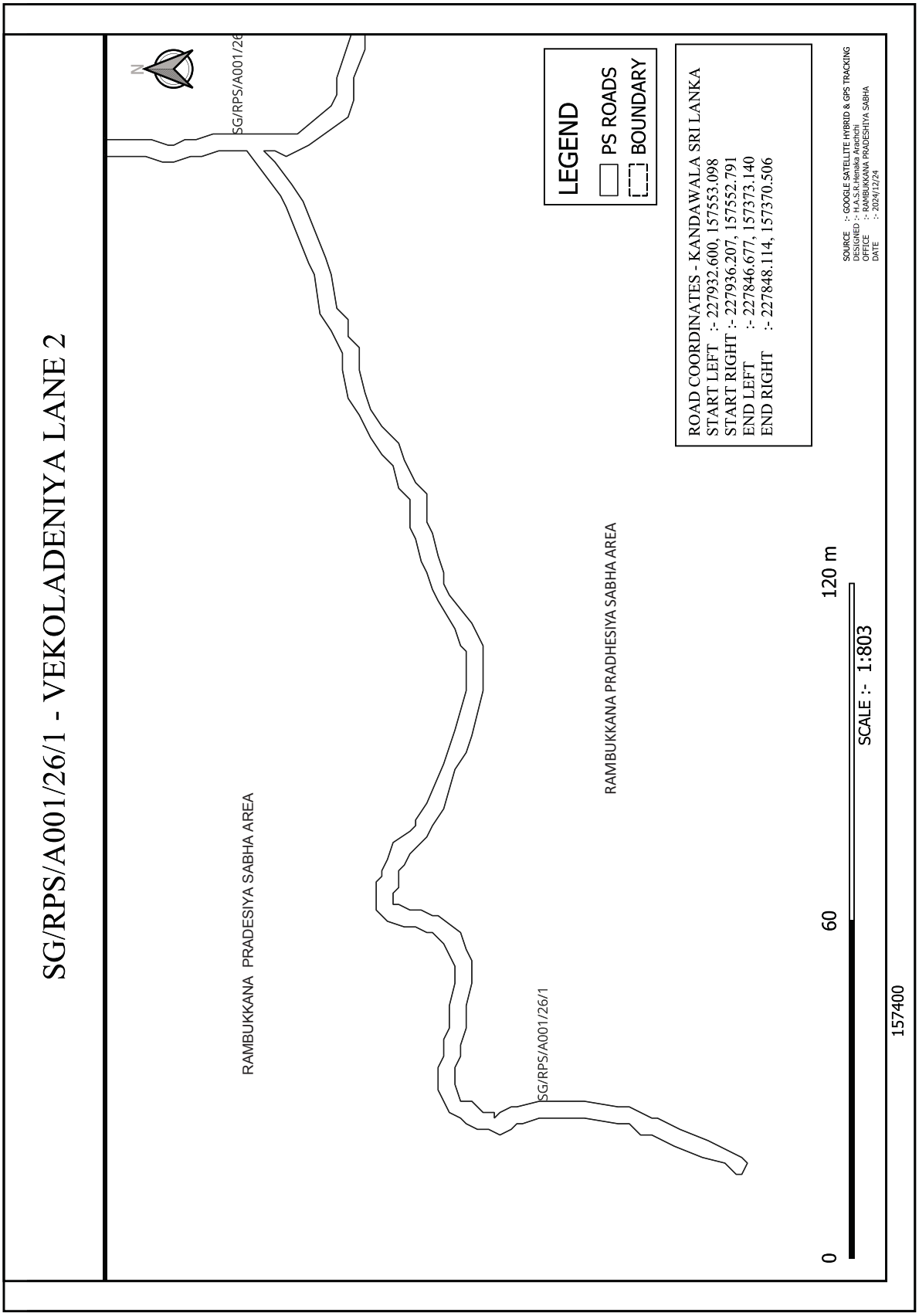
SG/RPS/A001/26/1 - VEKOLADENIYA LANE 2
N
SG/RPS/A001/26
RAMBUKKANA PRADESIYA SABHA AREA
RAMBUKKANA PRADHESIYA SABHA AREA
SG/RPS/A001/26/1
LEGEND
PS ROADS
BOUNDARY
ROAD COORDINATES - KANDAWALA SRI LANKA
START LEFT :- 227932.600, 157553.098
START RIGHT :- 227936.207, 157552.791
END LEFT :- 227846.677, 157373.140
END RIGHT :- 227848.114, 157370.506
SOURCE :- GOOGLE SATELLITE HYBRID & GPS TRACKING
DESIGNED :- H.A.S.K.Herath Arachchi
OFFICE :- RAMBUKKANA PRADESIYA SABHA
DATE :- 2024/12/24
0
60
120 m
SCALE :- 1:803
157400

SG/RPS/A001/26/2-VEKOLADENIYA LANE 01

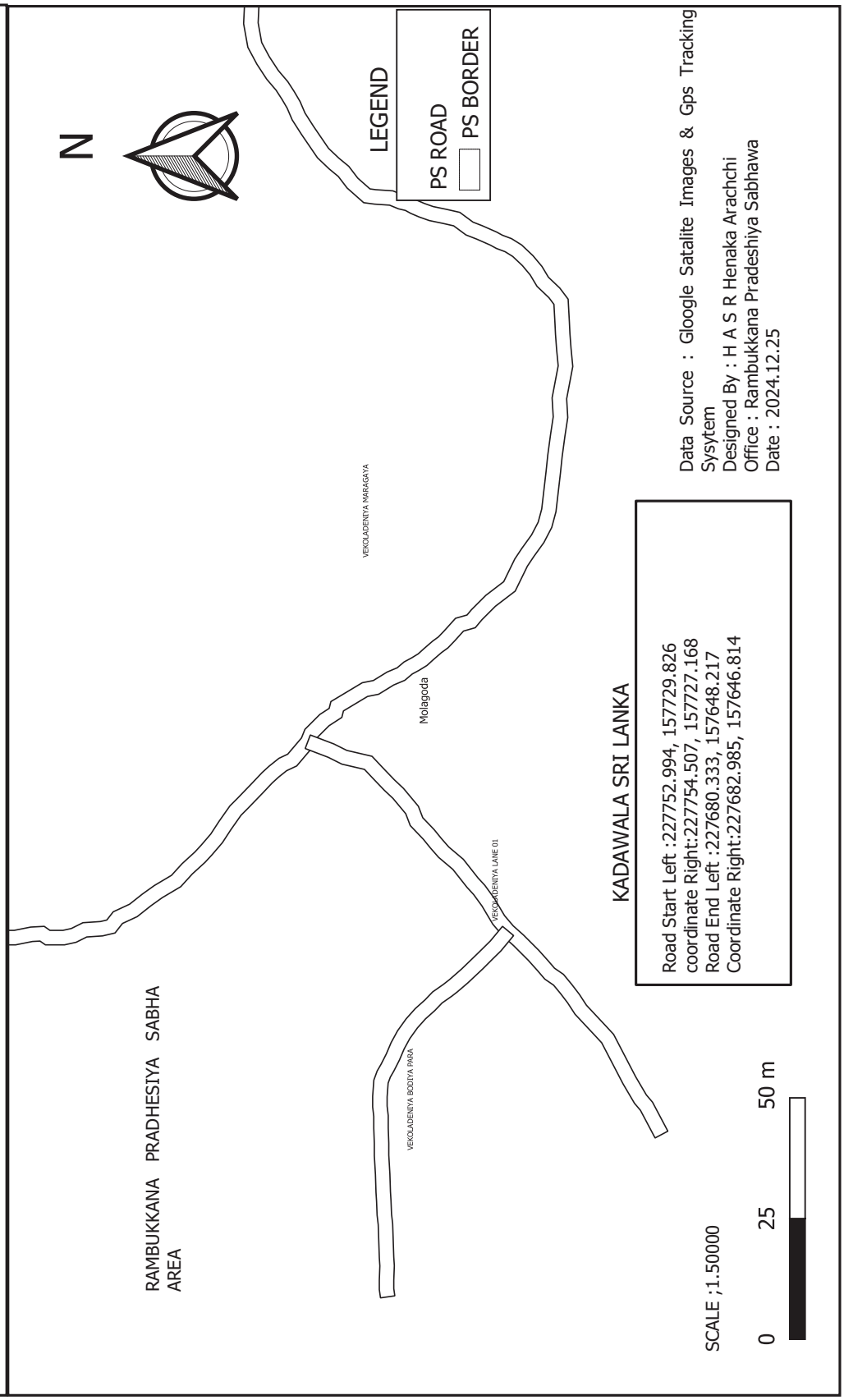

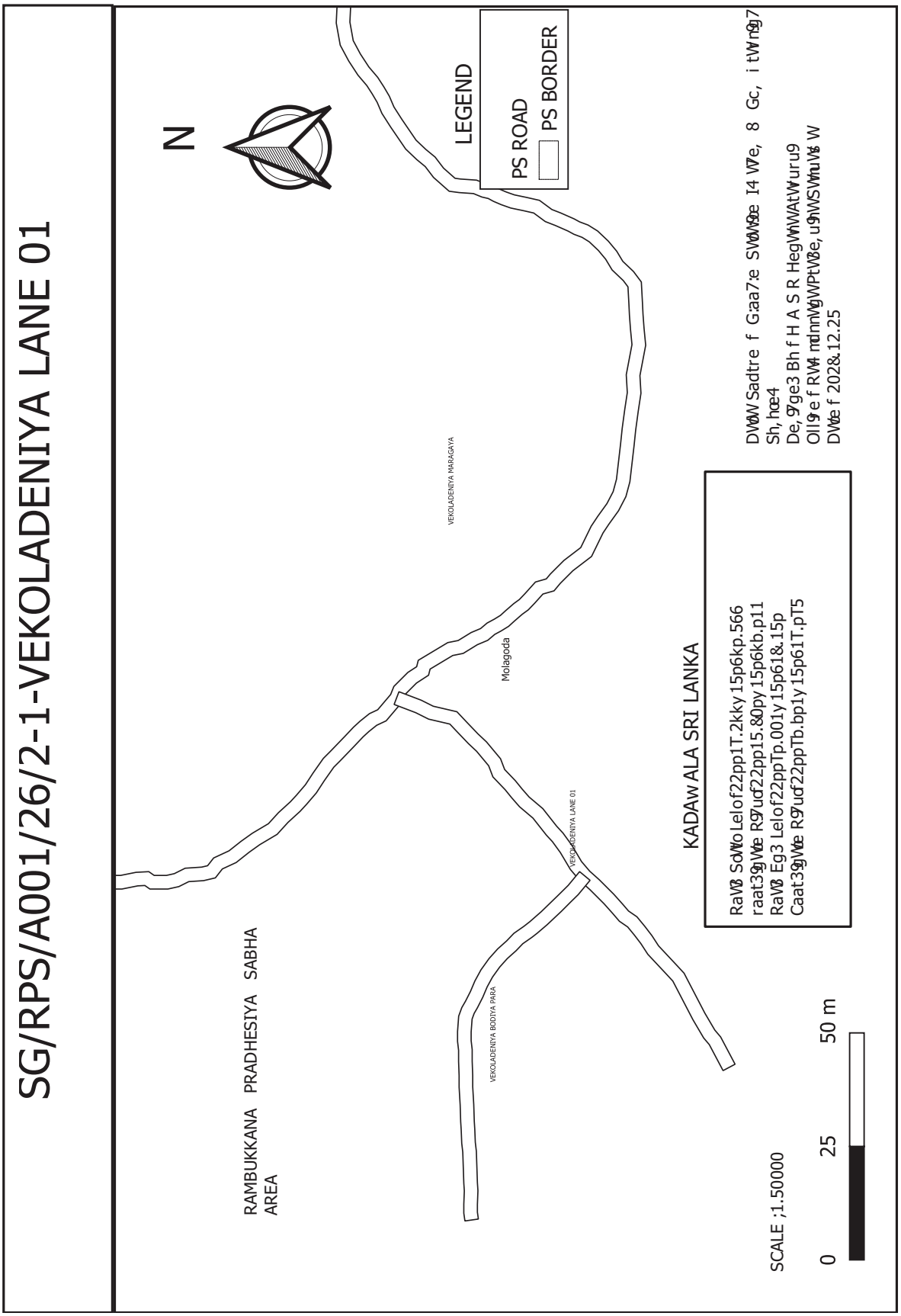
SG/RPS/A001/26/2-1-VEKOLADENIYA LANE 01
N
LEGEND
PS ROAD
PS BORDER
VEKOLADENIYA MARAGAYA
Molagoda
VEKOLADENIYA LANE 01
VEKOLADENIYA BODIYA PARA
RAMBUKKANA PRADHESIYA SABHA AREA
KADAw ALA SRI LANKA
SCALE ;1.50000
0
25
50 m

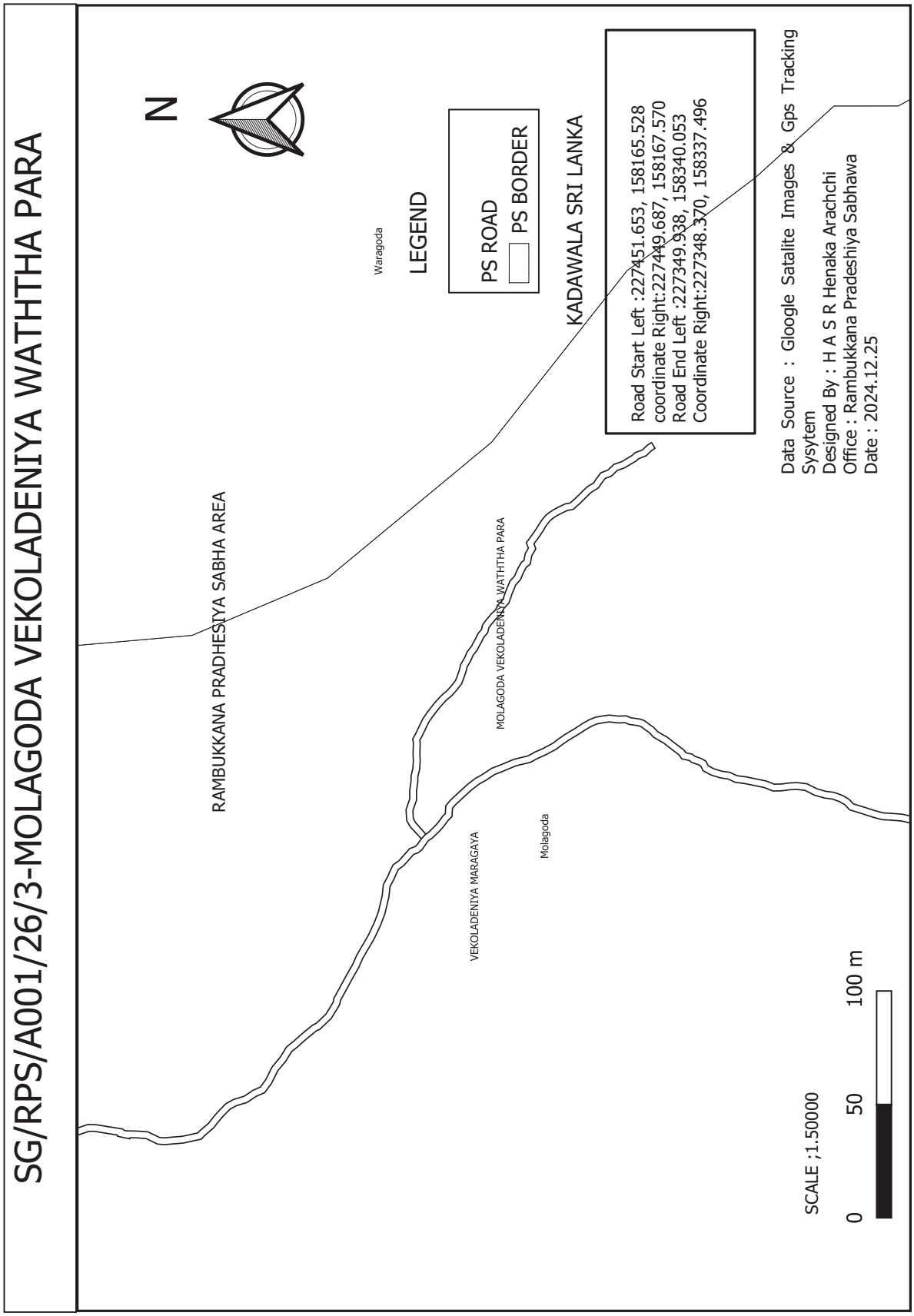
SG/RPS/A001/26/3-MOLAGODA VEKOLADENIYA WATHTHA PARA
N
Waragoda
LEGEND
PS ROAD
PS BORDER
KADAWALA SRI LANKA
Road Start Left :227451.653, 158165.528
coordinate Right:227449.687, 158167.570
Road End Left :227349.938, 158340.053
Coordinate Right:227348.370, 158337.496
Data Source : Gloogle Satalite Images & Gps Tracking Sysytem
Designed By : H A S R Henaka Arachchi
Office : Rambukkana Pradeshiya Sabhawa
Date : 2024.12.25
RAMBUKKANA PRADHESIYA SABHA AREA
MOLAGODA VEKOLADENIYA WATHTHA PARA
VEKOLADENIYA MARAGAYA
Molagoda
SCALE ;1.50000
0
50
100 m

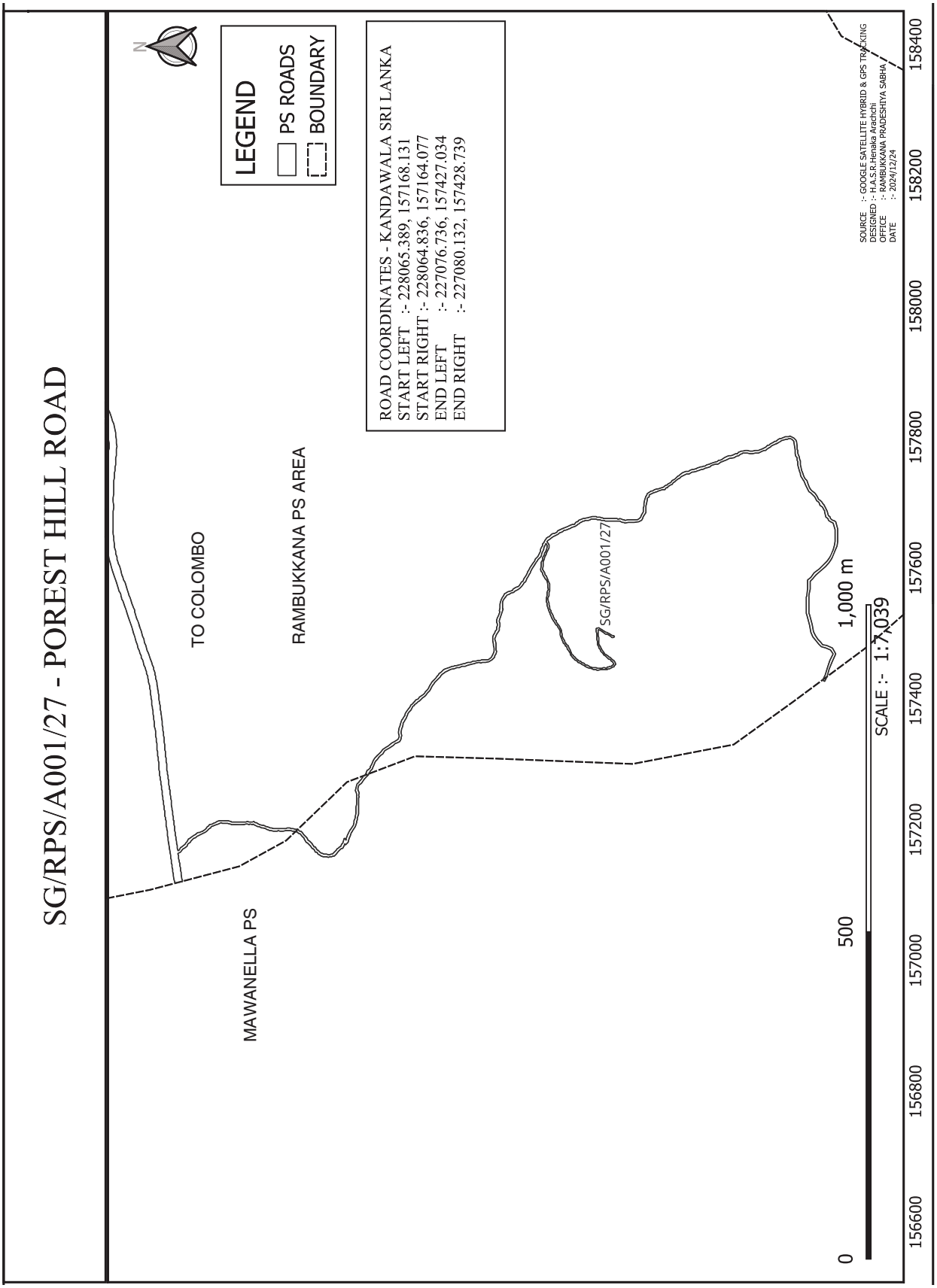
SG/RPS/A001/27 - PORESTHILL ROAD
LEGEND
PS ROADS
BOUNDARY
ROAD COORDINATES - KANDAWALA SRI LANKA
START LEFT :- 228065.389, 157168.131
START RIGHT :- 228064.836, 157164.077
END LEFT :- 227076.736, 157427.034
END RIGHT :- 227080.132, 157428.739
TO COLOMBO
RAMBUKKANA PS AREA
MAWANELLA PS
SG/RPS/A001/27
SCALE :- 1:7,039
0
500
1,000 m
SOURCE :- GOOGLE SATELLITE HYBRID & GPS TRACKING
DESIGNED :- H.A.S.R.Henaka Arachchi
OFFICE :- RAMBUKKANA PRADESHIYA SABHA
DATE :- 2024/12/24
156600
156800
157000
157200
157400
157600
157800
158000
158200
158400

SG/RPS/A001/27/1-POREST HILL LANE 1

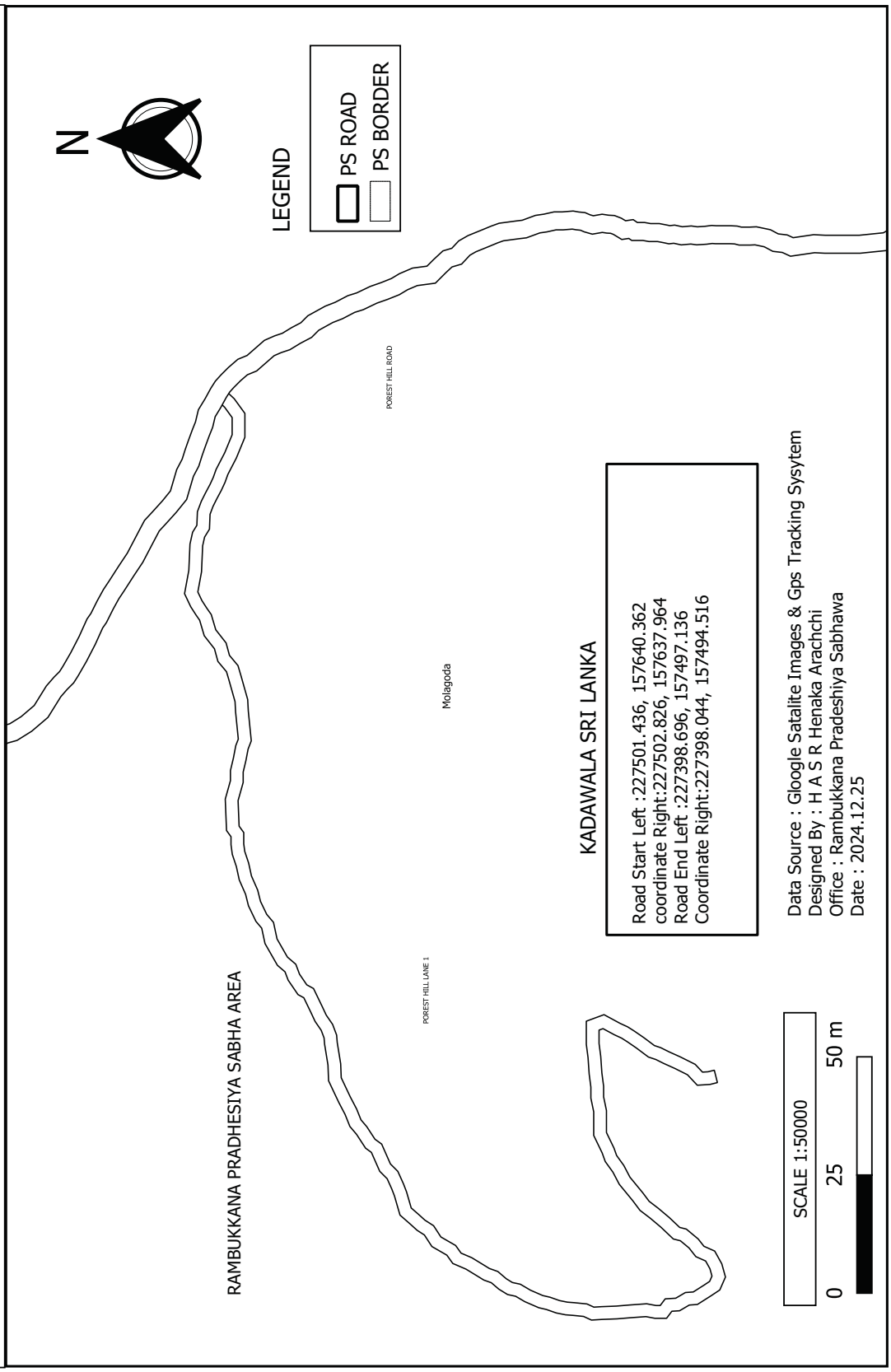

EOG 01-0107